Bulletin d'estimation du risque d'avalanche
(valable en dehors des pistes balisées et ouvertes)

MASSIF : Aure Louron

Rédigé le lundi 30 mars 2026 à 17h

Estimation des risques pour le : MARDI 31 MARS

FORMATION DE NOUVELLES PLAQUES, REPOSANT SUR UN MANTEAU PAS ENCORE STABILISÉ EN ALTITUDE

3

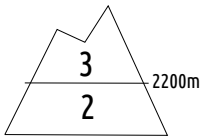

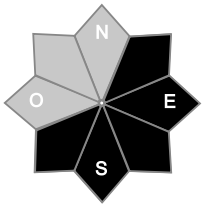

Au-dessus de 2200m indice de risque marqué, plus bas indice limité.

Départs spontanés : Départs ponctuels en pentes raides

Déclenchements provoqués : Formation de plaques, reposant localement sur des instabilités au-dessus de 2200m

Indices de risque : 5 très fort - 4 fort - 3 marqué - 2 limité - 1 faible -- En noir : les pentes les plus dangereuses

Stabilité du manteau neigeux

Situation avalancheuse typique : neige ventée

Déclenchements provoqués :
Des plaques se forment dans les expositions **à l'abri du vent de nord à nord-ouest**. Elles se situent plutôt à proximité des cols et crêtes, formées par un vent modéré. Elles sont probablement moins fréquentes vers le fond de chaîne où les quantités de neige attendues sont moins importantes
- Sous 2200m, elles se forment sur un manteau humidifié puis regelé, et engendrent des avalanches de petite taille en général, des moyennes deviennent possibles en journée au fil des chutes de neige.
- **Au-dessus de 2200m, les plaques sont plus épaisses et plus facilement déclenchables**, reposant dans les zones déventées sur des accumulations encore instables formées par le vent fort de dimanche, qu'elles ont tendance à masquer visuellement. Les nouvelles plaques étant encore assez peu épaisses, il est possible de détecter les accumulations de dimanche par le changement de sous-couche, passant de très dure à plus meuble où le déclenchement devient plus facile.

Départs spontanés :
Principalement des départs ponctuels au fil des chutes de neige, dans les pentes raides, préférentiellement dans les versants sous le vent. En général de petite taille, des moyennes sont possibles au-dessus de 2300m.

Qualité de la neige

Enneigement : Correct pour la saison au-dessus de 1800m, mais restant assez maigre en versants exposés aux vents de nord à ouest. Les nouvelles chutes de neige blanchissent les sols vers 1300m mardi matin
État de la neige : Mardi matin, quelques centimètres de neige fraîche, peu ventée, couche s'épaississant en journée, recouvrant un manteau en général printanier sous 2200m, assez bien regelé. Plus haut, la neige fraîche recouvre un manteau irrégulier alternant surfaces dures pelées par le vent et accumulations plus meubles.

Aperçu météo pour le mardi 31 mars

	nuit	matin	après-midi	soir
	Relief souvent bouché, neige faible en début de matinée, éclaircies à la mi-journée, reprise des précipitations l'après-midi, un peu plus marquées.			
Pluie-Neige	1 200 m	1 400 m	1 300 m	1 200 m
Iso 0 °C	1 500 m	1 700 m	1 700 m	1 500 m
Vent 1500 m	25 km/h	25 km/h	30 km/h	30 km/h
Vent 3000 m	75 km/h	70 km/h	75 km/h	75 km/h

Épaisseur de neige hors-piste

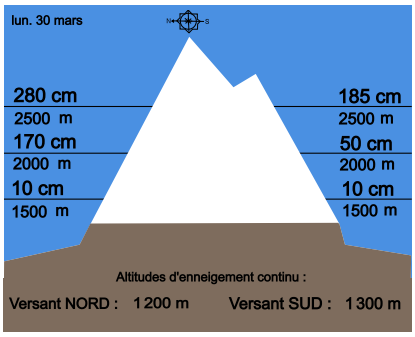

Précipitations à 1800 m

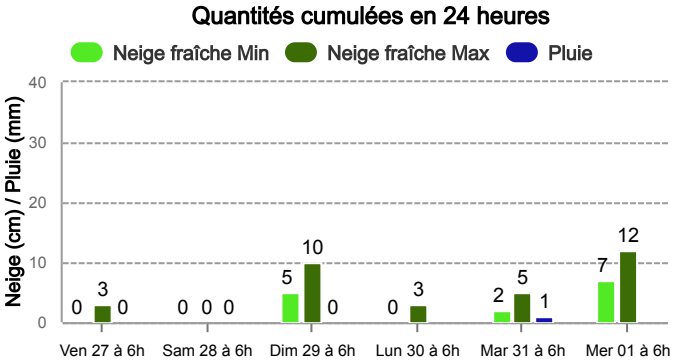

Tendance du mercredi 01 avril

3 **Indice de risque marqué**

Risque en hausse : chutes de neige en journée de mercredi, cumuls possiblement importants

Pour consulter la vigilance en cours, veuillez vous rendre sur le site https://vigilance.meteofrance.fr/fr

Météo-France - 73 avenue de Paris, 94165 Saint-Mandé cedex - Contact : contact@meteo.fr

Rédigé par Météo-France avec la contribution des observateurs du réseau nivo-météorologiques. Partenariat : ANMSM (Maires de Stations de Montagne), DSF (Domaines Skiables de France), ADSP (Directeurs de Pistes et de la Sécurité des Stations de Sports d'Hiver) et autres acteurs de la montagne.

Bulletin neige & avalanches par téléphone au **0 892 68 10 20** Service 0,35 € / min + prix appel

RÉPUBLIQUE FRANÇAISE
Liberté Égalité Fraternité

METEO FRANCE
À VOS CÔTÉS, DANS UN CLIMAT QUI CHANGE

Bulletin d'estimation du risque d'avalanche

(valable en dehors des pistes balisées et ouvertes)

MASSIF : Aure Louron

Rédigé le lundi 30 mars 2026 à 17h

Conditions nivo-météo des 7 derniers jours

	mar. 24/03				mer. 25/03				jeu. 26/03				ven. 27/03				sam. 28/03				dim. 29/03				lun. 30/03			
	03h	09h	15h	21h	03h	09h	15h	21h	03h	09h	15h	21h	03h	09h	15h	21h	03h	09h	15h	21h	03h	09h	15h	21h	03h	09h	15h	21h
Météo																												
Vent (km/h)	35	20	20	60	70	70	75	80	90	80	75	80	85	85	70	55	55	35	50	75	100	105	90	85	80	65	80	65
à 3000m																												
Vent (km/h)	5	5	10	10	10	20	25	25	35	30	25	30	15	15	25	10	5	15	25	40	50	55	50	25	15	15	30	30
à 1500m																												

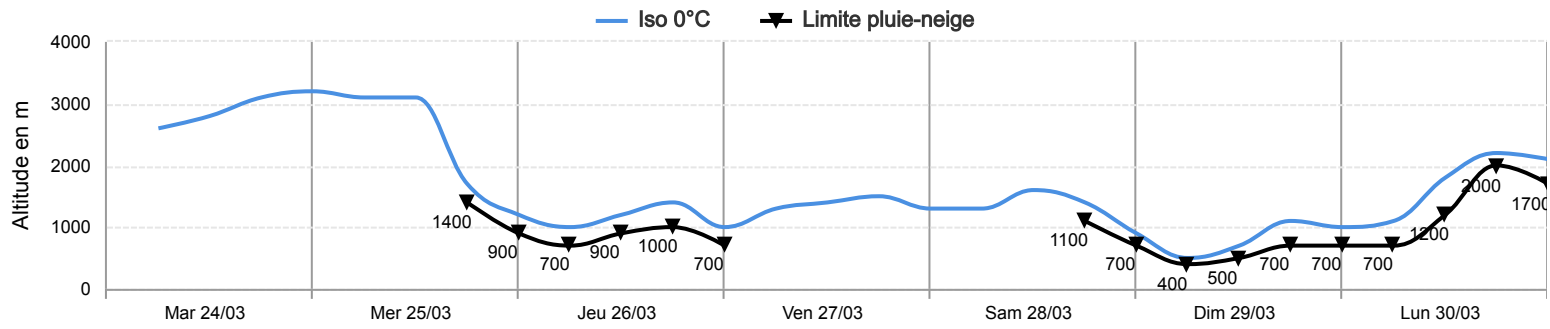

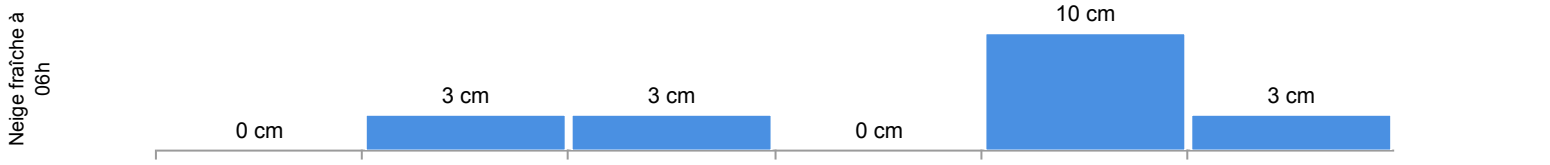

Risque d'avalanche	mar. 24/03	mer. 25/03	jeu. 26/03	ven. 27/03	sam. 28/03	dim. 29/03	lun. 30/03
	2	2	2	2	2	3	3

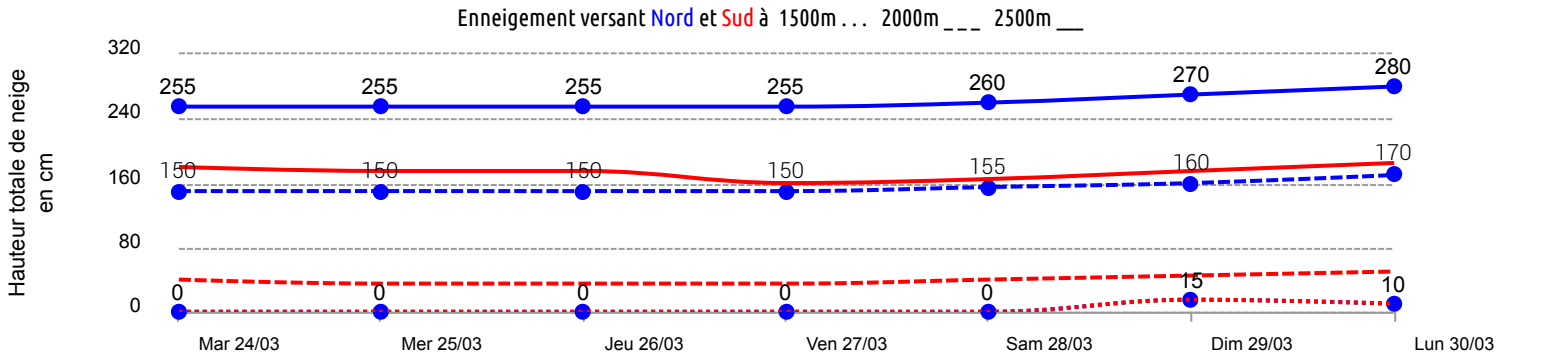

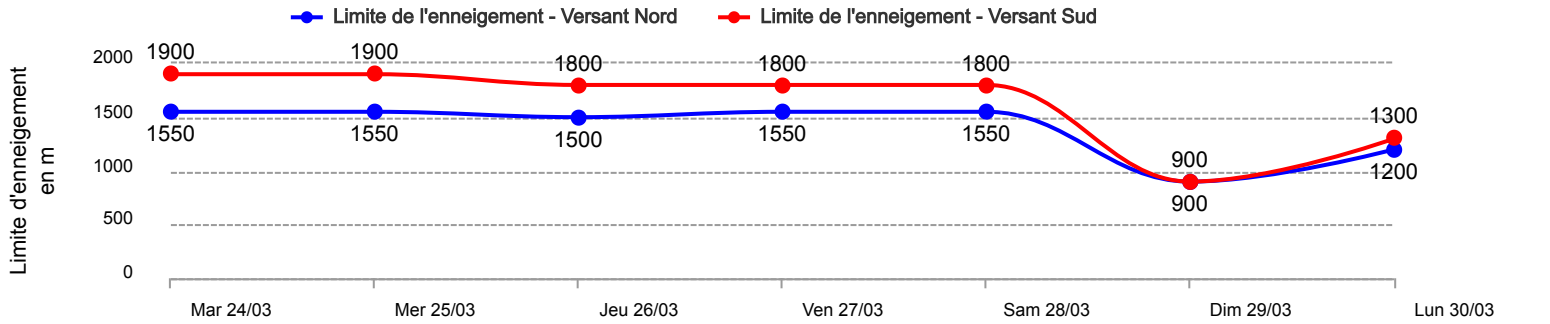

Pour consulter la vigilance en cours, veuillez vous rendre sur le site https://vigilance.meteofrance.fr/fr

Météo-France - 73 avenue de Paris, 94165 Saint-Mandé cedex - Contact : contact@meteo.fr

Rédigé par Météo-France avec la contribution des observateurs du réseau nivo-météorologiques. Partenariat : ANMSM (Maires de Stations de Montagne), DSF (Domaines Skiables de France), ADSP (Directeurs de Pistes et de la Sécurité des Stations de Sports d'Hiver) et autres acteurs de la montagne.

Bulletin neige & avalanches par téléphone au
0 892 68 10 20 Service 0,35 € / min + prix appel