# Bulletin d'estimation du risque d'avalanche
(valable en dehors des pistes balisées et ouvertes)

# MASSIF : Belledonne

Rédigé le lundi 30 mars 2026 à 17h

## Estimation des risques pour le : MARDI 31 MARS

**NOUVELLES INSTABILITES DANS LA NEIGE FRAICHE VENTEE**

3

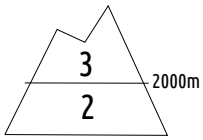


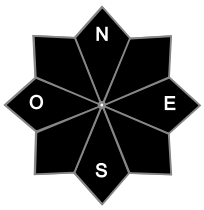


Au-dessus de 2000m indice de risque marqué, plus bas indice limité.

**Départs spontanés :** Quelques départs spontanés sont possibles sous les chutes de neige, puis mardi dans les pentes sous le vent.

**Déclenchements provoqués :** Nouvelles plaques formées par le vent dans la neige fraîche

Indices de risque : 5 très fort - 4 fort - 3 marqué - 2 limité - 1 faible -- En noir : les pentes les plus dangereuses

## Stabilité du manteau neigeux

**Situation avalancheuse typique :** neige ventée

Nouveau passage perturbé apportant 5 à 15cm de neige fraîche sur le massif d'ici mardi matin. Ces chutes de neige s'accompagnent d'un vent de secteur Nord parfois tempétueux.

**Déclenchements provoqués :** De nouvelles plaques se forment sous ces chutes de neige nocturnes, puis sous le vent de Nord en journée de mardi. Elles peuvent se retrouver en tout versant, mais sont généralement plus nombreuses, plus réactives et plus épaisses en large Sud, où la neige des derniers jours était parfois restée poudreuse et où la neige s'accumule sous l'effet du vent. Elles sont plutôt dures à déclencher lorsqu'elles sont en neige dure / cartonnée (souvent près des crêtes), mais plus réactives lorsqu'elles sont en neige plus légère (en s'éloignant des crêtes / en secteurs moins ventés).
Les plaques sont un peu plus rares en large Nord, car ces pentes sont plus souvent dégarnies suite aux épisodes répétés de vent de Nord.
Observables : transport en cours, zones d'accumulations, congères, signes du travail par le vent...

**Départs spontanés :** Principalement en versants Sud, des ruptures de plaques ( de tailles petites à moyennes) sont possibles dans les pentes qui se chargent sous le vent de Nord. Le vent étant particulièrement fort, ces ruptures peuvent se produire même loin des crêtes. Sous les éclaircies en journée, quelques coulées de petites tailles sont possibles en pentes raides ensoleillées. Départs seulement sous les rochers, en secteurs peu ventés (donc plutôt à basse altitude).

**Autres :** Suite au faible épisode de pluie vitrifiante de lundi, des surfaces verglacées peuvent localement apparaître près des crêtes et dans les pentes exposées au vent de Nord, rendant la progression délicate sans équipement adapté.

## Qualité de la neige

**Qualification de l'enneigement :** L'enneigement est bon à basse altitude, et même très bon dés 1800 / 2000m mais avec des répartitions assez hétérogènes à cause du vent. Peu de sous couche sous 1700m en plein Sud.
**Limites skiables :** Vers 1000 / 1200m selon le versant, avec prudence en Sud / sous les sapins

**Qualité de la neige mardi :** Neige de qualité très variable sur le massif. La plupart du temps, neige fraîche travaillée ou cartonnée par le vent dans de nombreux endroits. Les crêtes et pentes exposées au vent de Nord sont souvent dégarnies, et présentent parfois une couche de glace vive, formée par un épisode de pluie vitrifiante ce lundi après-midi. En versants Sud, dans certaines combes abritées (vallée des Villards, Allemond) et en bas de pentes / secteurs forestiers, la neige est parfois restée poudreuse avec encore du bon ski par endroits.
En journée, la neige de surface s'humidifie au soleil, dans les pentes protégées du vent.

## Aperçu météo pour le mardi 31 mars

| | nuit | matin | après-midi | soir |
|---|---|---|---|---|
| | | | | |

Assez nuageux en matinée, puis belles éclaircies en journée, sous un vent de Nord sensible voire très fort en altitude.

| | | | | |
|---|---|---|---|---|
| **Pluie-Neige** | 1 000 m | | | |
| **Iso 0 °C** | 1 400 m | 1 200 m | 1 500 m | 1 200 m |
| **Vent 2000 m** | ↙ 60 km/h | ↙ 60 km/h | ↙ 60 km/h | ↙ 60 km/h |
| **Vent 3000 m** | ↓ 90 km/h | ↙ 100 km/h | ↙ 95 km/h | ↙ 95 km/h |

## Épaisseur de neige hors-piste

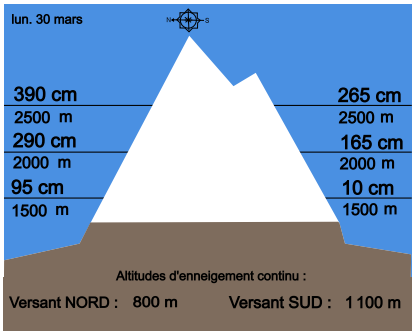


## Précipitations à 1800 m

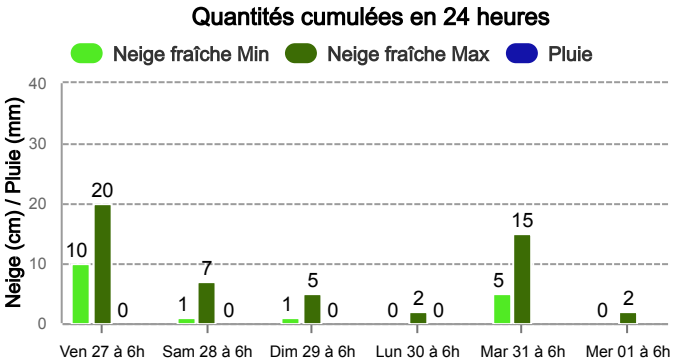


## Tendance du mercredi 01 avril

**Indice de risque limité**

Mercredi, le risque est en légère baisse. Le vent, encore fort en matinée, faiblit en journée. On devrait profiter de belles éclaircies avant le retour d'un temps plus nuageux l'après-midi, le tout dans une atmosphère toujours fraîche.

Pour consulter la vigilance en cours, veuillez vous rendre sur le site https://vigilance.meteofrance.fr/fr

Météo-France - 73 avenue de Paris, 94165 Saint-Mandé cedex - Contact : contact@meteo.fr

Rédigé par Météo-France avec la contribution des observateurs du réseau nivo-météorologiques. Partenariat : ANMSM (Maires de Stations de Montagne), DSF (Domaines Skiables de France), ADSP (Directeurs de Pistes et de la Sécurité des Stations de Sports d'Hiver) et autres acteurs de la montagne.

Bulletin neige & avalanches par téléphone au
0 892 68 10 20 Service 0,35 € / min + prix appel

RÉPUBLIQUE FRANÇAISE
*Liberté Égalité Fraternité*

METEO FRANCE
À VOS CÔTÉS, DANS UN CLIMAT QUI CHANGE

# Bulletin d'estimation du risque d'avalanche
## (valable en dehors des pistes balisées et ouvertes)
# MASSIF : Belledonne

Rédigé le lundi 30 mars 2026 à 17h

## Conditions nivo-météo des 7 derniers jours

| | mar. 24/03 | | | | mer. 25/03 | | | | jeu. 26/03 | | | | ven. 27/03 | | | | sam. 28/03 | | | | dim. 29/03 | | | | lun. 30/03 | | | |
|---|---|---|---|---|---|---|---|---|---|---|---|---|---|---|---|---|---|---|---|---|---|---|---|---|---|---|---|---|
| | 03h | 09h | 15h | 21h | 03h | 09h | 15h | 21h | 03h | 09h | 15h | 21h | 03h | 09h | 15h | 21h | 03h | 09h | 15h | 21h | 03h | 09h | 15h | 21h | 03h | 09h | 15h | 21h |
| Météo | | | | | | | | | | | | | | | | | | | | | | | | | | | | |
| Vent (km/h) | 20 | 25 | 15 | 15 | 25 | 55 | 80 | 100 | 95 | 90 | 80 | 80 | 90 | 70 | 40 | 35 | 40 | 50 | 50 | 35 | 45 | 35 | 20 | 25 | 40 | 60 | 70 | 85 |
| à 3000m | | | | | | | | | | | | | | | | | | | | | | | | | | | | |
| Vent (km/h) | 15 | 10 | 10 | 10 | 10 | 30 | 55 | 70 | 65 | 60 | 65 | 60 | 55 | 50 | 35 | 25 | 30 | 40 | 40 | 25 | 40 | 25 | 15 | 20 | 30 | 50 | 60 | 65 |
| à 2000m | | | | | | | | | | | | | | | | | | | | | | | | | | | | |

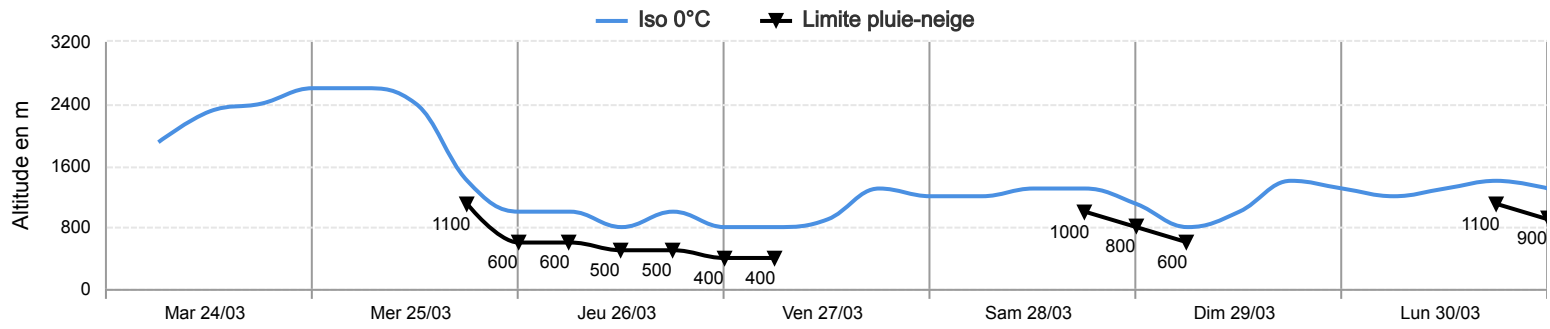


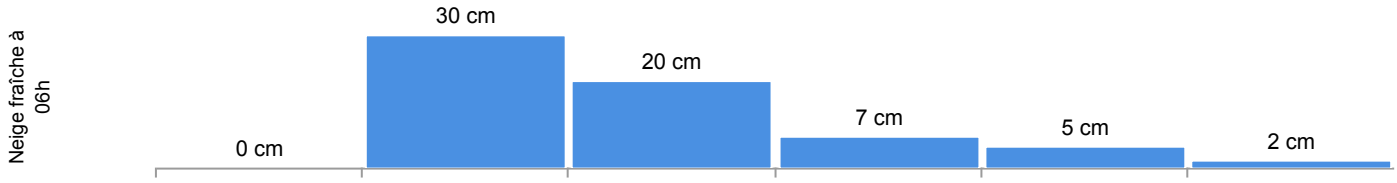


| Risque d'avalanche | mar. 24/03 | mer. 25/03 | jeu. 26/03 | ven. 27/03 | sam. 28/03 | dim. 29/03 | lun. 30/03 |
|---|---|---|---|---|---|---|---|
| | 2 | 3 | 4 | 3 | 3 | 2 | 2 |

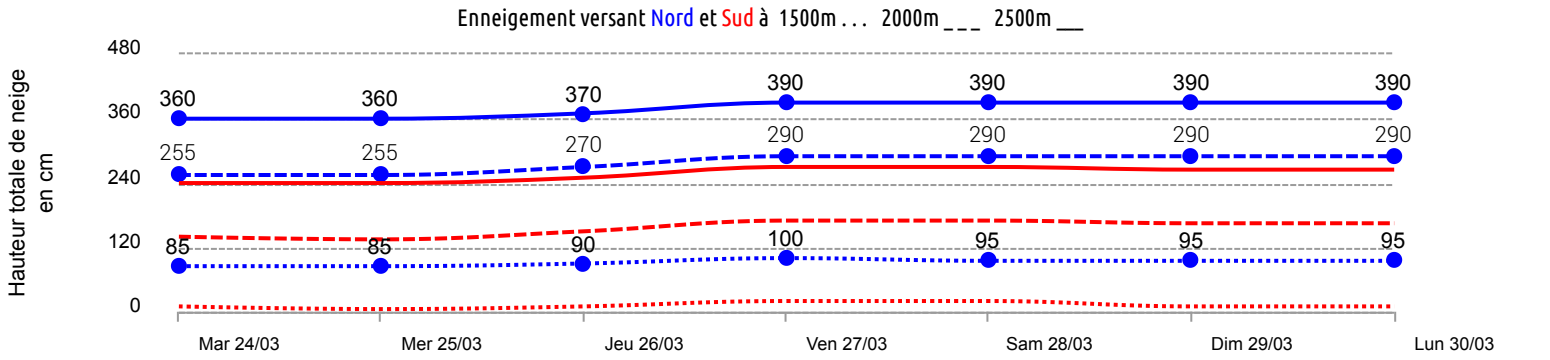


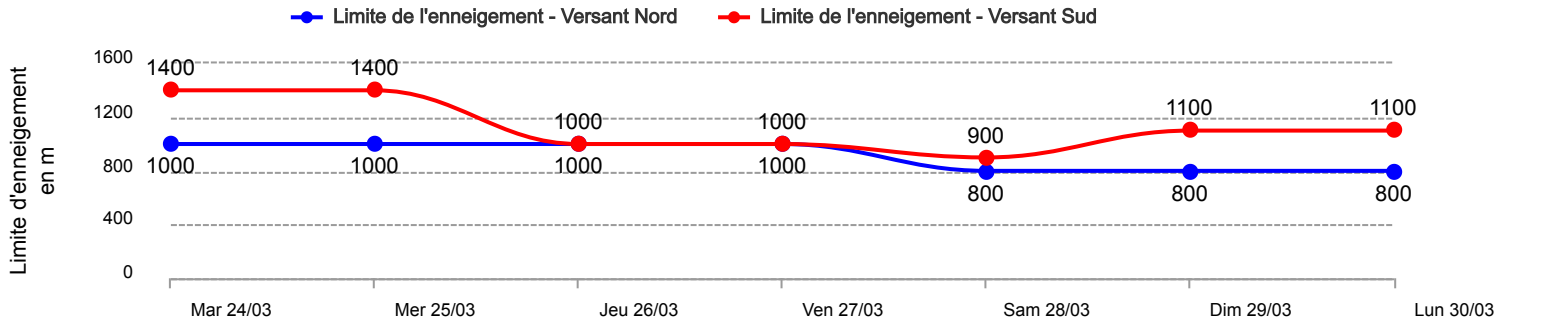


Pour consulter la vigilance en cours, veuillez vous rendre sur le site https://vigilance.meteofrance.fr/fr


Météo-France - 73 avenue de Paris, 94165 Saint-Mandé cedex - Contact : contact@meteo.fr



Rédigé par Météo-France avec la contribution des observateurs du réseau nivo-météorologiques. Partenariat : ANMSM (Maires de Stations de Montagne), DSF (Domaines Skiables de France), ADSP (Directeurs de Pistes et de la Sécurité des Stations de Sports d'Hiver) et autres acteurs de la montagne.


Bulletin neige & avalanches par téléphone au

**0 892 68 10 20** Service 0,35 € / min + prix appel