Bulletin d'estimation du risque d'avalanche

(valable en dehors des pistes balisées et ouvertes)

MASSIF : Capcir Puymorens

Rédigé le lundi 30 mars 2026 à 17h

Estimation des risques pour le : MARDI 31 MARS

INSTABILITÉS DANS LES CHUTES DE NEIGE VENTÉE RÉCENTES OU EN COURS

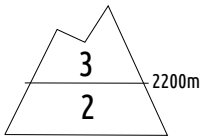

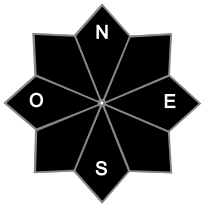

Au-dessus de 2200m indice de risque marqué, plus bas indice limité.

Départs spontanés : Départs ponctuels dans les pentes raides, quelques avalanches en cassure linéaire de taille moyenne près de l'Ariège

Déclenchements provoqués : Avalanches de plaques plus ou moins facilement déclenchables dans les chutes de neige ventée

Indices de risque : 5 très fort - 4 fort - 3 marqué - 2 limité - 1 faible -- En noir : les pentes les plus dangereuses

Stabilité du manteau neigeux

Situation avalancheuse typique : neige ventée

Déclenchements provoqués :
Avalanches de plaques déclenchables au passage d'un skieur : de nouvelles structures de plaques, parfois loin des crêtes, sont présentes et se forment par transport de la neige par un vent turbulent et de direction variable. Les accumulations sont plutôt à attendre dans les versants d'un large Sud à Est, mais pas seulement. Les secteurs proches de l'Ariège sont les plus concernés (Nord du Capcir, vallée du Galbe). Au-dessous de 2200m le déclenchement d'une avalanche de plaques semble plus difficile.
Observables : Quantité de neige fraiche, surface hétérogène travaillée par le vent, fissures devant les skis, "woomfs".

Départs spontanés :
Des départs spontanés en neige sèche sont possibles, par surcharge pendant les chutes de neige et/ou par transport de neige par le vent. Les départs sont le plus souvent ponctuels générant de petites avalanches, mais quelques cassures linéaires sont également possibles occasionnant des avalanches de taille moyenne, rarement grandes.

Qualité de la neige

Enneigement :
L'enneigement est excellent et parmi les meilleurs de ces 20 dernières années. En altitude, les cumuls sont très conséquents, mais les crêtes et sommets exposés au vent d'ouest à nord-ouest sont parfois complètement déneigés. Les nouvelles chutes de neige redonne un aspect blanc dès 1300/1500 m sans changer vraiment l'altitude de skiabilité qui est plutôt vers 1600/1700 m avec une sous-couche permettant de skier plus sereinement.

Qualité de la neige :
Mardi matin on trouvera une petite couche de neige fraîche au-dessus d'une neige récente qui aura commencé à s'humidifier sous 2200m. En altitude, l'enneigement et la qualité de la neige seront assez hétérogènes sous l'action du vent soufflant depuis samedi, avec des zones d'accumulations où la neige fraîche et/ou récente reste localement légère et des crêtes Ouest à Nord-Ouest pelées ou en neige dure, voire glacée.

Aperçu météo pour le mardi 31 mars

	nuit	matin	après-midi	soir
Temps neigeux à proximité de l'Ariège				
Pluie-Neige	1 300 m	1 300 m	1 400 m	1 200 m
Iso 0 °C	1 600 m	1 700 m	1 800 m	1 800 m
Vent 2000 m	↘ 80 km/h	↘ 80 km/h	↘ 80 km/h	↓ 80 km/h
Vent 3000 m	↘ 95 km/h	↘ 85 km/h	↘ 95 km/h	↘ 95 km/h

Épaisseur de neige hors-piste

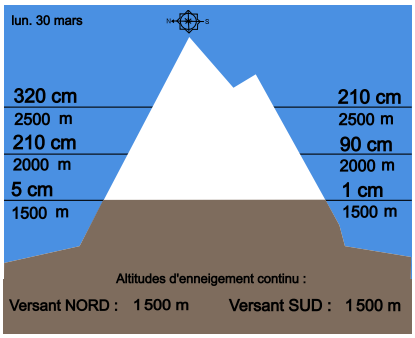

Précipitations à 1800 m

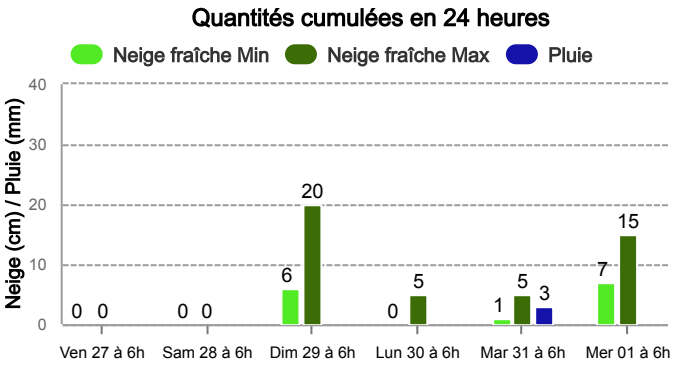

Tendance du mercredi 01 avril

Indice de risque fort

Risque marqué pouvant devenir fort du fait des fortes chutes de neige attendues jusque dans la nuit de mercredi à jeudi

Pour consulter la vigilance en cours, veuillez vous rendre sur le site https://vigilance.meteofrance.fr/fr

Météo-France - 73 avenue de Paris, 94165 Saint-Mandé cedex - Contact : contact@meteo.fr

Rédigé par Météo-France avec la contribution des observateurs du réseau nivo-météorologiques. Partenariat : ANMSM (Maires de Stations de Montagne), DSF (Domaines Skiables de France), ADSP (Directeurs de Pistes et de la Sécurité des Stations de Sports d'Hiver) et autres acteurs de la montagne.

Bulletin neige & avalanches par téléphone au **0 892 68 10 20** Service 0,35 € / min + prix appel

RÉPUBLIQUE FRANÇAISE
Liberté Égalité Fraternité

METEO FRANCE
À VOS CÔTÉS, DANS UN CLIMAT QUI CHANGE

Bulletin d'estimation du risque d'avalanche

(valable en dehors des pistes balisées et ouvertes)

MASSIF : Capcir Puymorens

Rédigé le lundi 30 mars 2026 à 17h

Conditions nivo-météo des 7 derniers jours

	mar. 24/03				mer. 25/03				jeu. 26/03				ven. 27/03				sam. 28/03				dim. 29/03				lun. 30/03			
	03h	09h	15h	21h	03h	09h	15h	21h	03h	09h	15h	21h	03h	09h	15h	21h	03h	09h	15h	21h	03h	09h	15h	21h	03h	09h	15h	21h
Météo																												
Vent (km/h)	20	20	20	20	30	55	75	90	90	100	95	105	95	95	85	70	60	70	85	105	115	110	95	85	80	80	95	100
à 3000m																												
Vent (km/h)	15	10	10	10	15	35	50	70	75	80	80	85	75	75	65	60	45	60	60	80	90	90	80	65	70	70	80	85
à 2000m																												

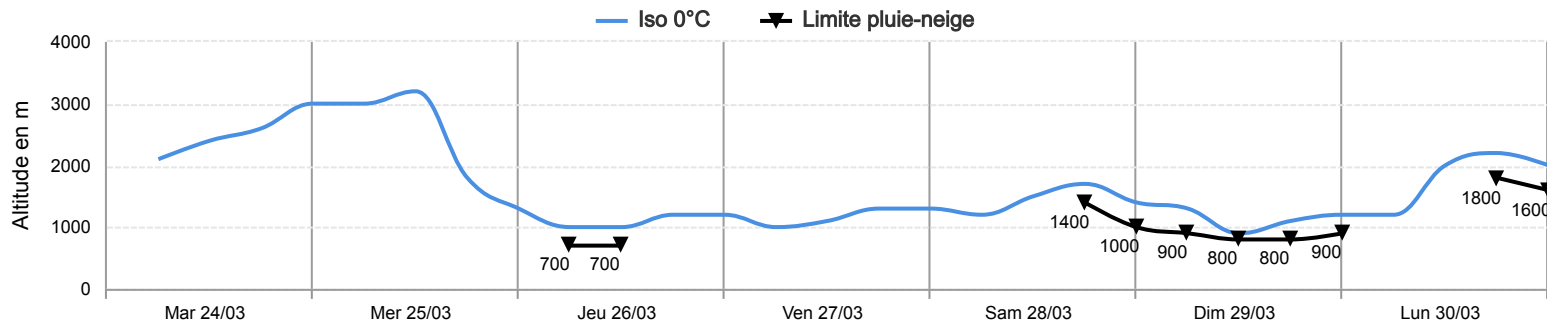

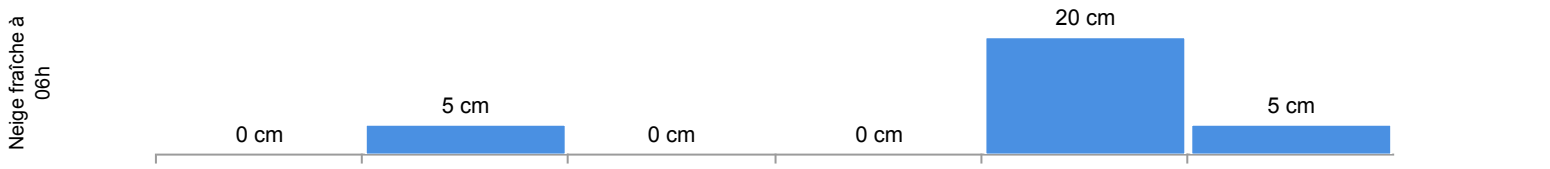

Risque d'avalanche	mar. 24/03	mer. 25/03	jeu. 26/03	ven. 27/03	sam. 28/03	dim. 29/03	lun. 30/03
	3	2	2	2	2	3	3

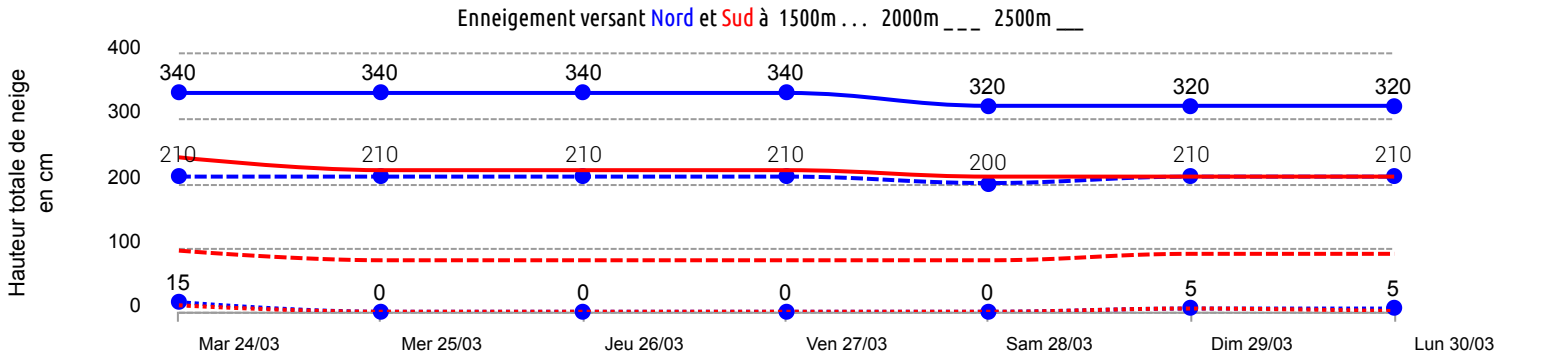

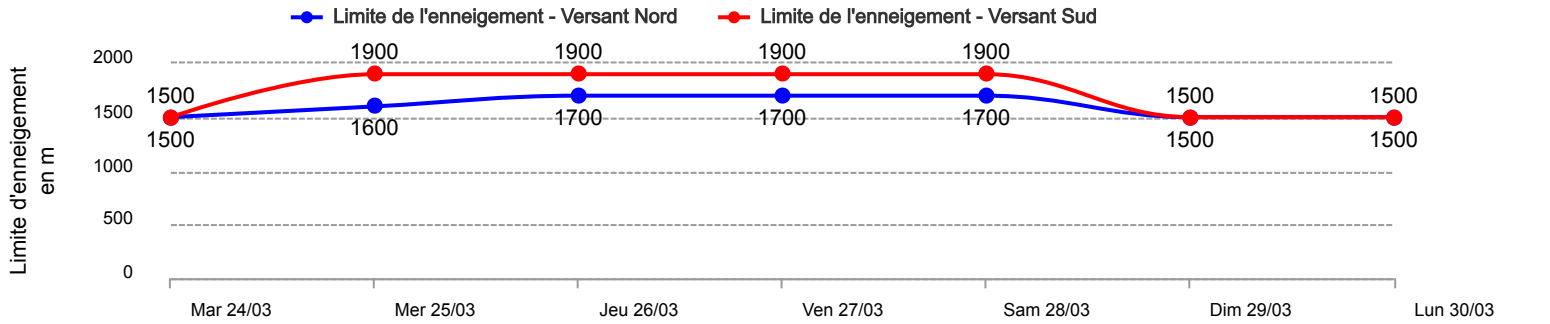

Pour consulter la vigilance en cours, veuillez vous rendre sur le site https://vigilance.meteofrance.fr/fr

Météo-France - 73 avenue de Paris, 94165 Saint-Mandé cedex - Contact : contact@meteo.fr

Rédigé par Météo-France avec la contribution des observateurs du réseau nivo-météorologiques. Partenariat : ANMSM (Maires de Stations de Montagne), DSF (Domaines Skiables de France), ADSP (Directeurs de Pistes et de la Sécurité des Stations de Sports d'Hiver) et autres acteurs de la montagne.

Bulletin neige & avalanches par téléphone au
0 892 68 10 20 Service 0,35 € / min + prix appel