# Bulletin d'estimation du risque d'avalanche
(valable en dehors des pistes balisées et ouvertes)

# MASSIF : Cerdagne Canigou

Rédigé le lundi 30 mars 2026 à 17h

## Estimation des risques pour le : MARDI 31 MARS

**STRUCTURES DE PLAQUES FORMÉES PAR LE TRANSPORT DE NEIGE PAR LE VENT**

2

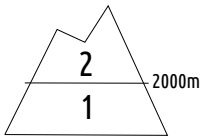


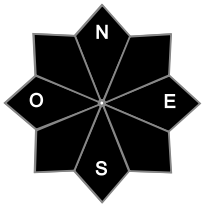


Au-dessus de 2000m indice de risque limité, plus bas indice faible.

**Départs spontanés :** Départs ponctuels en neige récente dans des couloirs raides

**Déclenchements provoqués :** Anciennes plaques en versants nord; nouvelles plaques à vent avec le transport de neige en cours depuis samedi

Indices de risque : 5 très fort - 4 fort - 3 marqué - 2 limité - 1 faible -- En noir : les pentes les plus dangereuses

## Stabilité du manteau neigeux

**Situation avalancheuse typique :**

neige ventée

couche fragile persistante

**Déclenchements provoqués :**

De structures de plaques, plutôt dures proches des crêtes, parfois encore d'aspect friable loin des crêtes et dans des combes plus abritées, sont en place ou encore en formation sous l'action du vent qui souffle depuis plusieurs jours. Leurs déclenchements devraient se limiter à des avalanches de petites tailles toutefois suffisantes pour déséquilibrer ou faire chuter un pratiquant.

De plus, de rares avalanches de plaques plus épaisses (taille moyenne) sont possibles plutôt au-dessus de 2000/2200 m dans un large secteur nord. En effet, des couches fragiles persistantes sont présentes même si elles deviennent de plus en plus difficilement sollicitables par un skieur. Elles sont souvent difficiles à détecter, car masquées par les chutes de neige récente et le transport de neige par le vent.

*Observables : neige en surface travaillée par le vent, fissures devant les skis ou "woomfs" éventuels.*

**Départs spontanés :**

Des départs ponctuels spontanés de petite taille (taille 1) sont possibles soit par humidification dans les pentes raides prenant le soleil dès le matin puis en cours de journée, soit dans la neige sèche par surcharge par le vent dans les couloirs raides.

## Qualité de la neige

**Enneigement** :

L'enneigement est excellent et parmi les meilleurs de ces 20 dernières années. En altitude, les cumuls sont encore conséquents, mais les crêtes et sommets exposés au vent d'ouest à nord-ouest sont souvent complètement déneigés. Avec les nouvelles chutes de neige datant samedi et dimanche matin, on retrouve un peu de neige au mieux vers 1400/1500 m mais on peut seulement chausser vers 1600/1700 m en Nord pour trouver une réelle sous-couche permettant de progresser à ski.

**Qualité de la neige** :

Mardi matin neige regelée dans tous les versants prenant le soleil en journée. Les crêtes et sommets sont toutefois souvent bien pelés ou dégarnis avec de la neige dure et compacte voire glacée. En journée, on s'attend à une humidification de surface dans les versants ensoleillés au fur et à mesure de la journée jusqu'à 1800/2100 m. Ailleurs, on gardera une neige dure et tassée par le vent sauf dans quelques rares combes abritées encore poudreuses.

## Aperçu météo pour le mardi 31 mars

| | nuit | matin | après-midi | soir |
|---|---|---|---|---|
| | | | | |
| Journée plutôt ensoleillée mais à nouveau ventée | | | | |
| **Pluie-Neige** | | | | 1 300 m |
| **Iso 0 °C** | 2 600 m | 2 400 m | 2 200 m | 1 600 m |
| **Vent 2000 m** | ↘ 65 km/h | ↘ 65 km/h | ↘ 70 km/h | ↘ 75 km/h |
| **Vent 3000 m** | ↘ 105 km/h | ↓ 90 km/h | ↓ 100 km/h | ↓ 105 km/h |

## Épaisseur de neige hors-piste

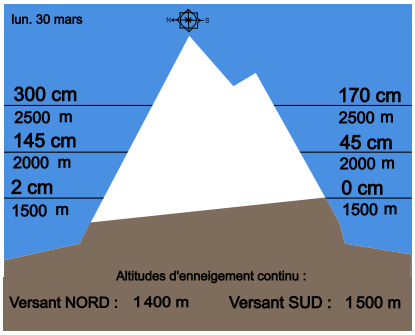


## Précipitations à 1800 m

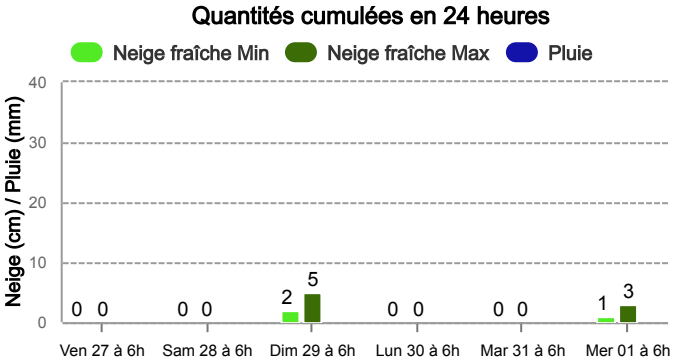


## Tendance du mercredi 01 avril

3

**Indice de risque marqué**

Risque devenant marqué du fait des fortes chutes de neige attendues jusque dans la nuit de mercredi à jeudi

Pour consulter la vigilance en cours, veuillez vous rendre sur le site https://vigilance.meteofrance.fr/fr

Météo-France - 73 avenue de Paris, 94165 Saint-Mandé cedex - Contact : contact@meteo.fr

Rédigé par Météo-France avec la contribution des observateurs du réseau nivo-météorologiques. Partenariat : ANMSM (Maires de Stations de Montagne), DSF (Domaines Skiables de France), ADSP (Directeurs de Pistes et de la Sécurité des Stations de Sports d'Hiver) et autres acteurs de la montagne.

Bulletin neige & avalanches par téléphone au
0 892 68 10 20 Service 0,35 € / min + prix appel

RÉPUBLIQUE FRANÇAISE
*Liberté Égalité Fraternité*

METEO FRANCE
À VOS CÔTÉS, DANS UN CLIMAT QUI CHANGE

# Bulletin d'estimation du risque d'avalanche

(valable en dehors des pistes balisées et ouvertes)

# MASSIF : Cerdagne Canigou

Rédigé le lundi 30 mars 2026 à 17h

## Conditions nivo-météo des 7 derniers jours

| | mar. 24/03 | | | | mer. 25/03 | | | | jeu. 26/03 | | | | ven. 27/03 | | | | sam. 28/03 | | | | dim. 29/03 | | | | lun. 30/03 | | | |
|---|---|---|---|---|---|---|---|---|---|---|---|---|---|---|---|---|---|---|---|---|---|---|---|---|---|---|---|---|
| | 03h | 09h | 15h | 21h | 03h | 09h | 15h | 21h | 03h | 09h | 15h | 21h | 03h | 09h | 15h | 21h | 03h | 09h | 15h | 21h | 03h | 09h | 15h | 21h | 03h | 09h | 15h | 21h |
| Météo | | | | | | | | | | | | | | | | | | | | | | | | | | | | |
| Vent (km/h) | 25 | 20 | 20 | 20 | 25 | 35 | 40 | 70 | 90 | 100 | 95 | 105 | 95 | 95 | 85 | 70 | 75 | 70 | 80 | 105 | 120 | 110 | 90 | 90 | 90 | 85 | 90 | 100 |
| à 3000m | ↘ | ↘ | ↑ | ↘ | → | ↙ | ↘ | ↘ | ↘ | ↘ | ↘ | ↘ | ↘ | ↓ | ↓ | ↘ | ↓ | ↓ | ↘ | ↘ | ↘ | ↓ | ↓ | ↓ | ↓ | ↓ | ↘ | ↓ |
| Vent (km/h) | 15 | 10 | 10 | 10 | 15 | 20 | 30 | 45 | 75 | 80 | 80 | 85 | 75 | 75 | 65 | 55 | 60 | 50 | 60 | 80 | 95 | 85 | 65 | 70 | 60 | 60 | 70 | 75 |
| à 2000m | ↘ | ↙ | ↗ | ↘ | ↘ | ↓ | ↘ | ↘ | ↘ | ↘ | ↘ | ↘ | ↘ | ↓ | ↘ | ↓ | ↓ | ↓ | ↓ | ↓ | ↘ | ↓ | ↓ | ↘ | ↘ | ↘ | ↘ | ↘ |

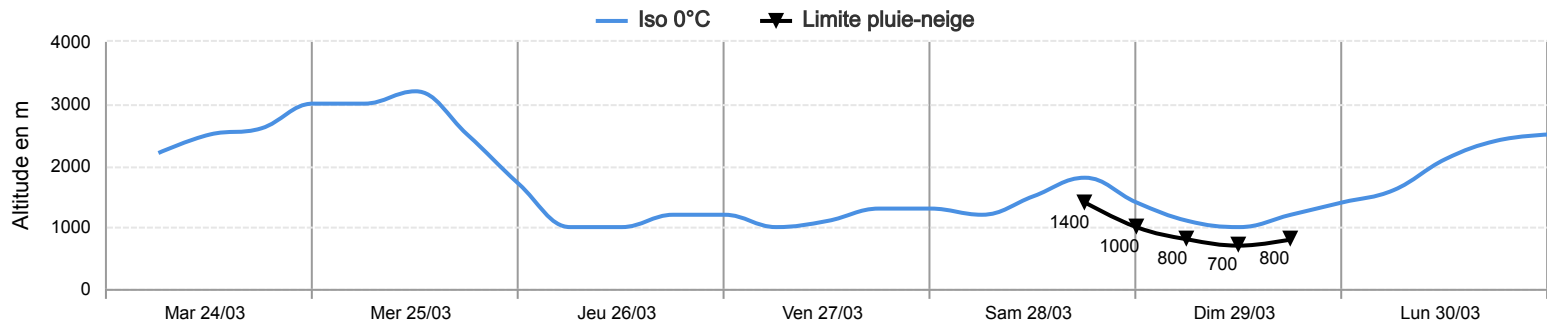


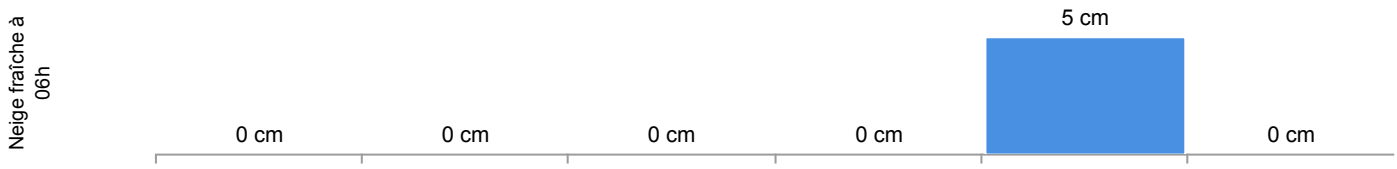


| Risque d'avalanche | mar. 24/03 | mer. 25/03 | jeu. 26/03 | ven. 27/03 | sam. 28/03 | dim. 29/03 | lun. 30/03 |
|---|---|---|---|---|---|---|---|
| | 2 | 2 | 2 | 2 | 2 | 2 | 2 |

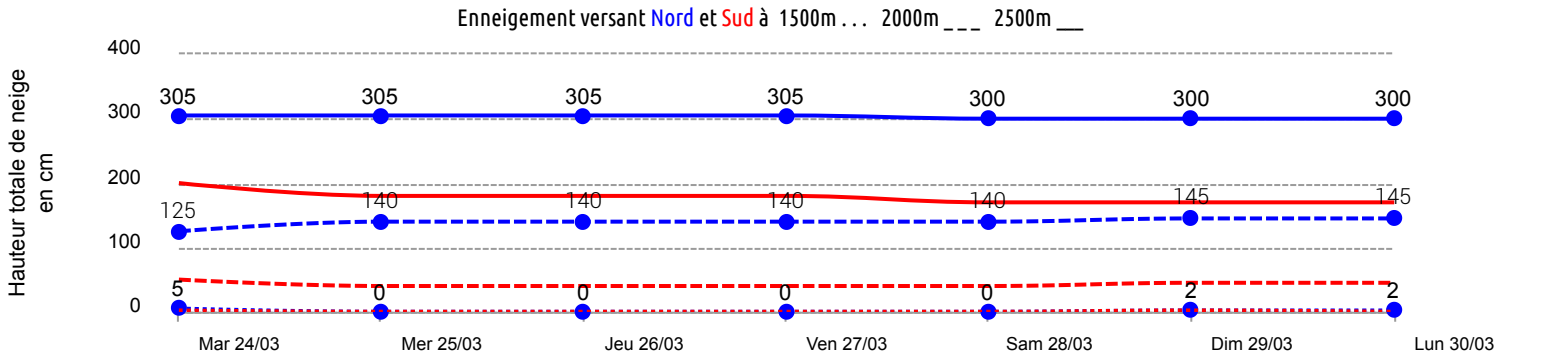


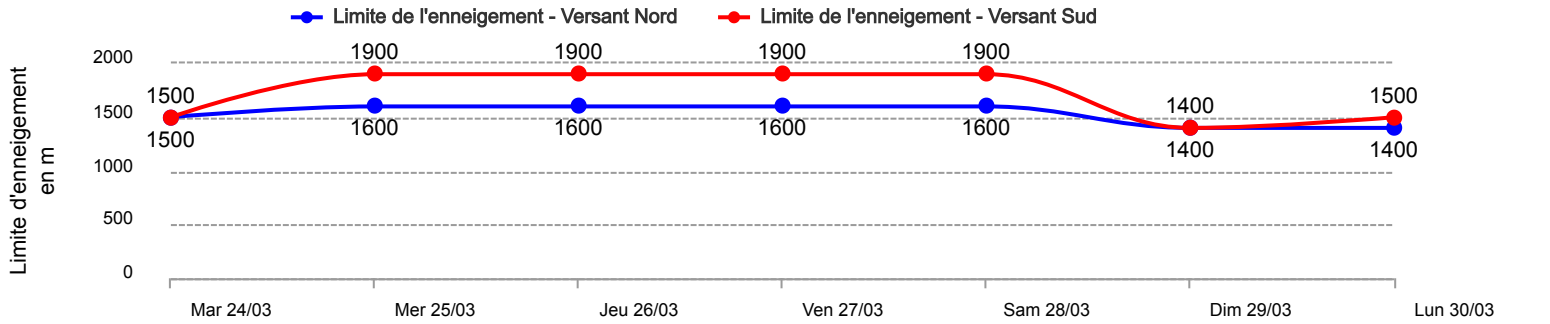


Pour consulter la vigilance en cours, veuillez vous rendre sur le site https://vigilance.meteofrance.fr/fr


Météo-France - 73 avenue de Paris, 94165 Saint-Mandé cedex - Contact : contact@meteo.fr



Rédigé par Météo-France avec la contribution des observateurs du réseau nivo-météorologiques. Partenariat : ANMSM (Maires de Stations de Montagne), DSF (Domaines Skiables de France), ADSP (Directeurs de Pistes et de la Sécurité des Stations de Sports d'Hiver) et autres acteurs de la montagne.



Bulletin neige & avalanches par téléphone au
0 892 68 10 20 Service 0,35 € / min + prix appel