Bulletin d'estimation du risque d'avalanche
(valable en dehors des pistes balisées et ouvertes)

MASSIF : Chartreuse

Rédigé le lundi 30 mars 2026 à 17h

Estimation des risques pour le : MARDI 31 MARS

NOUVELLES INSTABILITES DANS LA NEIGE FRAICHE VENTEE, SURTOUT EN LARGE SUD

2

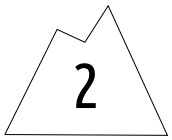

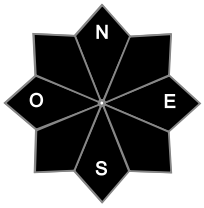

Indice de risque limité.

Départs spontanés : Quelques ruptures de plaques sont possibles dans les pentes chargées par le vent de nord

Déclenchements provoqués : Nouvelles plaques formées par le vent de nord dans la neige fraîche.

Indices de risque : 5 très fort - 4 fort - 3 marqué - 2 limité - 1 faible -- En noir : les pentes les plus dangereuses

Stabilité du manteau neigeux

Situation avalancheuse typique : neige ventée

Nouveau passage perturbé apportant 5 à 15cm de neige fraîche sur le massif d'ici mardi matin. Ces chutes de neige s'accompagnent d'un vent de secteur Nord parfois tempétueux.

Déclenchements provoqués : De nouvelles plaques se forment sous ces chutes de neige nocturnes, puis sous le vent de Nord en journée de mardi. Elles peuvent se retrouver en tout versant, mais sont généralement plus nombreuses et plus épaisses en large Sud où la neige s'accumule, tandis que les versants Nord sont plus régulièrement dégarnis par le vent. Les plaques sont généralement de petites tailles, parfois moyennes (15-30cm d'épais, faibles largeurs), mais peuvent être localement assez réactives, notamment là où elles sont d'aspect friables.

Observables : transport en cours, zones d'accumulations, congères, signes du travail par le vent...

Départs spontanés : Principalement en versants Sud, des ruptures de plaques (de tailles petites, rarement moyennes) sont possibles dans les pentes qui se chargent sous le vent de Nord. Le vent étant particulièrement fort, ces ruptures peuvent se produire même loin des crêtes. Sous les éclaircies en journée, quelques coulées de petites tailles sont possibles en pentes raides ensoleillées. Départs seulement sous les rochers, en secteurs peu ventés (donc plutôt à basse altitude).

Autres : Suite au faible épisode de pluie vitrifiante de lundi, des surfaces verglacées peuvent apparaître près des crêtes et dans les pentes exposées au vent de Nord, rendant la progression délicate sans équipement adapté.

Qualité de la neige

Qualification de l'enneigement : L'enneigement est bon à basse altitude, et même très bon dés 1800 / 2000m mais avec des répartitions assez hétérogènes à cause du vent. Peu de sous couche sous 1700m en plein Sud.

Limites skiables : Vers 1000 / 1200m selon le versant, avec prudence en Sud / sous les sapins

Qualité de la neige mardi : Neige de qualité très variable sur le massif. La plupart du temps, neige récente fraîche travaillée ou cartonnée par le vent dans de nombreux endroits (notamment versants Sud). Les crêtes et pentes exposées au vent de Nord sont souvent pelés, et présentent parfois une couche de glace vive, formée par un épisode de pluie vitrifiante ce lundi après-midi. On peut encore retrouver quelques combes en poudreuse, à priori plutôt celles abritées du vent de Nord (où la neige aura été soufflée, ou parfois croûtée par la pluie).

En journée, la neige de surface s'humidifie au soleil, dans les pentes protégées du vent.

Aperçu météo pour le mardi 31 mars

	nuit	matin	après-midi	soir
	Assez nuageux en matinée, belles éclaircies en journée, sous un vent de Nord sensible voire fort en altitude.			
Pluie-Neige	1 000 m			
Iso 0 °C	1 300 m	1 200 m	1 400 m	1 200 m
Vent 1500 m	↓ 50 km/h	↓ 55 km/h	↓ 55 km/h	↓ 60 km/h
Vent 2000 m	↓ 75 km/h	↙ 65 km/h	↓ 65 km/h	↙ 70 km/h

Épaisseur de neige hors-piste

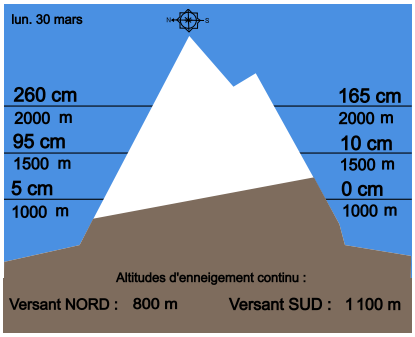

Précipitations à 1800 m

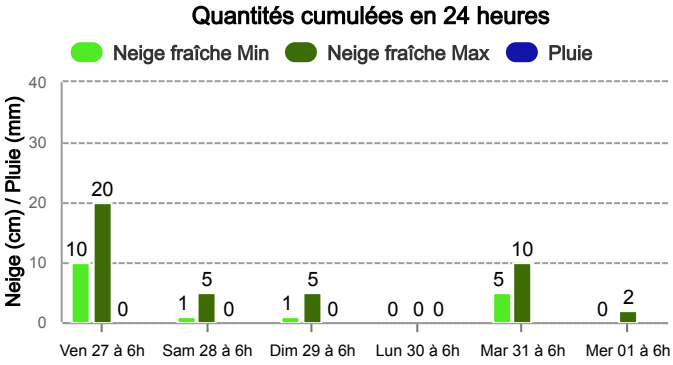

Tendance du mercredi 01 avril

2

Indice de risque limité

Mercredi, le risque évolue peu. Le vent, encore fort en matinée, faiblit en journée. Temps toujours assez nuageux, même si de belles éclaircies sont possibles par moment. L'atmosphère est toujours fraîche.

Pour consulter la vigilance en cours, veuillez vous rendre sur le site https://vigilance.meteofrance.fr/fr

Météo-France - 73 avenue de Paris, 94165 Saint-Mandé cedex - Contact : contact@meteo.fr

Rédigé par Météo-France avec la contribution des observateurs du réseau nivo-météorologiques. Partenariat : ANMSM (Maires de Stations de Montagne), DSF (Domaines Skiables de France), ADSP (Directeurs de Pistes et de la Sécurité des Stations de Sports d'Hiver) et autres acteurs de la montagne.

Bulletin neige & avalanches par téléphone au
0 892 68 10 20 Service 0,35 € / min + prix appel

RÉPUBLIQUE FRANÇAISE
Liberté Égalité Fraternité

METEO FRANCE
À VOS CÔTÉS, DANS UN CLIMAT QUI CHANGE

Bulletin d'estimation du risque d'avalanche
(valable en dehors des pistes balisées et ouvertes)
MASSIF : Chartreuse

Rédigé le lundi 30 mars 2026 à 17h

Conditions nivo-météo des 7 derniers jours

	mar. 24/03				mer. 25/03				jeu. 26/03				ven. 27/03				sam. 28/03				dim. 29/03				lun. 30/03			
	03h	09h	15h	21h	03h	09h	15h	21h	03h	09h	15h	21h	03h	09h	15h	21h	03h	09h	15h	21h	03h	09h	15h	21h	03h	09h	15h	21h
Météo																												
Vent (km/h)	30	15	5	10	25	50	80	80	90	80	75	70	75	70	45	30	45	55	40	60	60	50	35	40	45	40	60	65
à 2000m																												
Vent (km/h)	15	10	15	10	10	25	55	50	50	45	55	45	40	55	35	20	35	40	25	40	40	35	20	30	30	30	50	50
à 1500m																												

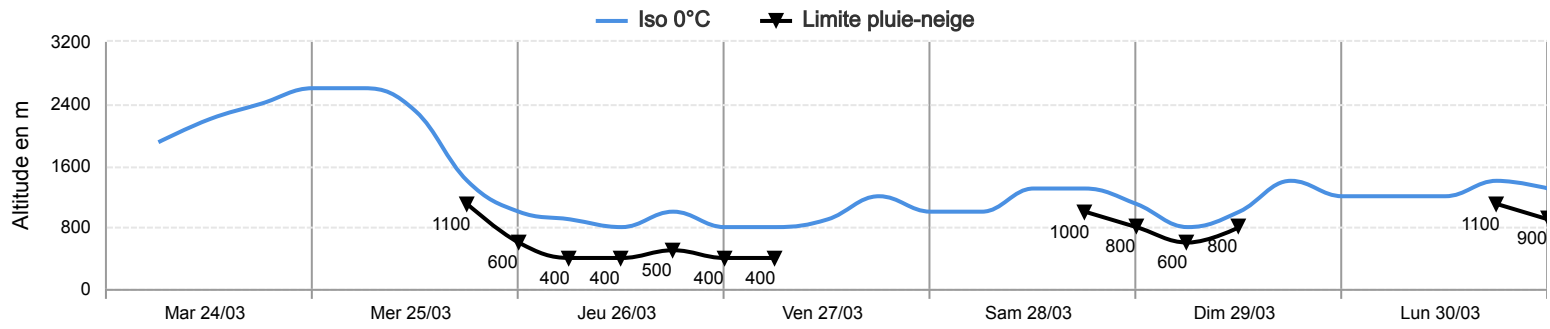

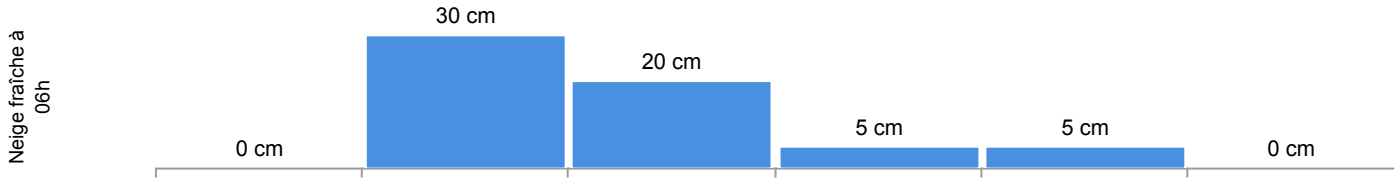

Risque d'avalanche	mar. 24/03	mer. 25/03	jeu. 26/03	ven. 27/03	sam. 28/03	dim. 29/03	lun. 30/03
	2	2	4	3	2	2	2

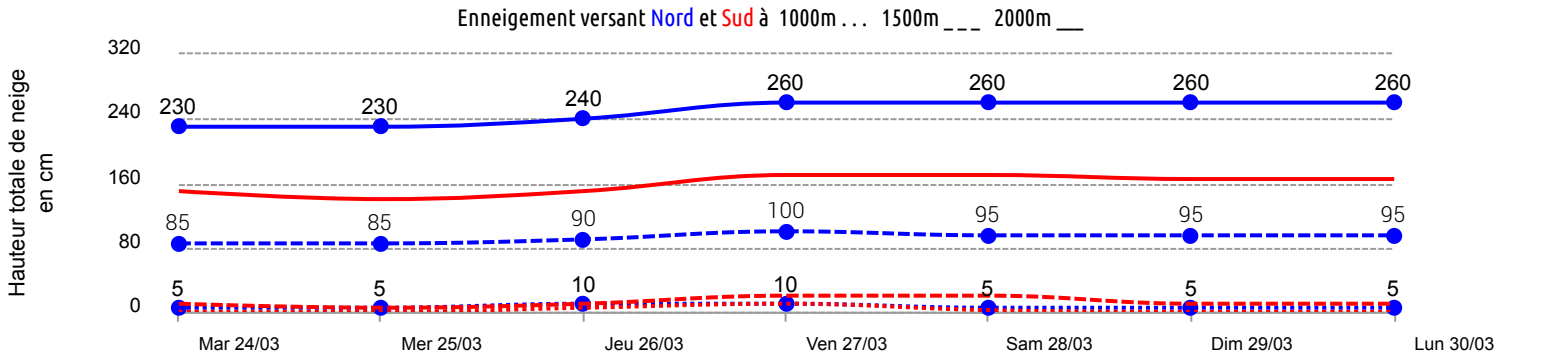

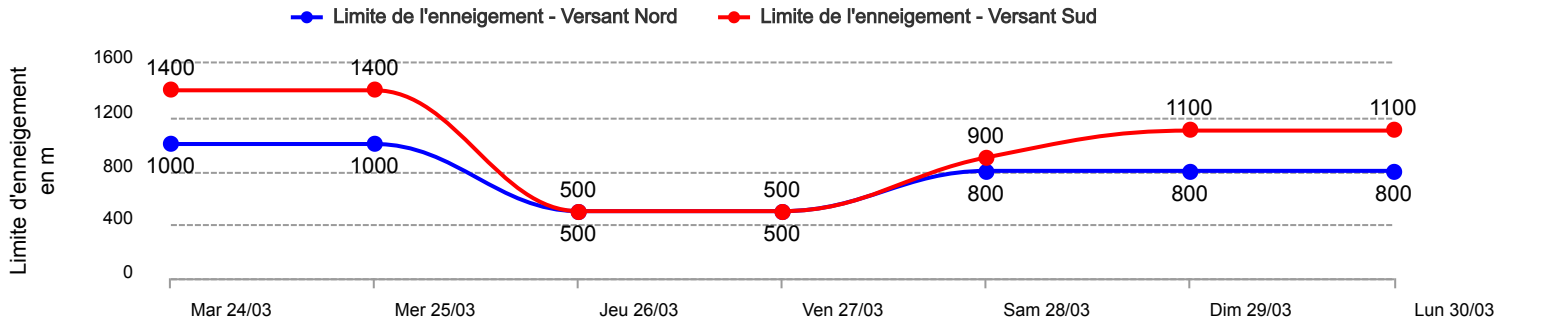

Pour consulter la vigilance en cours, veuillez vous rendre sur le site https://vigilance.meteofrance.fr/fr

Météo-France - 73 avenue de Paris, 94165 Saint-Mandé cedex - Contact : contact@meteo.fr

Rédigé par Météo-France avec la contribution des observateurs du réseau nivo-météorologiques. Partenariat : ANMSM (Maires de Stations de Montagne), DSF (Domaines Skiables de France), ADSP (Directeurs de Pistes et de la Sécurité des Stations de Sports d'Hiver) et autres acteurs de la montagne.

Bulletin neige & avalanches par téléphone au
0 892 68 10 20 Service 0,35 € / min + prix appel