Bulletin d'estimation du risque d'avalanche
(valable en dehors des pistes balisées et ouvertes)

MASSIF : Oisans

Rédigé le lundi 30 mars 2026 à 17h

Estimation des risques pour le : MARDI 31 MARS

QUELQUES NOUVELLES INSTABILITÉS DANS LA NEIGE VENTÉE

2

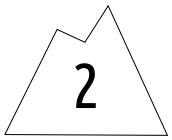

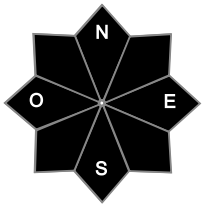

Indice de risque limité.

Départs spontanés : Quelques ruptures de plaques sont possibles dans les pentes chargées par le vent de nord

Déclenchements provoqués : Nouvelles plaques formées par le vent de nord dans la neige fraîche.

Indices de risque : 5 très fort - 4 fort - 3 marqué - 2 limité - 1 faible -- En noir : les pentes les plus dangereuses

Stabilité du manteau neigeux

Situation avalancheuse typique : neige ventée

Nouveau passage faiblement perturbé apportant 2 à 5cm de neige fraîche sur le massif d'ici mardi matin. Ces chutes de neige s'accompagnent d'un vent de secteur Nord parfois tempétueux.

Déclenchements provoqués : Quelques nouvelles plaques à vent se forment ce mardi sous le vent de Nord. Elles peuvent se retrouver en tout versant, mais sont généralement plus nombreuses et plus épaisses en large Sud où la neige s'accumule sous l'effet du vent, tandis que les versants Nord sont plus régulièrement pelés. Les plaques sont généralement de petites tailles, parfois moyennes (7-15cm d'épais, faibles largeurs), mais peuvent être localement assez réactives, notamment là où elles sont d'aspect friables (plutôt loin des crêtes, en milieu / bas de pentes).

Observables : transport en cours, zones d'accumulations, congères, signes du travail par le vent...

Départs spontanés : Principalement en versants Sud, des ruptures de plaques (généralement de petites tailles, rarement moyennes) sont possibles dans les pentes qui se chargent sous le vent de Nord. Le vent étant particulièrement fort, ces ruptures peuvent se produire même loin des crêtes. Sous les éclaircies en journée, quelques coulées de petites tailles sont possibles en pentes raides ensoleillées. Départs seulement sous les rochers, en secteurs peu ventés (donc plutôt à basse altitude).

Autres : Les surfaces décapées par le vent près des crêtes sont parfois en glace, et peuvent être très glissantes.

Qualité de la neige

Qualification de l'enneigement : L'enneigement est bon à basse altitude, et même très bon dés 1800 / 2000m mais avec des répartitions assez hétérogènes à cause du vent. Peu de sous couche sous 1700m en plein Sud.

Limites skiables : Vers 1000 / 1500m selon le versant, avec prudence en Sud / sous les sapins

Qualité de la neige mardi : Neige de qualité très variable sur le massif. La plupart du temps, neige fraîche travaillée ou cartonnée par le vent dans de nombreux endroits. Les crêtes et pentes exposées au vent de Nord sont souvent dégarnies suite à la succession d'épisodes de vent. En versants Sud, dans certaines combes abritées et en bas de pentes / secteurs forestiers, la neige est parfois restée poudreuse, avec encore du bon ski par endroits.

En journée, la neige de surface s'humidifie au soleil, dans les pentes protégées du vent.

Aperçu météo pour le mardi 31 mars

	nuit	matin	après-midi	soir

Temps encore assez nuageux en matinée. Eclaircies de plus en plus généreuses au fil de la journée, mais les sommets restent parfois accrochés. Le vent de Nord reste très fort, voire tempêtueux en altitude.

Pluie-Neige	1 100 m			
Iso 0 °C	1 600 m	1 500 m	1 700 m	1 300 m
Vent 2500 m	↓ 85 km/h	↙ 90 km/h	↙ 80 km/h	↙ 80 km/h
Vent 3500 m	↓ 120 km/h	↙ 120 km/h	↙ 115 km/h	↙ 105 km/h

Épaisseur de neige hors-piste

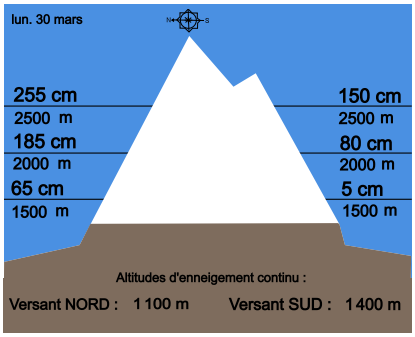

Précipitations à 1800 m

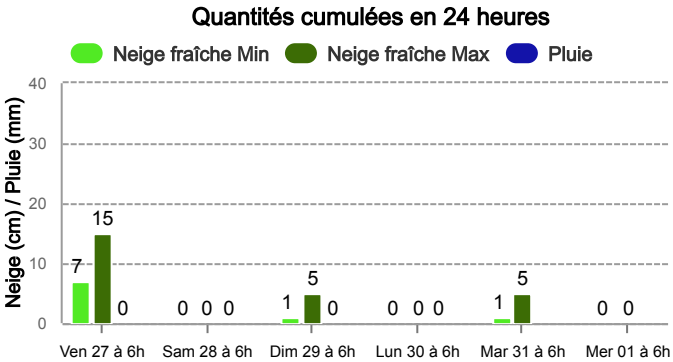

Tendance du mercredi 01 avril

2

Indice de risque limité

Mercredi, le risque évolue peu. Le vent, encore fort en matinée, faiblit en journée. On devrait profiter de belles éclaircies en matinée, avant le retour d'un temps plus nuageux l'après-midi, le tout dans une atmosphère toujours fraîche.

Pour consulter la vigilance en cours, veuillez vous rendre sur le site https://vigilance.meteofrance.fr/fr

Météo-France - 73 avenue de Paris, 94165 Saint-Mandé cedex - Contact : contact@meteo.fr

Rédigé par Météo-France avec la contribution des observateurs du réseau nivo-météorologiques. Partenariat : ANMSM (Maires de Stations de Montagne), DSF (Domaines Skiables de France), ADSP (Directeurs de Pistes et de la Sécurité des Stations de Sports d'Hiver) et autres acteurs de la montagne.

Bulletin neige & avalanches par téléphone au

0 892 68 10 20 Service 0,35 € / min + prix appel

RÉPUBLIQUE FRANÇAISE
Liberté Égalité Fraternité

METEO FRANCE
À VOS CÔTÉS, DANS UN CLIMAT QUI CHANGE

Bulletin d'estimation du risque d'avalanche
(valable en dehors des pistes balisées et ouvertes)

MASSIF : Oisans

Rédigé le lundi 30 mars 2026 à 17h

Conditions nivo-météo des 7 derniers jours

	mar. 24/03				mer. 25/03				jeu. 26/03				ven. 27/03				sam. 28/03				dim. 29/03				lun. 30/03			
	03h	09h	15h	21h	03h	09h	15h	21h	03h	09h	15h	21h	03h	09h	15h	21h	03h	09h	15h	21h	03h	09h	15h	21h	03h	09h	15h	21h
Météo																												
Vent (km/h)	20	15	10	10	15	60	85	100	100	85	85	100	80	70	50	40	55	50	55	55	50	35	30	25	50	80	95	105
à 3500m																												
Vent (km/h)	10	10	10	5	10	40	75	75	70	70	70	75	65	50	40	25	40	45	50	50	45	30	25	20	35	65	70	85
à 2500m																												

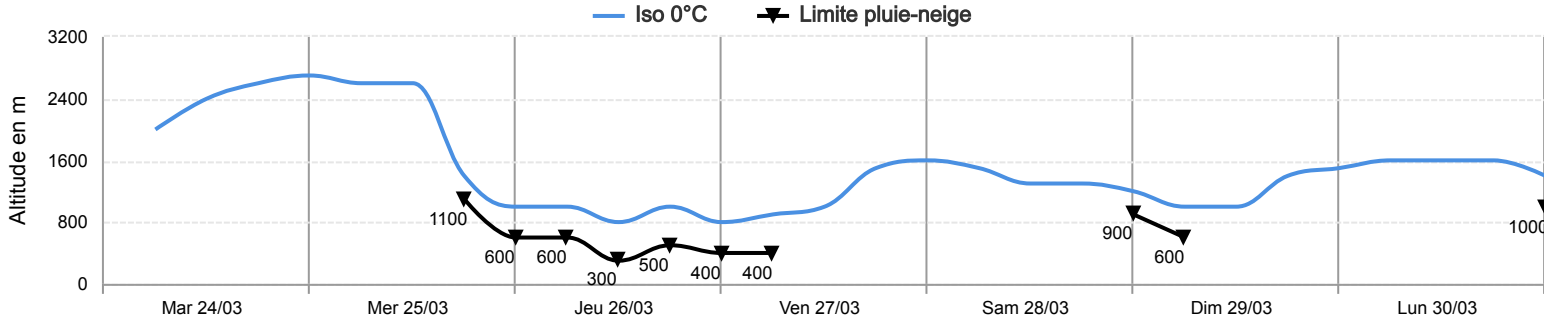

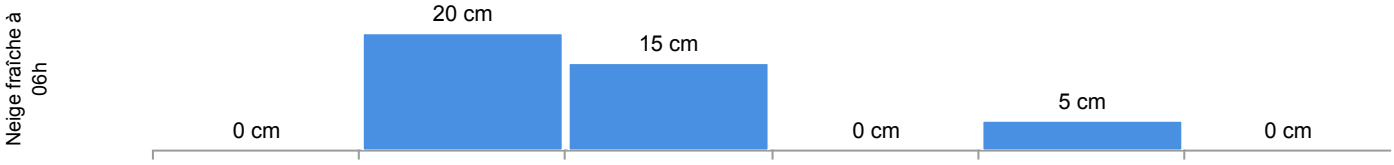

Risque d'avalanche	mar. 24/03	mer. 25/03	jeu. 26/03	ven. 27/03	sam. 28/03	dim. 29/03	lun. 30/03
	2	3	4	3	2	2	2

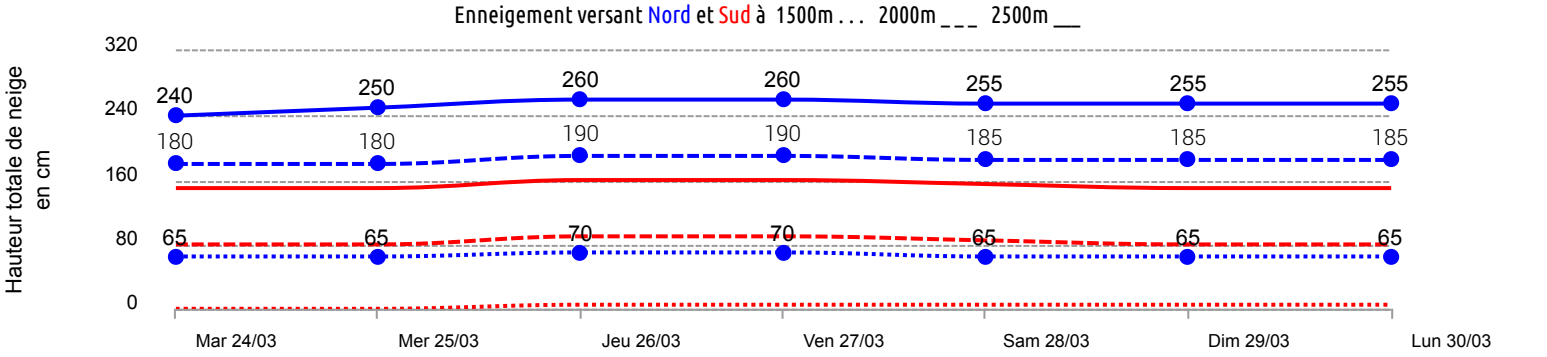

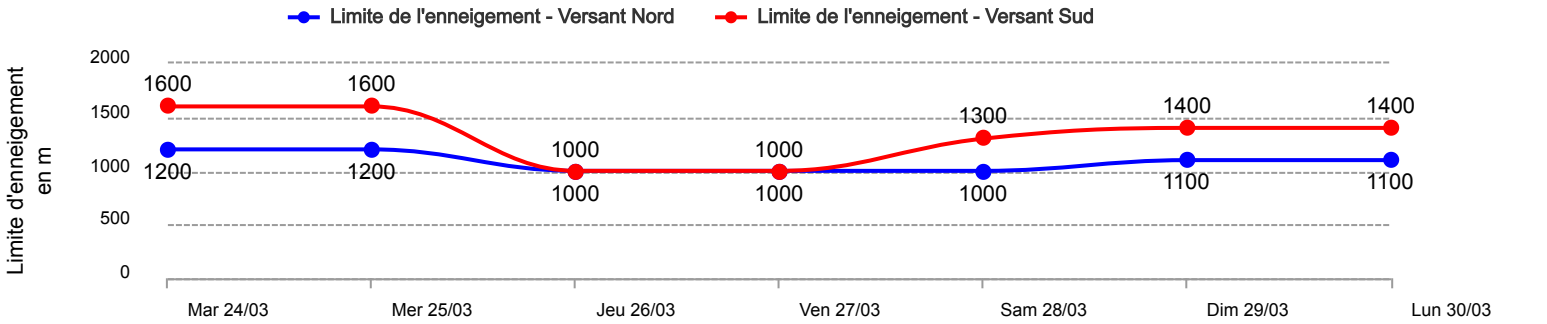

Pour consulter la vigilance en cours, veuillez vous rendre sur le site https://vigilance.meteofrance.fr/fr

Météo-France - 73 avenue de Paris, 94165 Saint-Mandé cedex - Contact : contact@meteo.fr

Bulletin neige & avalanches par téléphone au **0 892 68 10 20** Service 0,35 € / min + prix appel

Rédigé par Météo-France avec la contribution des observateurs du réseau nivo-météorologiques. Partenariat : ANMSM (Maires de Stations de Montagne), DSF (Domaines Skiables de France), ADSP (Directeurs de Pistes et de la Sécurité des Stations de Sports d'Hiver) et autres acteurs de la montagne.