Bulletin d'estimation du risque d'avalanche
(valable en dehors des pistes balisées et ouvertes)

MASSIF : Pays-Basque

Rédigé le lundi 30 mars 2026 à 17h

Estimation des risques pour le : MARDI 31 MARS

RARES PLAQUES PEU ÉPAISSES

2

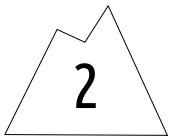

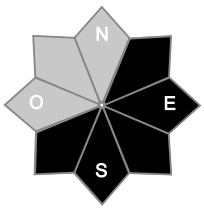

Indice de risque limité.

Départs spontanés : Petits départs ponctuels en pentes raides

Déclenchements provoqués : Quelques plaques en neige récente

Indices de risque : 5 très fort - 4 fort - 3 marqué - 2 limité - 1 faible -- En noir : les pentes les plus dangereuses

Stabilité du manteau neigeux

Situation avalancheuse typique : neige ventée

Déclenchements provoqués :
Des plaques se forment dans les expositions à l'abri du vent de nord à nord-ouest. Elles se situent plutôt à proximité des cols et crêtes, formées par un vent modéré. Elles engendrent des avalanches de petite taille en général, des moyennes deviennent possibles en journée au fil des chutes de neige.

Départs spontanés :
Principalement des départs ponctuels au fil des chutes de neige, dans les pentes raides, préférentiellement dans les versants sous le vent.

Qualité de la neige

Enneigement : Correct pour la saison au-dessus de 1800m, mais restant assez maigre en versants exposés au vent d'ouest. Les sols devraient être blanchis à partir de 1300m.
État de la neige : Mardi matin, quelques centimètres de neige fraîche, peu ventée recouvrant un manteau en général printanier, assez bien regelé.

Aperçu météo pour le mardi 31 mars

	nuit	matin	après-midi	soir
	Relief souvent bouché, neige faible en matinée, accalmie à la mi-journée, reprise des précipitations l'après-midi, un peu plus marquées.			
Pluie-Neige	1 200 m	1 400 m	1 300 m	1 200 m
Iso 0 °C	1 500 m	1 700 m	1 700 m	1 500 m
Vent 1000 m	↓ 40 km/h	↓ 30 km/h	↓ 35 km/h	↓ 40 km/h
Vent 2000 m	↓ 55 km/h	↓ 50 km/h	↓ 50 km/h	↓ 55 km/h

Épaisseur de neige hors-piste

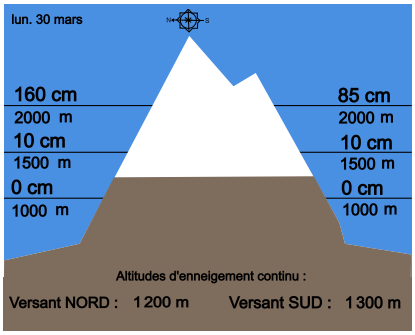

Précipitations à 1800 m

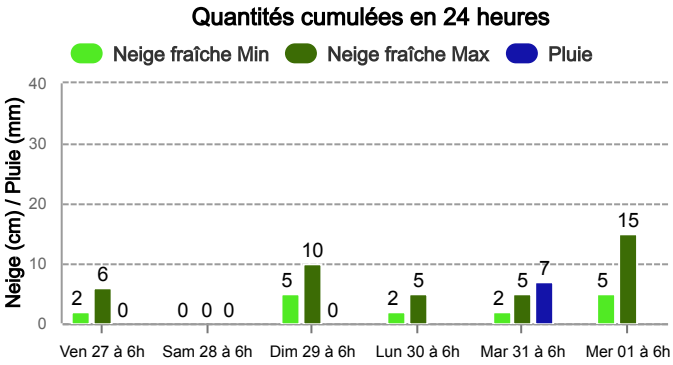

Tendance du mercredi 01 avril

3

Indice de risque marqué

Risque en hausse avec l'augmentation des cumuls

Pour consulter la vigilance en cours, veuillez vous rendre sur le site https://vigilance.meteofrance.fr/fr

Météo-France - 73 avenue de Paris, 94165 Saint-Mandé cedex - Contact : contact@meteo.fr

Rédigé par Météo-France avec la contribution des observateurs du réseau nivo-météorologiques. Partenariat : ANMSM (Maires de Stations de Montagne), DSF (Domaines Skiables de France), ADSP (Directeurs de Pistes et de la Sécurité des Stations de Sports d'Hiver) et autres acteurs de la montagne.

Bulletin neige & avalanches par téléphone au
0 892 68 10 20 Service 0,35 € / min + prix appel

RÉPUBLIQUE FRANÇAISE
Liberté Égalité Fraternité

METEO FRANCE
À VOS CÔTÉS, DANS UN CLIMAT QUI CHANGE

Bulletin d'estimation du risque d'avalanche

(valable en dehors des pistes balisées et ouvertes)

MASSIF : Pays-Basque

Rédigé le lundi 30 mars 2026 à 17h

Conditions nivo-météo des 7 derniers jours

	mar. 24/03				mer. 25/03				jeu. 26/03				ven. 27/03				sam. 28/03				dim. 29/03				lun. 30/03			
	03h	09h	15h	21h	03h	09h	15h	21h	03h	09h	15h	21h	03h	09h	15h	21h	03h	09h	15h	21h	03h	09h	15h	21h	03h	09h	15h	21h
Météo																												
Vent (km/h)	25	15	5	15	15	10	50	65	75	80	85	85	75	65	55	55	55	55	65	75	80	85	75	75	60	45	50	50
à 2000m																												
Vent (km/h)	10	10	2	5	5	2	15	25	35	40	50	50	35	35	35	25	20	25	40	45	45	40	50	40	35	25	35	40
à 1000m																												

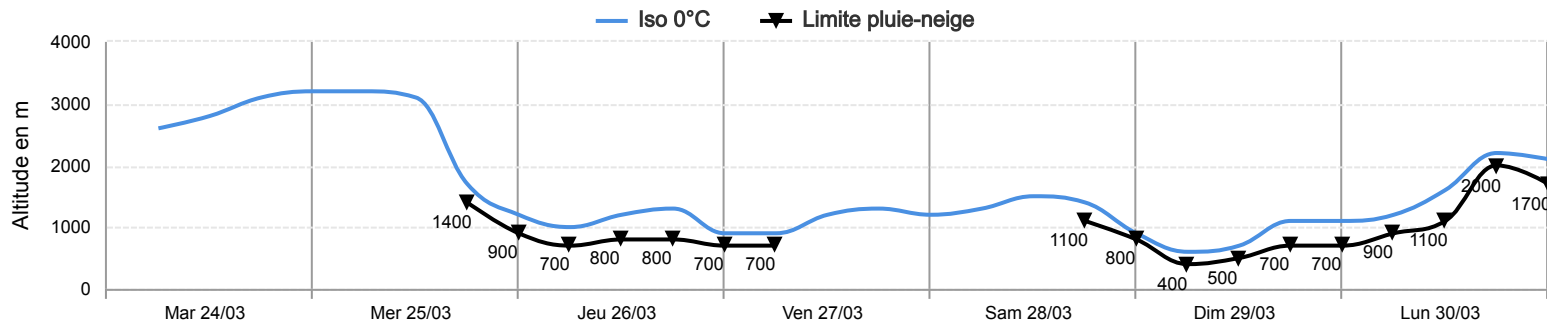

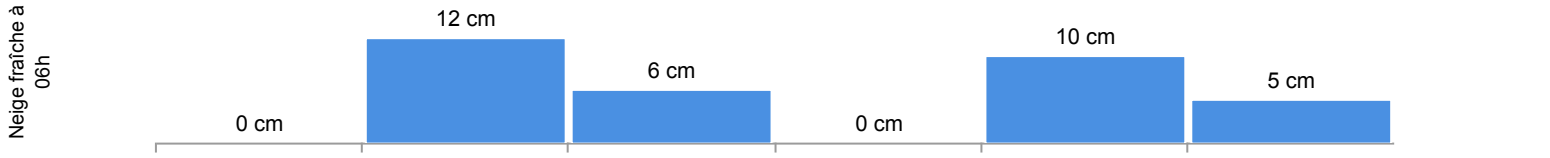

Risque d'avalanche	mar. 24/03	mer. 25/03	jeu. 26/03	ven. 27/03	sam. 28/03	dim. 29/03	lun. 30/03
	2	2	2	2	2	3	3

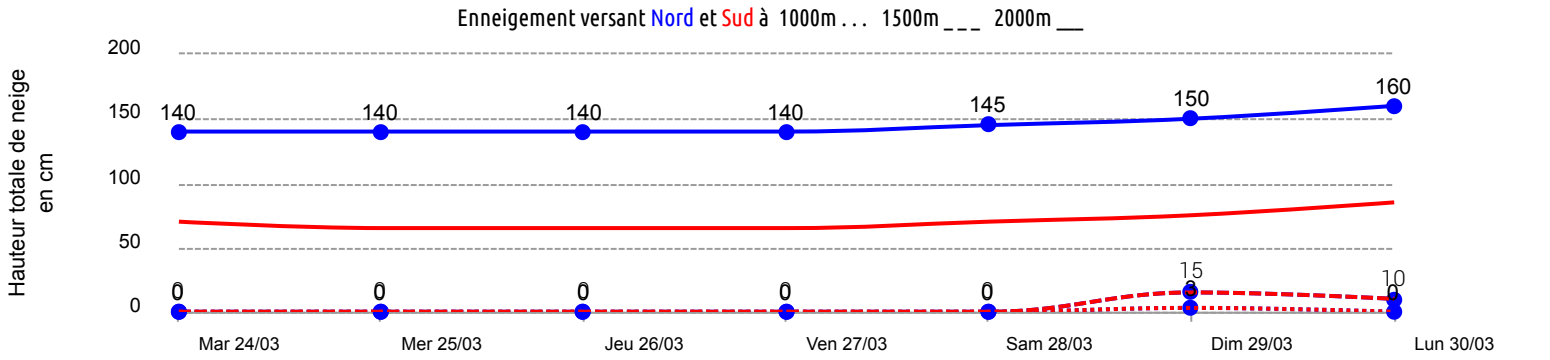

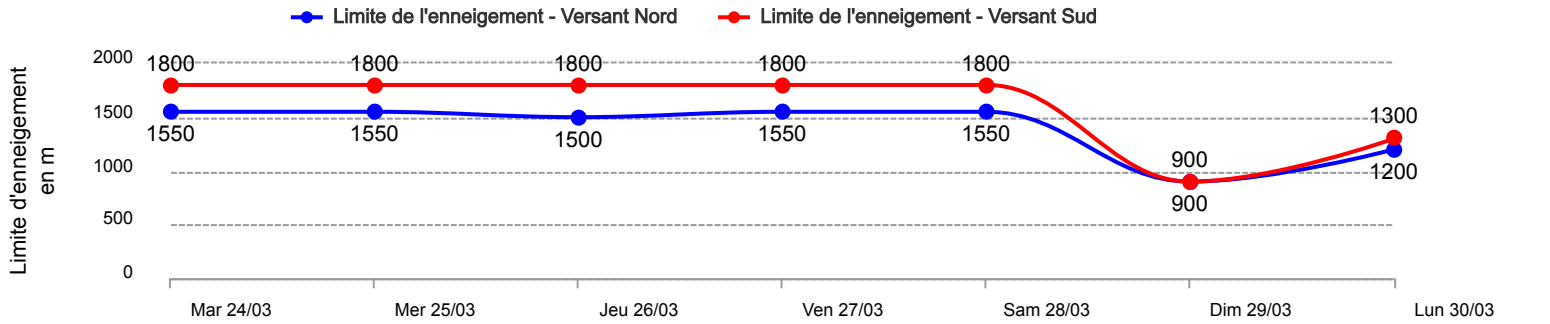

Pour consulter la vigilance en cours, veuillez vous rendre sur le site https://vigilance.meteofrance.fr/fr

Météo-France - 73 avenue de Paris, 94165 Saint-Mandé cedex - Contact : contact@meteo.fr

Rédigé par Météo-France avec la contribution des observateurs du réseau nivo-météorologiques. Partenariat : ANMSM (Maires de Stations de Montagne), DSF (Domaines Skiables de France), ADSP (Directeurs de Pistes et de la Sécurité des Stations de Sports d'Hiver) et autres acteurs de la montagne.

Bulletin neige & avalanches par téléphone au

0 892 68 10 20 Service 0,35 € / min + prix appel