GOBIERNO DE ESPAÑA
VICEPRESIDENCIA TERCERA DEL GOBIERNO
MINISTERIO PARA LA TRANSICIÓN ECOLÓGICA Y EL RETO DEMOGRÁFICO

Boletín de información nivológica y de peligro de aludes

Pirineo Catalán

aemet Agencia Estatal de Meteorología

martes, 31 de marzo de 2026

Pronóstico hasta las 24 horas del miércoles, día 1 de abril

(Válido fuera de pistas de esquí balizadas y abiertas)

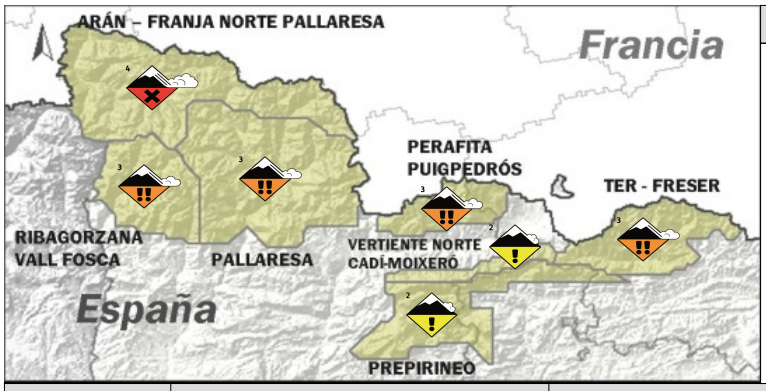

Problemas de aludes

Placas de viento

Nieve reciente

Macizo	Peligro	Problemas de aludes, cota, orientación, tamaño	Innivación observada (m)
Arán - Franja norte Pallaresa	4 — 3→4 — Fuerte	Placas de viento — 1800 — N O E S — 3 Nieve reciente — N O E S — 3	2026-03-31 N S — Cota más baja caras N
Ribagorzana - Vall Fosca	3 — 3 / 2→3 — 1800 — Durante el día — Notable	Placas de viento — 1800 — N O E S — 3 Nieve reciente — N O E S — 2	2026-03-31 N S — Cota más baja caras N
Pallaresa	3 — 3 / 2→3 — 1800 — Durante el día — Notable	Placas de viento — 1800 — N O E S — 3 Nieve reciente — N O E S — 2	2026-03-31 N S — Cota más baja caras N

AEMET. Se autoriza la reproducción de su contenido citando la fuente.

Boletín de información nivológica y de peligro de aludes

Pirineo Catalán

Perafita - Puigpedrós	3 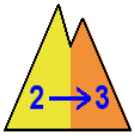 **Notable**	**Placas de viento** 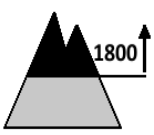  **Nieve reciente** 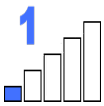	2026-03-31 Cota más baja caras N
Ter - Freser	3 **Notable**	**Placas de viento** 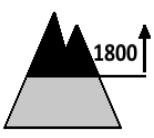  **Nieve reciente** 	2026-03-31 Cota más baja caras N
Vertiente norte Cadí - Moixeró	2 **Limitado** 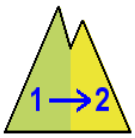	**Placas de viento** 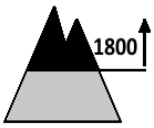 	2026-03-31 Cota más baja caras N
Prepirineo	2 **Limitado**	**Placas de viento** 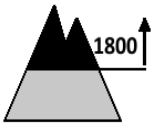 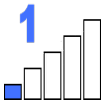	2026-03-31 Cota más baja caras N

Estado del manto y observaciones recientes

Durante las últimas horas, han continuado los procesos de transporte de la nieve con rachas muy fuertes de viento generalizadas, las temperaturas han sufrido ascensos moderados o notables y se han producido algunas precipitaciones, más significativas en el Arán (hasta 15mm), que han mermado el escaso manto existente en cotas bajas, donde han sido en forma de lluvia.

La nieve está distribuida muy irregularmente a causa del viento, formando numerosas placas de viento que se intercalan con zonas en las que aflora la antigua costra. Estas placas se han depositado sobre la propia costra, o también sobre facetas en umbrías de cotas altas. En puntos al abrigo de los vientos, se pueden encontrar acumulaciones de nieve reciente. Las antiguas capas débiles persistentes todavía pueden aparecer en niveles internos en las umbrías de cotas altas y mostrarse reactivas, aunque en general ante sobrecargas fuertes.

El manto presenta continuidad desde cotas medias, más abajo en las laderas norte que en las sur. Los espesores continúan muy por encima de lo habitual para estas fechas con valores por encima de 150-220 cm en cota 2200 en la mayoría de los sectores.

AEMET. Se autoriza la reproducción de su contenido citando la fuente.

Evolución del manto y peligro de aludes para el miércoles, día 1

NOTA: En las zonas norte de los sectores Ribagorzana-Vall Fosca y Pallaresa, colindantes al Arán-F.N.Pallaresa, también se podrá rondar el nivel de peligro 4 en cotas altas al final del día.

Problema de placas de viento. Problema de nieve reciente.

Las placas de viento se mantendrán frágiles, susceptibles de colapsar ante sobrecargas débiles y continuarán formándose a lo largo del día. Serán abundantes, sobre todo en orientaciones sur, y podrán aparecer ocasionalmente en cotas medias, así como alejadas de crestas y cordales. El tamaño de los potenciales aludes será mediano, localmente grande, incluso muy grande en el Arán-F.N.Pallaresa.

Los aludes de nieve reciente serán probables en zonas menos afectadas por el viento y con la suficiente inclinación. Podrán ser naturales y accidentales, y de tamaño pequeño o mediano, localmente grande en el Arán-F.N.Pallaresa.

Por último, en umbrías de cotas altas, no se descarta la posibilidad de activar alguna de las antiguas capas débiles persistentes más profundas, pudiendo desencadenar algún alud de tamaño grande.

Predicción meteorológica para el miércoles, día 1

Muy nuboso o cubierto en la divisoria fronteriza, con visibilidad localmente reducida, abriendo algunos claros hacia el sur. Precipitaciones débiles o moderadas, que serán persistentes en el Arán y norte de la Pallaresa. Cota de nieve en torno a 1300 metros, pudiendo ascender temporalmente hasta los 1500. Temperaturas mínimas sin cambios o en ligero ascenso. Máximas en ligero o moderado descenso. Heladas débiles, moderadas en cotas altas, donde podrán ser localmente fuertes y persistentes. Viento moderado o fuerte de componente norte, con rachas muy fuertes en cotas altas y zonas expuestas, que podrán superar los 110 km/h.

Datos en la atmósfera libre:

Altitud de la isoterma de 0 ºC: 1700 m
Altitud de la isoterma de -10 ºC: 3400 m

Viento a 1500 m: N 60 km/h
Viento a 3000 m: N 100 km/h

Evolución para el jueves día 2

Nivel de peligro sin cambios o en ligero descenso.

Escala europea de peligro de aludes

Débil | Limitado | Notable | Fuerte | Muy Fuerte

Problemas de aludes

Nieve reciente | Placas de viento | Capas débiles persistentes | Nieve húmeda | Deslizamientos basales | Sin problema evidente

AEMET. Se autoriza la reproducción de su contenido citando la fuente.

Nota1: Se recuerda que, siempre que haya nieve, la ausencia total de peligro no existe. Hay que tener presente que en circunstancias desfavorables, con aludes de tamaño 1 (alud pequeño o colada) y tamaño 2 (alud mediano), se pueden sufrir severos daños personales.

Nota2: Los BPA se elaboran en base a información meteorológica así como al estado del manto nivoso a través de sondeos puntuales. Se advierte a los usuarios de la variabilidad de esta información al extrapolarla a zonas extensas de montaña. Por ello, AEMET no se hace responsable de su uso para la toma de decisiones que conciernen a la seguridad personal, ni de los riesgos físicos o materiales de ellas derivadas.

AEMET. Se autoriza la reproducción de su contenido citando la fuente.