GOBIERNO DE ESPAÑA
VICEPRESIDENCIA TERCERA DEL GOBIERNO
MINISTERIO PARA LA TRANSICIÓN ECOLÓGICA Y EL RETO DEMOGRÁFICO

Boletín de información nivológica y de peligro de aludes

Pirineo Navarro y Aragonés

aemet Agencia Estatal de Meteorología

martes, 31 de marzo de 2026

Pronóstico hasta las 24 horas del miércoles, día 1 de abril

(Válido fuera de pistas de esquí balizadas y abiertas)

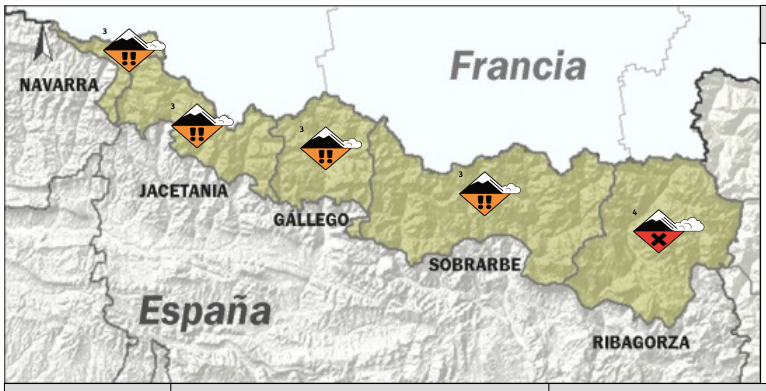

Problemas de aludes

Placas de viento

Nieve reciente

Macizo	Peligro	Problemas de aludes, cota, orientación, tamaño	Innivación observada (m)
Navarra	3 — 3 / 2→3 — 2100 — Durante el día — **Notable**	**Placas de viento** — 1800 — N O E S — 2 **Nieve reciente** — N O E S — 2	2026-03-31 N S — Cota más baja caras N
Jacetania	3 — 3 / 2→3 — 2100 — Durante el día — **Notable**	**Placas de viento** — 1800 — N O E S — 2 **Nieve reciente** — N O E S — 2	2026-03-31 N S — Cota más baja caras N
Gállego	3 — 3 / 2→3 — 2100 — Durante el día — **Notable**	**Placas de viento** — 1800 — N O E S — 2 **Nieve reciente** — N O E S — 2	2026-03-31 N S — Cota más baja caras N

AEMET. Se autoriza la reproducción de su contenido citando la fuente.

Sobrarbe	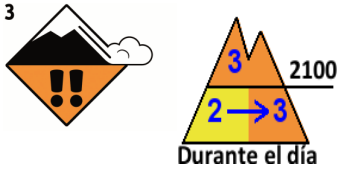 **Notable**	**Placas de viento** **Nieve reciente** 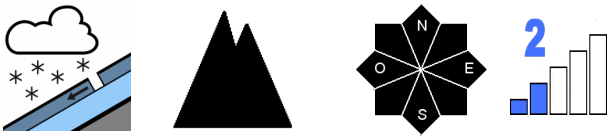	2026-03-31 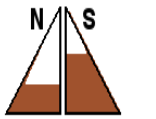 Cota más baja caras N
Ribagorza	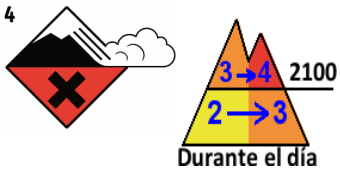 **Fuerte**	**Placas de viento** 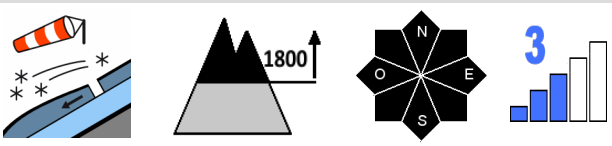 **Nieve reciente** 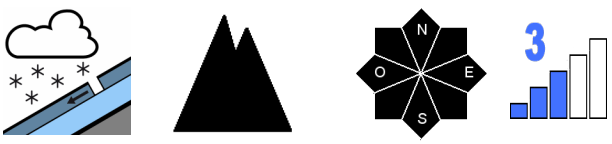	2026-03-31 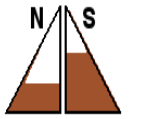 Cota más baja caras N

Estado del manto y observaciones recientes

Durante las últimas horas, han continuado los procesos de transporte de la nieve con rachas muy fuertes de viento generalizadas, las temperaturas han sufrido ascensos moderados o notables y se han producido algunas precipitaciones, más significativas en el extremo occidental, que han mermado el escaso manto existente en cotas bajas, donde han sido en forma de lluvia.

La nieve está distribuida muy irregularmente a causa del viento, formando numerosas placas de viento que se intercalan con zonas en las que aflora la antigua costra. Estas placas se han depositado sobre la propia costra, o también sobre facetas en umbrías de cotas altas. En puntos al abrigo de los vientos, se pueden encontrar acumulaciones de nieve reciente. Las antiguas capas débiles persistentes todavía aparecen en niveles internos en las umbrías de cotas altas, mostrando a veces reactividad aunque solo ante sobrecargas fuertes por el momento.

El manto presenta continuidad desde cotas medias, más abajo en las laderas norte (1600 m) que en las sur (1800 m). Los espesores continúan por encima de lo habitual para estas fechas con valores de 150-200 cm en cota 2200.

Evolución del manto y peligro de aludes para el miércoles, día 1

NOTA: En general en todas las zonas, el nivel de peligro será más elevado en el entorno de la divisoria fronteriza, disminuyendo de manera significativa en picos más al sur. Concretamente, el nivel 4 de la Ribagorza viene referido solamente a su tercio norte (área Posets-Maladeta).

Problema de placas de viento. Problema de nieve reciente.

AEMET. Se autoriza la reproducción de su contenido citando la fuente.

Las placas de viento se mantendrán frágiles, susceptibles de colapsar ante sobrecargas débiles y continuarán formándose a lo largo del día. Serán abundantes, sobre todo en orientaciones sur, y podrán aparecer ocasionalmente en cotas medias, así como alejadas de crestas y cordales. El tamaño de los potenciales aludes será mediano, localmente grande, sin descartar el muy grande en la Ribagorza norte.

Los aludes de nieve reciente serán probables en zonas menos afectadas por el viento y con la suficiente inclinación. Podrán ser naturales y accidentales, y de tamaño pequeño o mediano, localmente grande en la Ribagorza norte.

Por último, en umbrías de cotas altas, no se descarta la posibilidad de activar alguna de las antiguas capas débiles persistentes más profundas, pudiendo desencadenar algún alud de tamaño grande.

Predicción meteorológica para el miércoles, día 1

Pirineo navarro:
Muy nuboso o cubierto, con visibilidad localmente reducida. Precipitaciones débiles o localmente moderadas. Cota de nieve variando entre 1300 y 1500 metros. Temperaturas en ligero ascenso, o mínimas sin cambios. Heladas débiles, moderadas en cotas altas. Viento fuerte de componente norte, con rachas muy fuertes en cotas altas y zonas expuestas.

Pirineo aragonés:
Muy nuboso o cubierto en la divisoria fronteriza, con visibilidad localmente reducida, abriendo algunos claros hacia el sur. Precipitaciones débiles o moderadas, más intensas y frecuentes en la divisoria fronteriza, donde podrán ser localmente persistentes. Cota de nieve en torno a 1400-1500 metros, descendiendo al final del día hasta unos 1300. Temperaturas sin cambios o en ligero ascenso. Heladas débiles, moderadas en cotas altas, donde podrán ser localmente fuertes y persistentes. Viento moderado o fuerte de componente norte, con rachas muy fuertes en cotas altas y zonas expuestas, que podrán superar los 110 km/h.

Datos en la atmósfera libre:

Altitud de la isoterma de 0 ºC: 1800 m
Altitud de la isoterma de -10 ºC: 3500 m

Viento a 1500 m: N 50 km/h
Viento a 3000 m: N 110 km/h

Evolución para el jueves día 2

Nivel de peligro sin cambios o en ligero descenso.

(Información elaborada a partir de los datos recibidos de los refugios de Linza, Lizara, Panticosa, Bachimaña, Góriz, Pineta, Estós, Angel Orús, La Renclusa y Belagua y de la estación de esquí de Panticosa (lagos))

Escala europea de peligro de aludes

Débil | Limitado | Notable | Fuerte | Muy Fuerte

Problemas de aludes

Nieve reciente | Placas de viento | Capas débiles persistentes | Nieve húmeda | Deslizamientos basales | Sin problema evidente

AEMET. Se autoriza la reproducción de su contenido citando la fuente.

Nota1: Se recuerda que, siempre que haya nieve, la ausencia total de peligro no existe. Hay que tener presente que en circunstancias desfavorables, con aludes de tamaño 1 (alud pequeño o colada) y tamaño 2 (alud mediano), se pueden sufrir severos daños personales.

Nota2: Los BPA se elaboran en base a información meteorológica así como al estado del manto nivoso a través de sondeos puntuales. Se advierte a los usuarios de la variabilidad de esta información al extrapolarla a zonas extensas de montaña. Por ello, AEMET no se hace responsable de su uso para la toma de decisiones que conciernen a la seguridad personal, ni de los riesgos físicos o materiales de ellas derivadas.

AEMET. Se autoriza la reproducción de su contenido citando la fuente.