Mittwoch 01.04.2026

Veröffentlicht am 31.03.2026 um 17:00

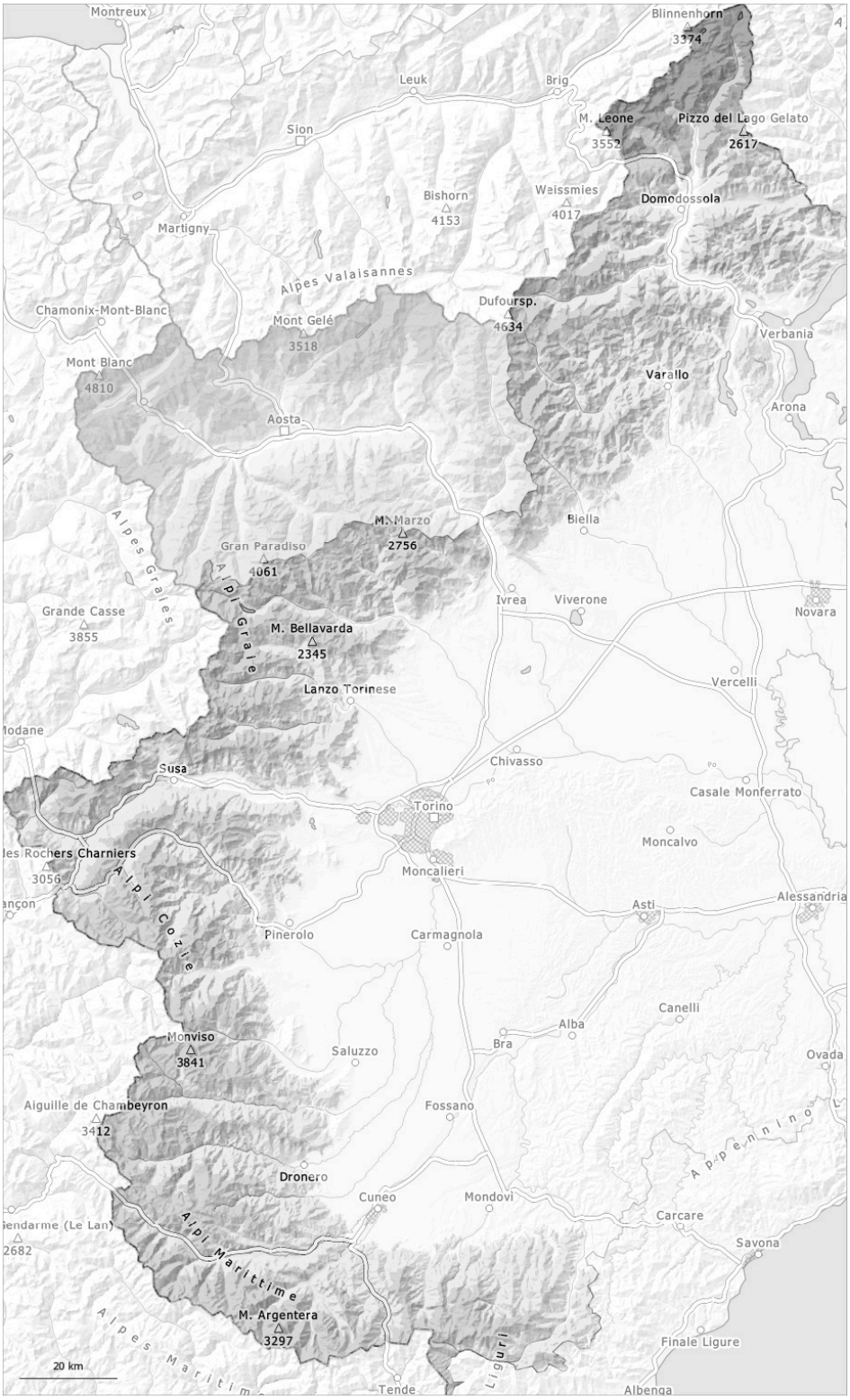

1	2	3	4	5
gering	mäßig	erheblich	groß	sehr groß

Gefahrenstufe 3 - Erheblich

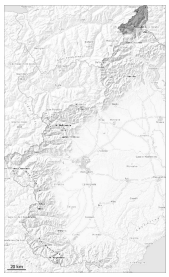

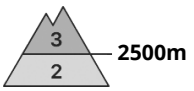

Tendenz: Lawinengefahr bleibt gleich
am Donnerstag, den 02.04.2026

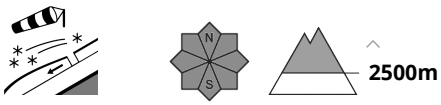

Triebschnee

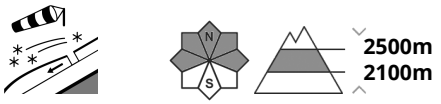

Triebschnee

Frischer Triebschnee ist die Hauptgefahr.

Seit Sonntag fielen oberhalb von rund 1600 m 20 bis 40 cm Schnee, lokal auch mehr. Seit Montag blies der Wind stark.

Die gut sichtbaren Triebschneeansammlungen der letzten zwei Tage können vor allem an den Expositionen West über Nord bis Ost oberhalb der Waldgrenze von einzelnen Wintersportlern ausgelöst werden. Die Lawinen können an Triebschneehängen in den verschiedenen Triebschneeschichten ausgelöst werden und groß werden.

Vorsicht vor allem an Übergängen von wenig zu viel Schnee sowie in Rinnen, Mulden und hinter Geländekanten in mittleren und hohen Lagen.

Am Nachmittag steigt die Auslösebereitschaft von trockenen und feuchten Lawinen vor allem an sehr steilen Sonnenhängen allmählich an.

Schneedecke

Gefahrenmuster gm.6: lockerer schnee und wind

Mit starkem Nordostwind entstanden seit Montag vor allem kammfern teils dicke Triebschneeansammlungen.
Zudem entstanden auch in windgeschützten Lagen weiche Triebschneeansammlungen. Sie sind recht häufig aber schwer zu erkennen.

Die nächtliche Abstrahlung war gut. Tiefe und mittlere Lagen sowie steile Sonnenhänge: Die Schneeoberfläche ist tragfähig gefroren weicht im Tagesverlauf auf.

In Kammlagen im Hochgebirge liegen je nach Windeinfluss sehr unterschiedliche Schneehöhen.

Übergänge von wenig zu viel Schnee: Verschiedene Triebschneeschichten liegen auf einer harten Kruste.

Tendenz

Donnerstag: Mit der tageszeitlichen Erwärmung und der Sonneneinstrahlung steigt die Auslösebereitschaft von feuchten und nassen Lawinen an sehr steilen Sonnenhängen etwas an. Dies auch an Felswandfüßen.

Gefahrenstufe 2 - Mäßig

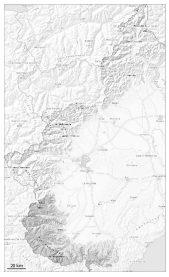

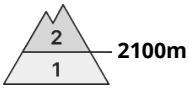

Tendenz: Lawinengefahr bleibt gleich
am Donnerstag, den 02.04.2026

Triebschnee

2100m

Die Triebschneeansammlungen sind gut erkennbar aber kritisch zu beurteilen.

Mit Neuschnee und mäßigem bis starkem Wind aus nordöstlichen Richtungen entstanden in den letzten Tagen vor allem in Rinnen, Mulden und hinter Geländekanten gut sichtbare Triebschneeansammlungen. Diese können von einzelnen Wintersportlern ausgelöst werden.

Die Lawinen können an sehr steilen Hängen in den verschiedenen Triebschneeschichten anreißen und mittlere Größe erreichen.

Schneedecke

Gefahrenmuster gm.6: lockerer schnee und wind

Seit Montag blies der Wind verbreitet stark. In Gipfellagen liegen je nach Windeinfluss sehr unterschiedliche Schneehöhen.

Besonders Hänge hohe Lagen und Hochgebirge: Im oberen Teil der Schneedecke sind Schwachschichten vorhanden.

Vor allem Sonnenhänge tiefe und mittlere Lagen: Die Schneeoberfläche ist tragfähig gefroren und weicht im Tagesverlauf auf.

Die Schneedecke ist in tiefen und mittleren Lagen gut verfestigt.

Tendenz

Mit der tageszeitlichen Erwärmung und der Sonneneinstrahlung steigt die Auslösebereitschaft von feuchten und nassen Lawinen an sehr steilen Sonnenhängen etwas an. Dies auch an Felswandfüßen.

Gefahrenstufe 2 - Mäßig

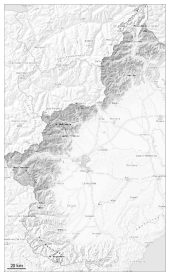

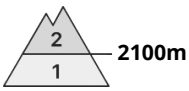

Tendenz: Lawinengefahr bleibt gleich
am Donnerstag, den 02.04.2026

Triebschnee

2100m

Frischer Triebschnee ist die Hauptgefahr.

Seit Sonntag fiel gebietsweise etwas Schnee. Seit Montag blies der Wind stark. Die gut sichtbaren Triebschneeansammlungen der letzten zwei Tage können vor allem an den Expositionen West über Nord bis Ost oberhalb der Waldgrenze von einzelnen Wintersportlern ausgelöst werden. Die Lawinen können an Triebschneehängen in den verschiedenen Triebschneeschichten ausgelöst werden und mittlere Größe erreichen.

Am Nachmittag steigt die Auslösebereitschaft von trockenen und feuchten Lawinen vor allem an sehr steilen Sonnenhängen allmählich an.

Schneedecke

Gefahrenmuster gm.6: lockerer schnee und wind

Seit Sonntag fielen gebietsweise oberhalb von rund 1700 m 5 bis 20 cm Schnee, lokal auch mehr.
Mit starkem Nordwestwind entstanden seit Montag vor allem kammfern harte Triebschneeansammlungen.
Die nächtliche Abstrahlung war gut. Tiefe und mittlere Lagen sowie steile Sonnenhänge: Die Schneeoberfläche ist tragfähig gefroren weicht im Tagesverlauf auf.

In Kammlagen in hohen Lagen liegen je nach Windeinfluss sehr unterschiedliche Schneehöhen.
Verschiedene Triebschneeschichten liegen verbreitet auf einer harten Kruste.

Unterhalb der vom Wind erodierten Gipfel, oberhalb von etwa 1600 m, liegt mehr Schnee als im saisonalen Durchschnitt.

Tendenz

Donnerstag: Mit der tageszeitlichen Erwärmung und der Sonneneinstrahlung steigt die Auslösebereitschaft von feuchten und nassen Lawinen an sehr steilen Sonnenhängen etwas an. Dies auch an Felswandfüßen.