Mittwoch 01.04.2026

Veröffentlicht am 31.03.2026 um 17:00

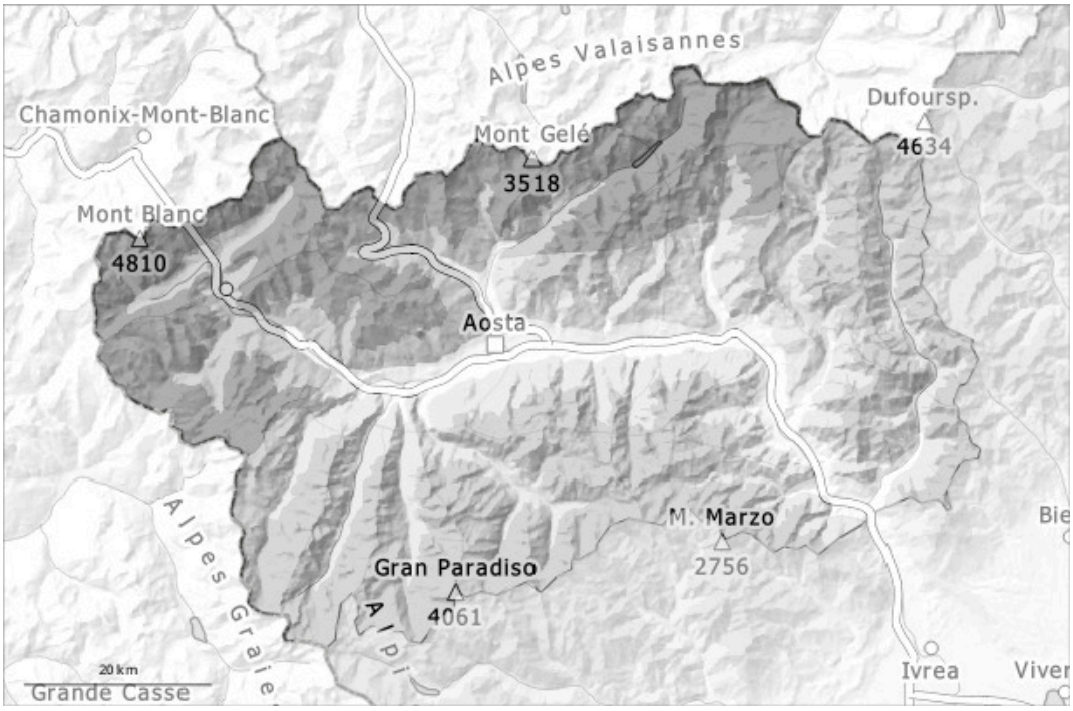

1	2	3	4	5
gering	mäßig	erheblich	groß	sehr groß

Gefahrenstufe 3 - Erheblich

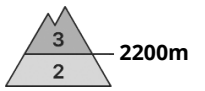

Tendenz: Lawinengefahr nimmt ab
am Donnerstag, den 02.04.2026

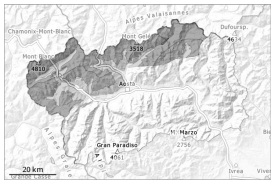

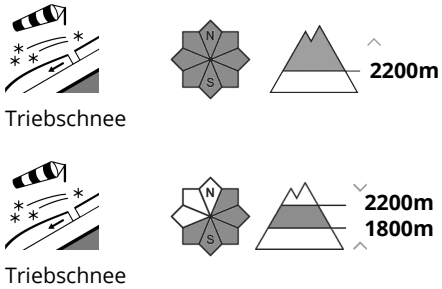

Frischer Triebschnee ist die Hauptgefahr.

Der Wind blies stark. Mit Neuschnee und starkem Wind aus nördlichen Richtungen entstanden auch kammfern weitere Triebschneeansammlungen. Entlang der Grenze zu Frankreich und entlang der Grenze zur Schweiz sind diese Gefahrenstellen häufiger.
Die Triebschneeansammlungen können ausgelöst werden, Vorsicht an sehr steilen Hängen an Übergängen von wenig zu viel Schnee wie z.B. bei der Einfahrt in Rinnen und Mulden. Wummgeräusche sind Alarmzeichen. Die Triebschneeansammlungen sind kaum erkennbar.
Die trockenen Lawinen können besonders dort in den verschiedenen Triebschneeschichten anreißen und mittlere Größe erreichen.
Touren erfordern eine überlegte Routenwahl.
Die spontane Lawinenaktivität nimmt mit der Erwärmung und der Sonneneinstrahlung allmählich zu, v.a. an sehr steilen Sonnenhängen. Im Tagesverlauf sind feuchte Rutsche möglich.

Schneedecke

Gefahrenmuster gm.6: lockerer schnee und wind

In den letzten Stunden fielen lokal oberhalb von rund 2000 m 10 bis 20 cm Schnee, lokal auch mehr. Bis Mittwoch bläst der Wind stark.
Seit Sonntag fielen lokal oberhalb von rund 2000 m 5 bis 20 cm Schnee.
Der Wind blies verbreitet stark bis stürmisch. Verbreitet liegen je nach Windeinfluss sehr unterschiedliche Schneehöhen. Hohe Lagen und Hochgebirge: Mit zunehmender Höhe nimmt die Schneedecke ab und wird ungleichmäßiger. In mittleren Höhenlagen ist die Schneedecke oft besser, da sie dort weniger vom Wind beeinflusst wird.
Der obere Teil der Schneedecke ist hart, mit einer oft tragfähigen Kruste an der Oberfläche, besonders in Kamm- und Passlagen. Auf der harten Kruste besteht im Steilgelände Absturzgefahr.
Der obere Teil der Schneedecke ist weich, mit einer lockeren Oberfläche, v.a. in windgeschützten Lagen.
Die Sonneneinstrahlung führte zu einer Setzung der Schneedecke.
In der Schneedecke sind v.a. an steilen Schattenhängen Schwachschichten vorhanden.

Tendenz

Die Wetterbedingungen erlauben eine Verfestigung der Triebschneeansammlungen. Die Gefahrenstellen liegen an Triebschneehängen in der Höhe.

Gefahrenstufe 2 - Mäßig

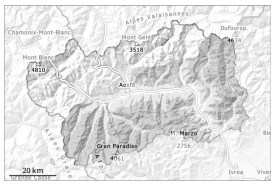

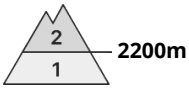

Tendenz: Lawinengefahr bleibt gleich
am Donnerstag, den 02.04.2026 →

Triebschnee

Frischer Triebschnee ist die Hauptgefahr.

Mit teils starkem Wind wuchsen die Triebschneeansammlungen etwas an. Diese können stellenweise von einzelnen Wintersportlern ausgelöst werden, Vorsicht an sehr steilen Hängen an Übergängen von wenig zu viel Schnee wie z.B. bei der Einfahrt in Rinnen und Mulden. Die Triebschneeansammlungen sind kaum erkennbar.
Die trockenen Lawinen können besonders an Triebschneehängen in den verschiedenen Triebschneeschichten anreißen und mittlere Größe erreichen.
Auf der harten Kruste besteht im Steilgelände Absturzgefahr, v.a. an sehr steilen Sonnenhängen.

Schneedecke

Gefahrenmuster gm.6: lockerer schnee und wind

In den letzten Stunden fielen lokal oberhalb von rund 2000 m 5 bis 10 cm Schnee, lokal auch weniger. Bis Mittwoch bläst der Wind stark.
Seit Sonntag fielen lokal oberhalb von rund 2000 m 2 bis 10 cm Schnee, lokal auch weniger.
Der Wind blies verbreitet stark bis stürmisch. Verbreitet liegen je nach Windeinfluss sehr unterschiedliche Schneehöhen. Hohe Lagen und Hochgebirge: Mit zunehmender Höhe nimmt die Schneedecke ab und wird ungleichmäßiger. In mittleren Höhenlagen ist die Schneedecke oft besser, da sie dort weniger vom Wind beeinflusst wird.
Der obere Teil der Schneedecke ist hart, mit einer oft tragfähigen Kruste an der Oberfläche, besonders in Kamm- und Passlagen. Auf der harten Kruste besteht im Steilgelände Absturzgefahr.
Der obere Teil der Schneedecke ist weich, mit einer lockeren Oberfläche, v.a. in windgeschützten Lagen.
Die Sonneneinstrahlung führte zu einer Setzung der Schneedecke.
In der Schneedecke sind v.a. an steilen Schattenhängen Schwachschichten vorhanden.

Tendenz

Die Wetterbedingungen erlauben eine Verfestigung der Triebschneeansammlungen. Die Gefahrenstellen liegen an Triebschneehängen in der Höhe.