Mercoledì 01.04.2026

Pubblicato il 31.03.2026 alle ore 17:00

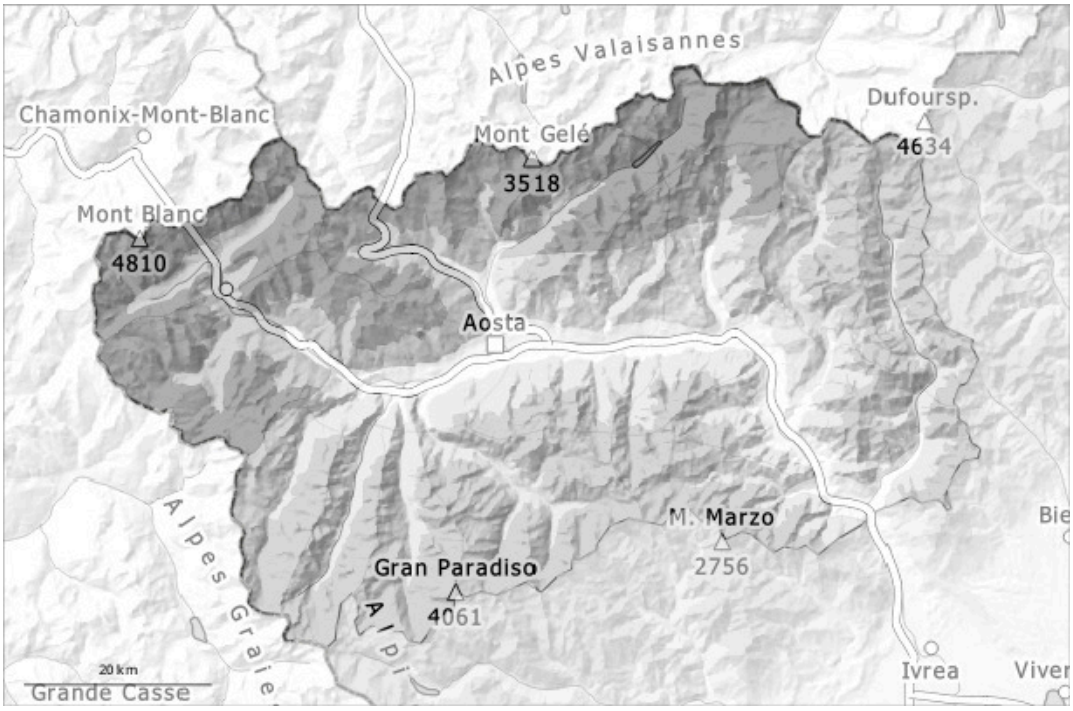

1	2	3	4	5
debole	moderato	marcato	forte	molto forte

Grado di pericolo 3 - Marcato

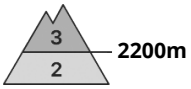

Tendenza: pericolo valanghe in diminuzione
per Giovedì il 02.04.2026

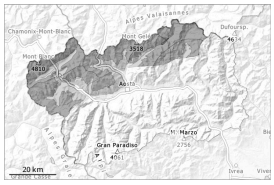

Lastrone da vento

Lastrone da vento

La neve ventata recente è la principale fonte di pericolo.

Il vento è stato forte. Con neve fresca e vento forte proveniente dai quadranti settentrionali anche nelle zone lontano dalle creste si sono formati ulteriori accumuli di neve ventata. Lungo il confine con la Francia e lungo il confine con la Svizzera, questi punti pericolosi sono più frequenti.
Gli accumuli di neve ventata possono subire un distacco provocato, attenzione sui pendii molto ripidi nelle zone di passaggio da poca a molta neve come p.es. all'ingresso di conche e canaloni. I rumori di "whum" sono campanelli di allarme. Gli accumuli di neve ventata sono a malapena individuabili.
Principalmente qui le valanghe asciutte possono coinvolgere i vari strati di neve ventata e raggiungere dimensioni medie.
Le escursioni richiedono un'attenta scelta dell'itinerario.
Con il rialzo termico e l'irradiazione solare, l'attività di valanghe spontanee aumenterà progressivamente, principalmente sui pendii soleggiati molto ripidi. Nel corso della giornata saranno possibili colate umide.

Manto nevoso

Situazione tipo st.6: neve a debole coesione e vento

A livello locale nelle ultime ore sono caduti da 10 a 20 cm di neve al di sopra dei 2000 m circa, localmente anche di più. Fino a mercoledì il vento sarà forte.
A livello locale da domenica sono caduti da 5 a 20 cm di neve al di sopra dei 2000 m circa.
In molte regioni, il vento è stato da forte a tempestoso. In molti punti l'innevamento è estremamente variabile a seconda dell'azione del vento. Ad alta quota e in alta montagna: Salendo di quota l'innevamento si riduce e diventa disomogeneo. Risulta spesso migliore alle quote intermedie meno interessate dal vento.
La parte superiore del manto nevoso è dura, con una crosta spesso portante in superficie, soprattutto nelle zone in prossimità delle creste e dei passi. Sulla crosta dura sussiste un pericolo di caduta nelle zone ripide.
La parte superiore del manto nevoso è soffice, con una superficie a debole coesione, principalmente nelle zone al riparo dal vento.
L'irradiazione solare ha causato un assestamento del manto nevoso.

Specialmente sui pendii ombreggiati ripidi, all'interno del manto nevoso si trovano strati fragili.

Tendenza

Le condizioni meteo consentiranno un consolidamento degli accumuli di neve ventata. I punti pericolosi si trovano sui pendii carichi di neve ventata in quota.

Grado di pericolo 2 - Moderato

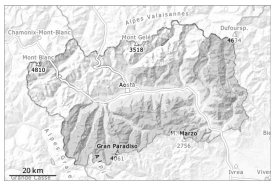

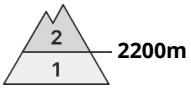

Tendenza: pericolo valanghe stabile
per Giovedì il 02.04.2026

Lastrone da vento

La neve ventata recente è la principale fonte di pericolo.

Con il vento a tratti forte, gli accumuli di neve ventata sono leggermente cresciuti. Questi possono in alcuni punti distaccarsi in seguito al passaggio di un singolo appassionato di sport invernali, attenzione sui pendii molto ripidi nelle zone di passaggio da poca a molta neve come p.es. all'ingresso di conche e canaloni. Gli accumuli di neve ventata sono a malapena individuabili.
Principalmente sui pendii carichi di neve ventata le valanghe asciutte possono coinvolgere i vari strati di neve ventata e raggiungere dimensioni medie.
Sulla crosta dura sussiste un pericolo di caduta nelle zone ripide, principalmente sui pendii soleggiati molto ripidi.

Manto nevoso

Situazione tipo st.6: neve a debole coesione e vento

A livello locale nelle ultime ore sono caduti da 5 a 10 cm di neve al di sopra dei 2000 m circa, localmente anche meno. Fino a mercoledì il vento sarà forte.
A livello locale da domenica sono caduti da 2 a 10 cm di neve al di sopra dei 2000 m circa, localmente anche meno.
In molte regioni, il vento è stato da forte a tempestoso. In molti punti l'innevamento è estremamente variabile a seconda dell'azione del vento. Ad alta quota e in alta montagna: Salendo di quota l'innevamento si riduce e diventa disomogeneo. Risulta spesso migliore alle quote intermedie meno interessate dal vento.
La parte superiore del manto nevoso è dura, con una crosta spesso portante in superficie, soprattutto nelle zone in prossimità delle creste e dei passi. Sulla crosta dura sussiste un pericolo di caduta nelle zone ripide.
La parte superiore del manto nevoso è soffice, con una superficie a debole coesione, principalmente nelle zone al riparo dal vento.
L'irradiazione solare ha causato un assestamento del manto nevoso.
Specialmente sui pendii ombreggiati ripidi, all'interno del manto nevoso si trovano strati fragili.

Tendenza

Le condizioni meteo consentiranno un consolidamento degli accumuli di neve ventata. I punti pericolosi si trovano sui pendii carichi di neve ventata in quota.