Mercoledì 01.04.2026

Pubblicato il 31.03.2026 alle ore 17:00

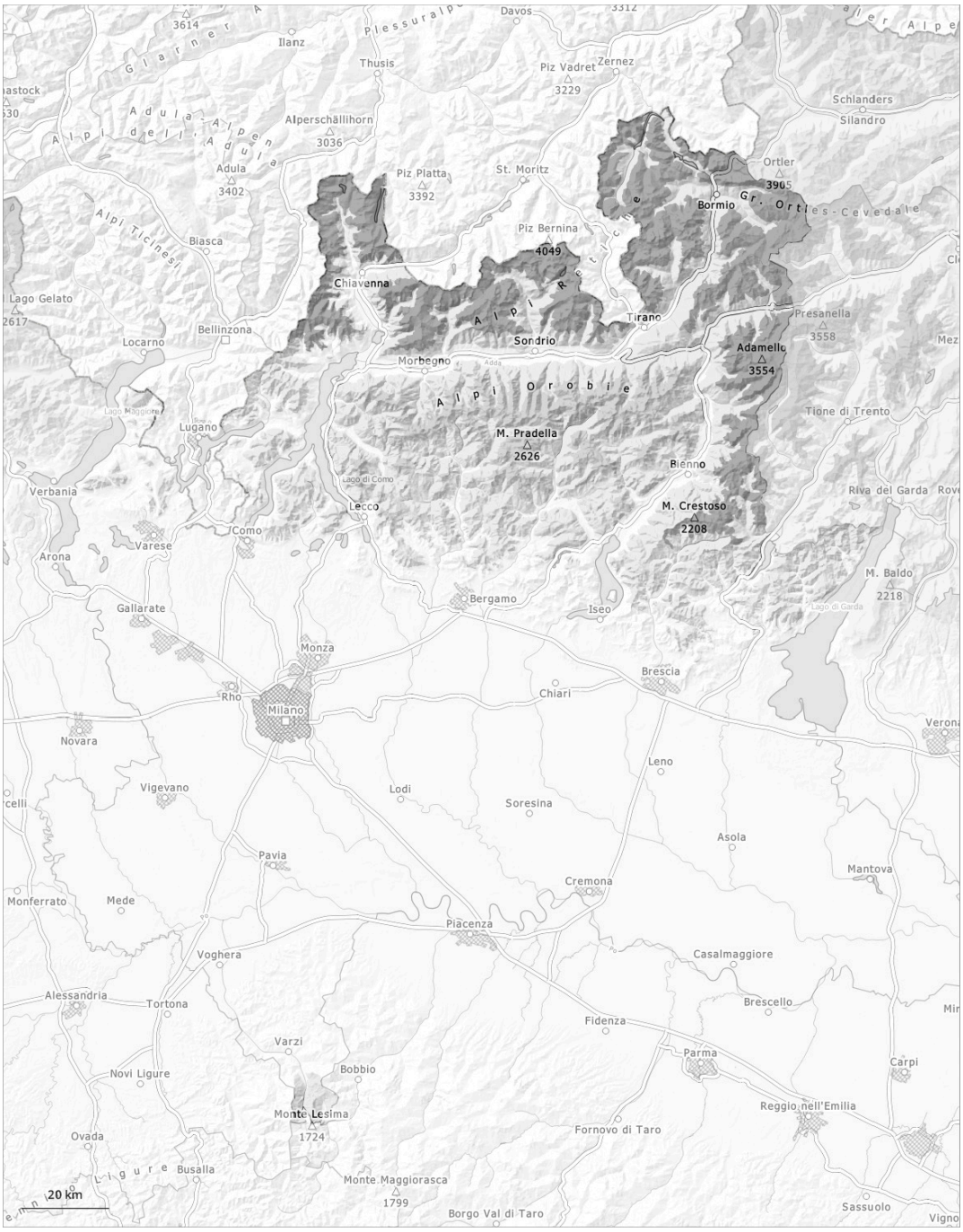

1	2	3	4	5
debole	moderato	marcato	forte	molto forte

Grado di pericolo 3 - Marcato

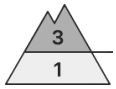

Limite del bosco

Tendenza: pericolo valanghe stabile
per Giovedì il 02.04.2026

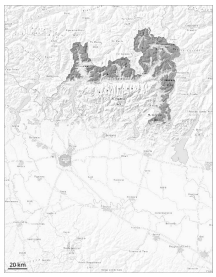

Lastrone da vento

Limite del bosco

Strati deboli persistenti

1900m

Con neve fresca e vento, il numero e le dimensioni dei punti pericolosi aumenteranno.

Con neve fresca e vento forte proveniente dai quadranti settentrionali a tutte le esposizioni si formeranno ulteriori accumuli di neve ventata. I vecchi accumuli di neve ventata verranno in parte innevati e saranno quindi difficilmente individuabili. I punti pericolosi si trovano soprattutto nelle basi di pareti rocciose, come pure nelle zone in prossimità delle creste, nei canaloni e nelle conche. Gli accumuli di neve ventata possono subire un distacco in seguito al passaggio di un singolo appassionato di sport invernali.
Sui pendii esposti a nord ovest, nord e nord est, all'interno del manto di neve vecchia si trovano strati fragili. Le valanghe possono coinvolgere il manto di neve vecchia, soprattutto sui pendii esposti a nord ovest, nord e nord est, raggiungere grandi dimensioni.

Manto nevoso

Situazione tipo st.6: neve a debole coesione e vento | st.1: strato debole persistente basale

La poca neve fresca e soprattutto gli accumuli di neve ventata che si sono formati con il vento di forte intensità poggiano su una sfavorevole superficie del manto di neve vecchia.
Principalmente sui pendii ombreggiati, all'interno del manto di neve vecchia si trovano isolati strati fragili. In alcuni punti, le valanghe possono subire un distacco negli strati profondi del manto nevoso soprattutto sui pendii esposti a nord ovest, nord e nord est.
Il sole e il calore causeranno nel corso della giornata soprattutto sui pendii soleggiati un inumidimento del manto nevoso.

Grado di pericolo 2 - Moderato

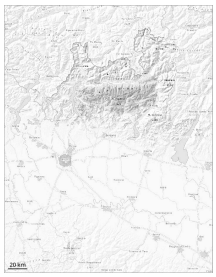

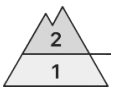

1500m

Tendenza: pericolo valanghe stabile
per Giovedì il 02.04.2026

Lastrone da vento

1500m

Neve bagnata

1300m

Neve ventata e neve bagnata sono la principale fonte di pericolo.

Soprattutto sui pendii ripidi, sono possibili isolate valanghe di neve a lastroni di dimensioni medio-piccole al di sopra dei 1400 m circa.
In prossimità delle cime, la situazione valanghiva è a livello locale pericolosa. Gli ultimi accumuli di neve ventata e possono facilmente subire un distacco.
Le valanghe possono trascinare l'interno manto nevoso e in parte raggiungere dimensioni medie.

Manto nevoso

Situazione tipo st.10: situazione primaverile | st.6: neve a debole coesione e vento

La poca neve fresca e soprattutto gli accumuli di neve ventata che si sono formati con il vento di forte intensità poggiano su una sfavorevole superficie del manto di neve vecchia.
A partire dalla mattinata il calore causerà soprattutto sui pendii soleggiati in parte un progressivo ammorbidimento del manto nevoso.

Grado di pericolo 1 - Debole

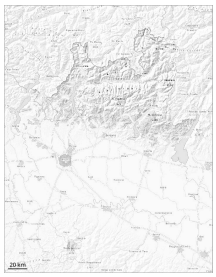

Tendenza: pericolo valanghe stabile
per Giovedì il 02.04.2026

Neve bagnata

1300m

Lastrone da vento

1500m

Neve ventata e neve bagnata sono la principale fonte di pericolo.

In prossimità delle cime, la situazione valanghiva è a livello locale per lo più favorevole. Gli ultimi accumuli di neve ventata sono per lo più piccoli e possono subire un distacco soprattutto in seguito a un forte sovraccarico nelle zone marginali.
Con il rialzo termico diurno, nel corso della giornata il pericolo di valanghe bagnate aumenterà. Al di sopra dei 1500 m circa sono possibili piccole valanghe di piccole dimensioni.

Manto nevoso

Situazione tipo st.10: situazione primaverile

Il manto nevoso è stabile a livello generale. La poca neve fresca e soprattutto gli accumuli di neve ventata che si sono formati con il vento di forte intensità poggiano su una sfavorevole superficie del manto di neve vecchia.