Mittwoch 01.04.2026

Veröffentlicht am 31.03.2026 um 17:00

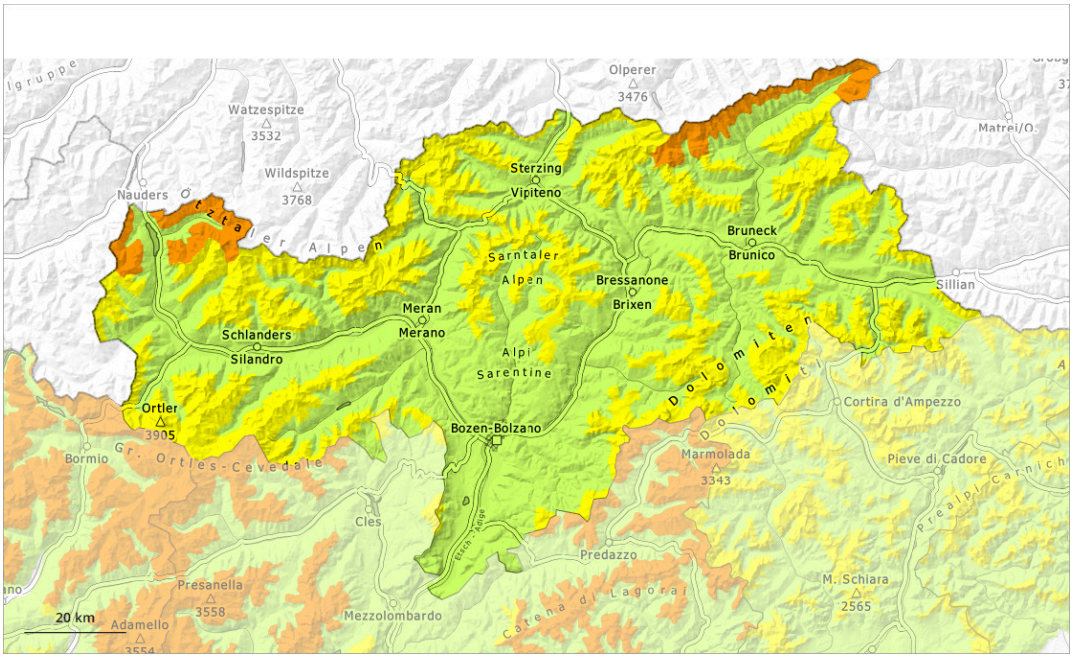

1	2	3	4	5
gering	mäßig	erheblich	groß	sehr groß

Gefahrenstufe 3 - Erheblich

Waldgrenze

Tendenz: Lawinengefahr nimmt ab
am Donnerstag, den 02.04.2026

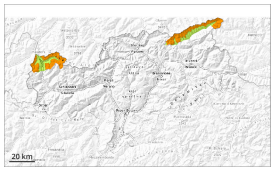

Triebschnee

Waldgrenze

Altschnee

2200m

Triebschnee ist die Hauptgefahr. Schwachen Altschnee vorsichtig beurteilen.

Mit Neuschnee und starkem bis stürmischem Wind entstanden an allen Expositionen gut sichtbare Triebschneeansammlungen. Mit teils starkem Nordostwind entstehen am Mittwoch weitere Triebschneeansammlungen. Diese können oberhalb der Waldgrenze leicht ausgelöst werden. Vorsicht vor allem an Felswandfüßen und hinter Geländekanten sowie in Kammlagen, Rinnen und Mulden. Lawinen sind meist mittelgroß. Risse beim Betreten der Schneedecke können auf die Gefahr hinweisen.

Zudem können vereinzelt Lawinen in bodennahe Schichten der Schneedecke durchreißen und groß werden, besonders an West-, Nord- und Osthängen oberhalb von rund 2200 m und an Südhängen in der Höhe.

Mit der tageszeitlichen Erwärmung und der Sonneneinstrahlung sind Lockerschneelawinen zu erwarten, aber meist nur kleine. Dies vor allem an extrem steilen Sonnenhängen.

Schneedecke

Gefahrenmuster gm.6: lockerer schnee und wind | gm.1: bodennahe schwachschicht

Es fielen 10 bis 20 cm Schnee, lokal auch mehr. Der teilweise stürmische Wind hat den Neuschnee verfrachtet. Die verschiedenen Triebschneeansammlungen sind teilweise schlecht miteinander verbunden.

Die Altschneedecke ist stellenweise schwach, besonders an West-, Nord- und Osthängen oberhalb von rund 2200 m und an Südhängen in der Höhe.

Tendenz

Triebschnee und schwacher Altschnee sind die Hauptgefahr.

Gefahrenstufe 2 - Mäßig

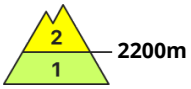

Tendenz: Lawinengefahr bleibt gleich
am Donnerstag, den 02.04.2026

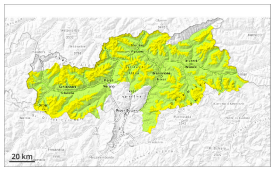

Triebschnee

Altschnee

Triebschnee ist die Hauptgefahr. Schwachen Altschnee beachten.

Mit stürmischem Nordwind entstanden an allen Expositionen gut sichtbare Triebschneeansammlungen. Mit teils starkem Nordostwind entstehen am Mittwoch weitere Triebschneeansammlungen. Diese können oberhalb von rund 2200 m schon von einzelnen Wintersportlern ausgelöst werden. Vorsicht vor allem an Felswandfüßen und hinter Geländekanten sowie in Kammlagen, Rinnen und Mulden. Lawinen sind meist mittelgroß.

Zudem können vereinzelt Lawinen in bodennahe Schichten der Schneedecke durchreißen und groß werden, besonders an West-, Nord- und Osthängen oberhalb von rund 2200 m und an Südhängen in der Höhe.

Risse beim Betreten der Schneedecke können auf die Gefahr hinweisen.

Schneedecke

Gefahrenmuster gm.6: lockerer schnee und wind | gm.1: bodennahe schwachschicht

Es fiel gebietsweise etwas Schnee. Der teilweise stürmische Wind hat Neu- und Altschnee verfrachtet. Die verschiedenen Triebschneeansammlungen sind teilweise noch schlecht miteinander verbunden.

Die Altschneedecke ist stellenweise schwach, besonders an West-, Nord- und Osthängen oberhalb von rund 2200 m und an Südhängen in der Höhe.

Tendenz

Triebschnee und schwachen Altschnee beachten.

Gefahrenstufe 2 - Mäßig

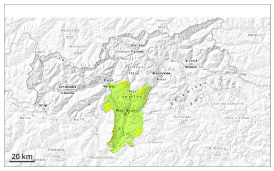

Waldgrenze

Tendenz: Lawinengefahr nimmt ab
am Donnerstag, den 02.04.2026

Triebschnee

Waldgrenze

Frischen Triebschnee vorsichtig beurteilen.

Triebschneeansammlungen sind vor allem an den Expositionen West über Nord bis Ost oberhalb der Waldgrenze teils störanfällig. Lawinen können sehr vereinzelt in bodennahe Schichten der Schneedecke durchreißen und vereinzelt mittlere Größe erreichen.

Schneedecke

Gefahrenmuster gm.6: lockerer schnee und wind | gm.1: bodennahe schwachschicht

Der Wind bläst mäßig bis stark. Der Wind hat Schnee verfrachtet. Es entstanden teils störanfällige Triebschneeansammlungen.

Tendenz

Frischen Triebschnee vorsichtig beurteilen.