ICGC Institut Cartogràfic i Geològic de Catalunya

Servei Meteorològic de Catalunya meteo.cat

Boletín de peligro de aludes para el Pirineo de Catalunya
Del 31/03/2026 al 01/04/2026

(Válido fuera pistas de esquí y zonas no controladas)

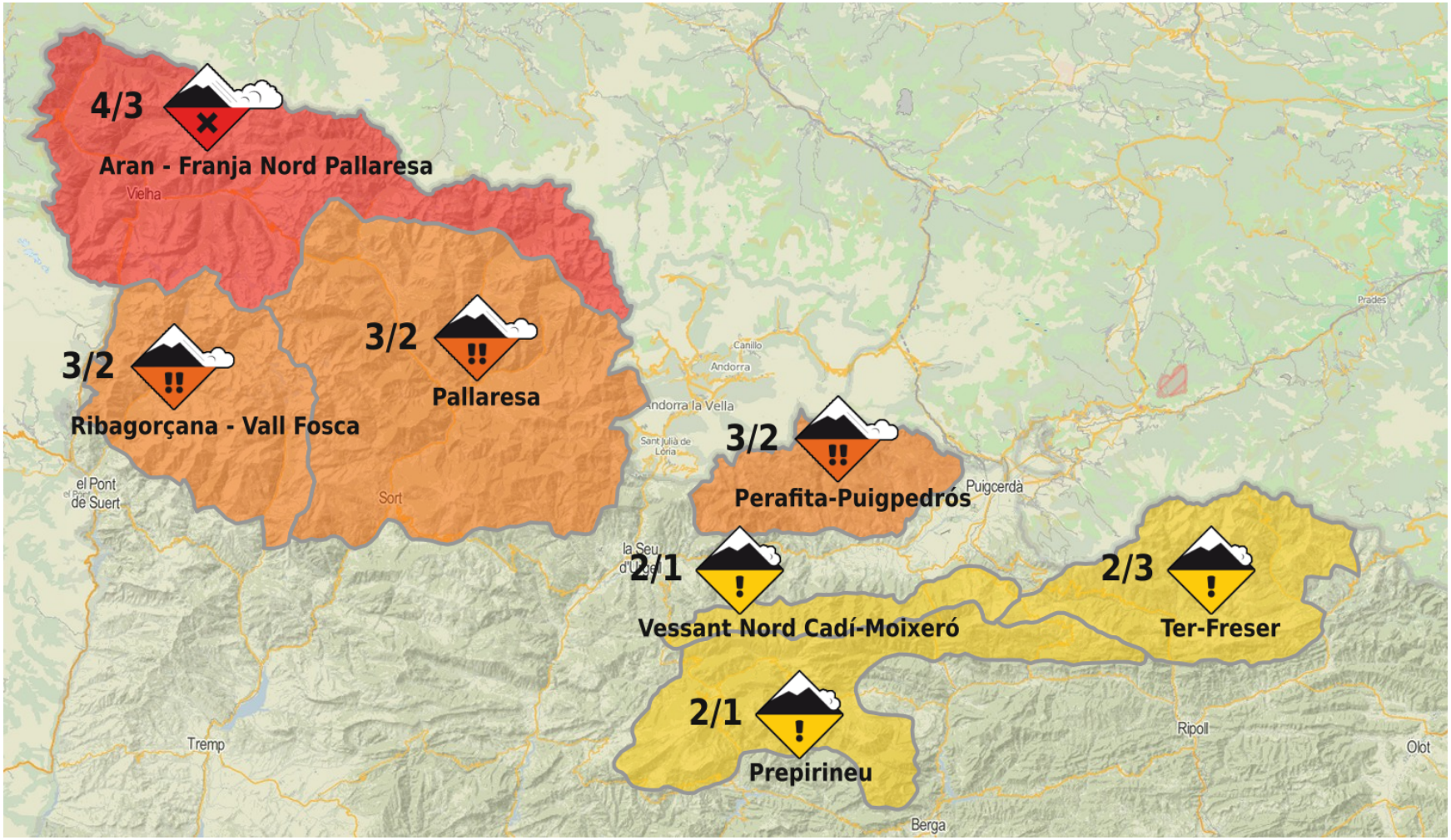

5 MUY FUERTE	4 FUERTE	3 NOTABLE	2 LIMITADO	1 DÉBIL

ICGC Institut Cartogràfic i Geològic de Catalunya

Servei Meteorològic de Catalunya meteo.cat

Boletín de peligro de aludes Aran - Franja Nord Pallaresa Del 31/03/2026 al 01/04/2026

(Válido fuera pistas de esquí y zonas no controladas)

FUERTE (4) a partir de mediodia NOTABLE (3) hasta entonces.

Situación primaria

Nieve venteada

Distribución

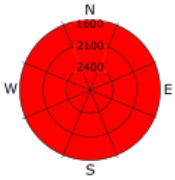

Tamaño

Origen

Tendencia

Situación secundaria

Nieve reciente

Distribución

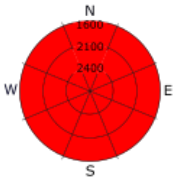

Tamaño

Origen

Tendencia

Estado del manto nivoso

Las nevadas y el viento continuarán siendo las protagonistas entre el martes y el miércoles, con acumulaciones que podrían rondar los 50 cm en total. Se formarán placas de viento en diferentes sotaventos, las más destacables en orientaciones sur de la Franja Norte de la Pallaresa. En estos lugares se podrían desprender de forma natural aludes de tamaño 4, suficiente para llegar a fondo de valle y recorrer más de 50 m en terreno llano. En el resto del sector, los aludes de placa serán en conjunto de tamaño 3, suficiente para enterrar a un grupo de personas. También se esperan aludes de nieve reciente, tanto en forma de placa como de salida puntual, en lugares de fuerte pendiente y poco afectados por la acción del viento. Localmente podrían alcanzar tamaño 3. En terreno umbrío por encima de unos 2.300 m, la nieve se depositará sobre niveles débiles persistentes que podrían favorecer su desencadenamiento de aludes. Se recomienda no acceder a terreno alaboso el miércoles.

Distribución del manto nivoso

Hay nieve a partir de 1.500 m en umbrías y de 1.600 m en solanas. Los espesores a unos 2.200 m son ligeramente superiores a los normales en la Franja Norte de la Pallaresa y en la mitad sur de Arán, donde rondan los 180-240 cm. En la mitad norte de Arán son los normales por estas fechas con unos 130-150 cm de espesor total.

Tendencia para las próximas 48-72h

Situación de elevada inestabilidad aún para el jueves, aún con probables aludes de gran tamaño. Peligro ESTACIONARIO.

El próximo boletín será emitido el día 2026-04-01

5 MUY FUERTE	4 FUERTE	3 NOTABLE	2 LIMITADO	1 DÉBIL

EAWS EUROPEAN AVALANCHE WARNING SERVICES

ICGC Institut Cartogràfic i Geològic de Catalunya

Servei Meteorològic de Catalunya

Boletín de peligro de aludes Ribagorçana - Vall Fosca Del 31/03/2026 al 01/04/2026

(Válido fuera pistas de esquí y zonas no controladas)

NOTABLE (3) en la mitad norte por encima del nivel del bosque. LIMITADO (2) en el resto.

Situación primaria

Nieve venteada

Distribución

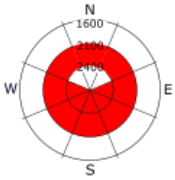

Tamaño

Origen

Tendencia

Situación secundaria

Capas débiles persistentes

Distribución

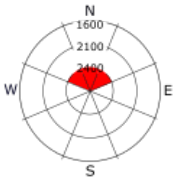

Tamaño

Origen

Tendencia

Estado del manto nivoso

La estabilidad del manto empeorará entre el martes y el miércoles. Se prevé fuerte viento del norte, acompañado de nevadas que podrán ser abundantes en el norte del sector. Se formarán placas de viento en diferentes sotaventos, principalmente los orientados a oeste, sur y este, por lo general duras pero que se podrán desprender al paso de una persona. En caso de caer, los aludes podrán alcanzar tamaño 2 o, de forma local, tamaño 3 (suficiente para enterrar a un grupo de personas) en sotaventos muy claros del norte del sector. Durante la segunda mitad de la jornada los aludes podrían caer de forma natural. En las umbrías más elevadas, además, quedarán enterrados algunos niveles débiles que podrían favorecer la caída accidental de aludes de placa.

Distribución del manto nivoso

Encontramos nieve a partir de 1.700 m en terreno umbrío y de 1.900 m en solanas. Los grosores alcanzan los 100-120 cm a unos 2.200 m. Estos valores se acercan a los normales para la época.

Tendencia para las próximas 48-72h

Pese a que las nevadas remitirán, el viento seguirá dando lugar a transporte. Las placas internamente irán asentando y los aludes naturales serán menos frecuentes. Peligro EN LEVE DESCENSO.

El próximo boletín será emitido el día 2026-04-01

5 MUY FUERTE	4 FUERTE	3 NOTABLE	2 LIMITADO	1 DÉBIL

EAWS EUROPEAN AVALANCHE WARNING SERVICES

ICGC Institut Cartogràfic i Geològic de Catalunya

Servei Meteorològic de Catalunya meteo.cat

Boletín de peligro de aludes Pallaresa
Del 31/03/2026 al 01/04/2026

(Válido fuera pistas de esquí y zonas no controladas)

NOTABLE (3) en la mitad norte por encima del nivel del bosque. LIMITADO (2) en el resto.

Situación primaria

Nieve venteada

Distribución

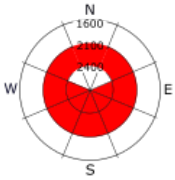

Tamaño

Origen

Tendencia

Situación secundaria

Capas débiles persistentes

Distribución

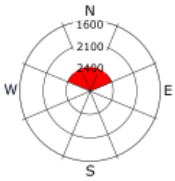

Tamaño

Origen

Tendencia

Estado del manto nivoso

La estabilidad del manto empeorará entre el martes y el miércoles. Se prevé fuerte viento del norte, acompañado de nevadas que podrán ser abundantes en el norte del sector. Se formarán placas de viento en diferentes sotaventos, principalmente los orientados a oeste, sur y este, por lo general duras pero que se podrán desprender al paso de una persona. En caso de caer, los aludes podrán alcanzar tamaño 2 o, de forma local, tamaño 3 (suficiente para enterrar a un grupo de personas) en sotaventos muy claros del norte del sector. Durante la segunda mitad de la jornada los aludes podrían caer de forma natural. En las umbrías más elevadas, además, quedarán enterrados algunos niveles débiles que podrían favorecer la caída accidental de aludes de placa.

Distribución del manto nivoso

Hay nieve por encima de 1.700 m en terreno umbrío y de 1.900 m en solanas. Los espesores alcanzan los 110-150 cm en cotas medias, puntualmente más, variable según los efectos del viento.

Tendencia para las próximas 48-72h

Pese a que las nevadas remitirán, el viento seguirá dando lugar a transporte. Las placas internamente irán asentando y los aludes naturales serán menos frecuentes. Peligro EN LEVE DESCENSO.

El próximo boletín será emitido el día 2026-04-01

5 MUY FUERTE	4 FUERTE	3 NOTABLE	2 LIMITADO	1 DÉBIL

EAWS EUROPEAN AVALANCHE WARNING SERVICES

ICGC Institut Cartogràfic i Geològic de Catalunya

meteo.cat Servei Meteorològic de Catalunya

Boletín de peligro de aludes Perafita-Puigpedrós Del 31/03/2026 al 01/04/2026

(Válido fuera pistas de esquí y zonas no controladas)

NOTABLE (3) por encima del nivel del bosque. LIMITADO (2) por debajo.

Situación primaria

Nieve venteada	Distribución	Tamaño	Origen	Tendencia

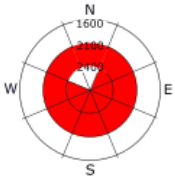

Estado del manto nivoso

A partir de la tarde del martes empeorará la estabilidad del manto por un episodio de nevadas y viento que se alargará hasta el jueves. Se acumularán unos 30 cm, muy afectados por el viento de norte y noroeste. En estas condiciones se formarán placas de viento a sotaventos orientados al sur, principalmente, que irán ganando grosor y siendo más inestables a lo largo del miércoles. Estas placas podrán caer al paso de una persona o incluso de forma natural, en especial durante la segunda mitad de la jornada. Se tratará de aludes de tamaño 2, suficiente para enterrar a una persona, aunque no se descartan mayores al final del día.

Distribución del manto nivoso

Hay nieve por encima de unos 1.900 m, discontinua hasta 2.200 m en solanas. Es esquiable a partir de unos 2.000 m en N. Los espesores, aunque irregulares, rondan los 70-100 cm en umbrías, a 2.300 m. Son grosores por encima de los habituales en esta época.

Tendencia para las próximas 48-72h

Las nevadas se convertirán en escasas y débiles, pero el viento seguirá dando lugar a transporte. Las placas internamente irán asentando y los aludes naturales serán menos frecuentes. Peligro EN LEVE DESCENSO.

El próximo boletín será emitido el día 2026-04-01

5 MUY FUERTE	4 FUERTE	3 NOTABLE	2 LIMITADO	1 DÉBIL

EAWS EUROPEAN AVALANCHE WARNING SERVICES

ICGC Institut Cartogràfic i Geològic de Catalunya

Servei Meteorològic de Catalunya

Boletín de peligro de aludes Vessant Nord Cadí-Moixeró Del 31/03/2026 al 01/04/2026

(Válido fuera pistas de esquí y zonas no controladas)

LIMITADO (2) a partir de media mañana.
DÉBIL (1) hasta entonces.

Situación primaria

Nieve venteada

Distribución

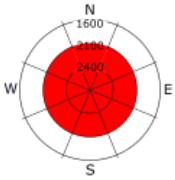

Tamaño

Origen

Tendencia

Estado del manto nivoso

A primera hora del miércoles predominará el manto endurecido, principalmente por la presencia de costras que estabilizarán el manto. Durante la jornada habrá nevadas y viento de componente norte que irán formando placas y el peligro aumentará a lo largo del día. Se tratará principalmente de placas duras pero lo suficientemente delgadas para ser desencadenadas al paso de una sola persona. Se encontrarán principalmente en sotaventos orientados a sur y este, pero también a zonas muy resguardadas del viento del resto de orientaciones como las canales más cerradas del Cadí. En caso de desprenderse se tratará de aludes de hasta tamaño 2, suficiente para enterrar a una persona. Habrá que evitar las zonas de acumulación donde encontramos la nieve placada y pendientes superiores a 30º.

Distribución del manto nivoso

En umbrías hay presencia discontinua de nieve por encima de unos 1.700 my es esquiable por encima de unos 1.900 m. Los grosores están alrededor de 160-180 cm a 2.200 m. Estos valores son muy excedentarios para la época del año.

Tendencia para las próximas 48-72h

El principal problema seguirá siendo la presencia de placas de viento que se podrán desprender de forma accidental. Peligro ESTACIONARIO.

El próximo boletín será emitido el día 2026-04-01

5 MUY FUERTE	4 FUERTE	3 NOTABLE	2 LIMITADO	1 DÉBIL

EAWS EUROPEAN AVALANCHE WARNING SERVICES

ICGC Institut Cartogràfic i Geològic de Catalunya

Servei Meteorològic de Catalunya meteo.cat

Boletín de peligro de aludes Prepirineu
Del 31/03/2026 al 01/04/2026

(Válido fuera pistas de esquí y zonas no controladas)

LIMITADO (2) a partir de media mañana.
DÉBIL (1) hasta entonces.

Situación primaria

Nieve venteada

Distribución

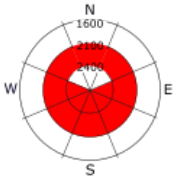

Tamaño

Origen

Tendencia

Estado del manto nivoso

A primera hora del miércoles predominará el manto endurecido, principalmente por la presencia de costras que estabilizarán el manto. Durante la jornada habrá nevadas y viento de componente norte que irán formando placas y el peligro aumentará a lo largo del día. Se tratará principalmente de placas duras pero lo suficientemente delgadas para ser desencadenadas al paso de una sola persona. Se encontrarán principalmente en sotaventos orientados a sur y este, pero también a zonas muy resguardadas del viento del resto de orientaciones. En caso de desprenderse se tratará de aludes de hasta tamaño 2, suficiente para enterrar a una persona. Habrá que evitar las zonas de acumulación donde encontramos la nieve placada y pendientes superiores a 30º.

Distribución del manto nivoso

En umbrías hay nieve por encima de unos 1.700 m. En solanas la nieve está presente por encima de unos 1.900 m, discontinua. Los espesores, aunque irregulares, rondan los 90-120 cm a 2.300 m.

Tendencia para las próximas 48-72h

El principal problema seguirá siendo la presencia de placas de viento que se podrán desprender de forma accidental. Peligro ESTACIONARIO.

El próximo boletín será emitido el día 2026-04-01

5 MUY FUERTE	4 FUERTE	3 NOTABLE	2 LIMITADO	1 DÉBIL

EAWS EUROPEAN AVALANCHE WARNING SERVICES

ICGC Institut Cartogràfic i Geològic de Catalunya

Servei Meteorològic de Catalunya meteo.cat

Boletín de peligro de aludes Ter-Freser Del 31/03/2026 al 01/04/2026

(Válido fuera pistas de esquí y zonas no controladas)

LIMITADO (2). NOTABLE (3) al final del día por encima de 2.200 m.

Situación primaria

Nieve venteada

Distribución

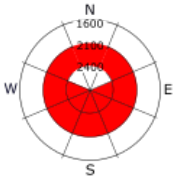

Tamaño

Origen

Tendencia

Estado del manto nivoso

El miércoles por la mañana encontraremos un manto endurecido por rehielo, con algún centímetro de nieve placada, redistribuida por el viento de las últimas jornadas. A lo largo del día la estabilidad del manto irá empeorando por un episodio de nevadas y viento que se alargará hasta el jueves. Se acumularán unos 20 cm, muy afectados por el viento de norte y noroeste. En estas condiciones se formarán placas de viento a sotaventos orientados al sur, principalmente, que irán ganando grosor y siendo más inestables a lo largo del miércoles. Estas placas podrán caer al paso de una persona en su conjunto, si bien al final de la jornada se podrán desprender de forma natural. Se tratará de aludes de tamaño 2, suficiente para enterrar a una persona, aunque no se descartan mayores al final del día. Habrá que evitar las zonas de acumulación donde encontramos la nieve placada y pendientes superiores a 30º.

Distribución del manto nivoso

Hay nieve en el suelo por encima de unos 1.700 m. El manto es esquiable a umbrías a partir de unos 1.800 m. Los grosores son muy excedentarios para la época del año y en lugares no afectados por el viento oscilan entre 60-80 cm a unos 2.000 m, y más de 150 cm por encima de 2.400 m, muy variable por los efectos del viento.

Tendencia para las próximas 48-72h

Las nevadas se convertirán en escasas y débiles, pero el viento seguirá dando lugar a transporte. Las placas internamente irán asentando y los aludes naturales serán menos frecuentes. Peligro EN LEVE DESCENSO.

El próximo boletín será emitido el día 2026-04-01

5 MUY FUERTE	4 FUERTE	3 NOTABLE	2 LIMITADO	1 DÉBIL

EAWS EUROPEAN AVALANCHE WARNING SERVICES