BUTLLETÍ DEL PERILL D'ALLAUS DEL PRINCIPAT D'ANDORRA

Elaborado el 31/03/2026 16:00
Proxima actualización 01/04/2026 a las 16h

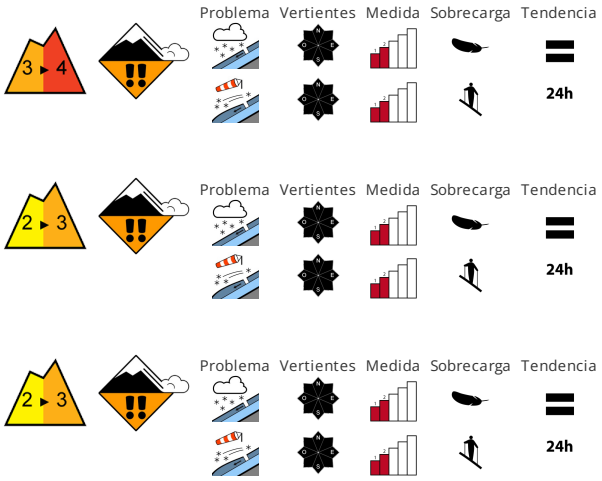

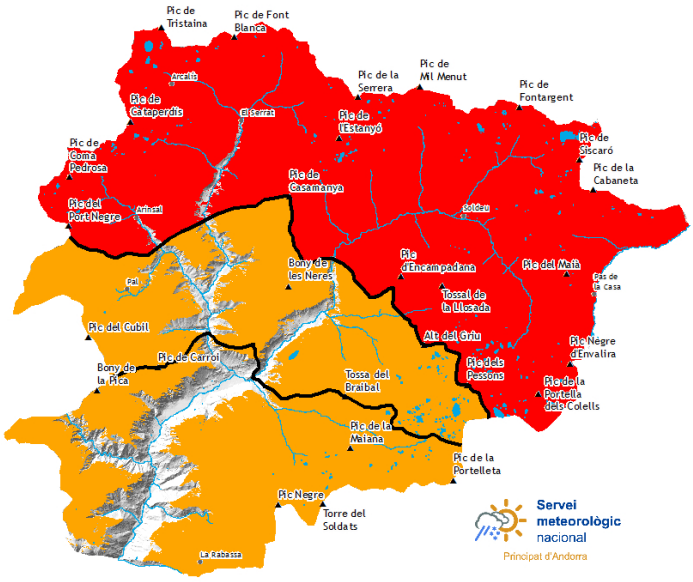

CALIDAD DE LA NIEVE

Las zonas de salida se verán nuevamente cargadas a causa de la nevada y el viento. El viento con rachas fuertes transportará intensamente la nieve reciente y la nieve antigua. La nieve reciente abundante y las placas de viento pueden desencadenarse de manera natural en todas las orientaciones. Estos son como mínimo de tamaño mediano. Los lugares peligrosos se encuentran en todas las orientaciones cerca del límite del bosque y en la entrada de canales y cubetas. Las condiciones para las excursiones son desfavorables. Los lugares peligrosos son bastante frecuentes y resultan difíciles de reconocer con poca visibilidad. Por ahora, las actividades de deportes de invierno fuera de las pistas controladas están desaconsejadas.

ESTABILIDAD DEL MANTO NIVOSO

Hasta el jueves caerá mucha nieve sobre todo en los norte. El viento soplará, cerca de los cordales, fuerte. El manto de nieve permanece extremadamente variable en pocos metros en general. Cerca de los cordales los espesores de nieve varían mucho por la influencia del viento.

ESPESORES DEL MANTO NIVOSO FUERA DE PISTA

Zona norte		Espesor nieve		
Manto Nival		1500m	2000m	2500m
N	1300 m	10 cm	150 cm	200 cm
S	1500 m	5 cm	100 cm	150 cm

zona centro		Espesor nieve		
Manto Nival		1500m	2000m	2500m
N	1300 m	10 cm	150 cm	200 cm
S	1500 m	5 cm	100 cm	150 cm

Zona sur		Espesor nieve		
Manto Nival		1500m	2000m	2500m
N	1300 m	10 cm	120 cm	150 cm
S	1500 m	5 cm	60 cm	100 cm

Govern d'Andorra

EAWS EUROPEAN AVALANCHE WARNING SERVICES

Aquest butlletí ha estat elaborat seguint les normes i recomanacions de l'**European Avalanche Warning Services**, del qual el **Servei meteorològic Nacional** n'és membre

BUTLLETÍ DEL PERILL D'ALLAUS DEL PRINCIPAT D'ANDORRA

Servei meteorològic nacional
Principat d'Andorra

Información detallada por espacios naturales protegidos

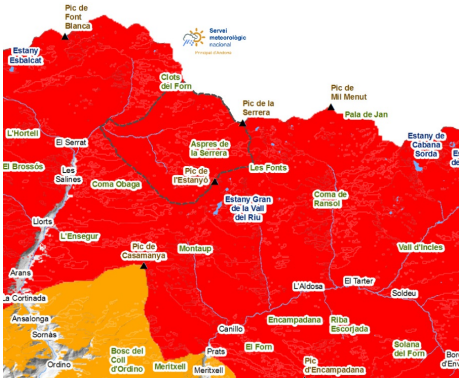

SORTENY

El viento ha moldeado la nieve reciente y lo seguirá haciendo durante las próximas horas. Debido a las nevadas sucesivas que sobre todo afectarán al norte de Andorra y al viento que todavía soplará fuerte en altura, se aconseja no salir del límite del bosque. Además, las condiciones de viento y nieve generarán ventisca y mala visibilidad.

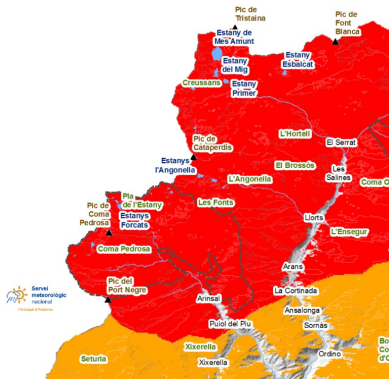

COMAPEDROSA

Se prevé que el viento sea aún intenso en altura durante los próximos días y se sigan formando placas de viento, ocultas bajo la nieve reciente del miércoles y difícilmente identificables. La situación resulta desfavorable para las excursiones.

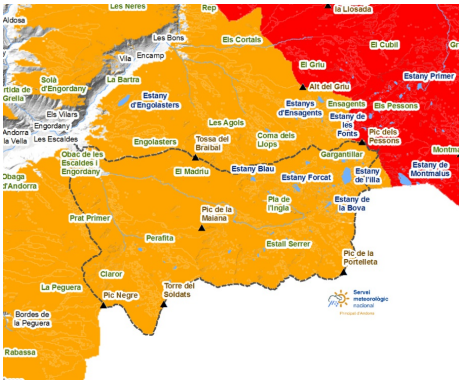

MADRIU-PERAFITA-CLAROR

La nieve reciente retrocede rápidamente de las cotas bajas del valle, pero en cotas altas el ambiente es aún invernal. El viento y la mala visibilidad deben hacernos renunciar a llegar a los collados más altos. Deberemos circular con mucha precaución, manteniendo la distancia de seguridad.

Govern d'Andorra

EAWS
EUROPEAN AVALANCHE WARNING SERVICES

Aquest butlletí ha estat elaborat seguint les normes i recomanacions de l'**European Avalanche Warning Services**, del qual el **Servei meteorològic Nacional** n'és membre

BUTLLETÍ DEL PERILL D'ALLAUS DEL PRINCIPAT D'ANDORRA

Servei meteorològic nacional
Principat d'Andorra

Espesores de nieve nueva de los últimos días (de las ultimas 24h mesurado a las 06:00h UTC)

	27/03/2026	28/03/2026	29/03/2026	30/03/2026
FEDA (Central)	0 cm	0 cm	0 cm	0 cm
Engolasters - FEDA	0 cm	7 cm	0 cm	0 cm
Ransol - FEDA	0 cm	18 cm	0 cm	3 cm
Fontverd	0 cm	17 cm	0 cm	0 cm
Setúria	0 cm	21 cm	0 cm	2 cm
Coll Ordino	0 cm	25 cm	0 cm	0 cm
Bony de les Neres	0 cm	20 cm	0 cm	0 cm
Grau Roig - FEDA	0 cm	16 cm	0 cm	1 cm
Caborreu	0 cm	23 cm	0 cm	5 cm
Sorteny	0 cm	16 cm	15 cm	7 cm
Coll Pa	6 cm	21 cm	0 cm	3 cm
Perafita	0 cm	0 cm	0 cm	0 cm
Tossa Espiolets	0 cm	34 cm	0 cm	4 cm
La Solana	1 cm	30 cm	9 cm	6 cm
Vall del Riu FEDA	0 cm	10 cm	0 cm	1 cm
Envalira Antenes	0 cm	27 cm	11 cm	2 cm
Les Fonts d'Arinsal	0 cm	4 cm	0 cm	7 cm