BUTLLETÍ DEL PERILL D'ALLAUS DEL PRINCIPAT D'ANDORRA

Préparé le 31/03/2026 16:00
Prochaine mise à jour le 01/04/2026 à 16h

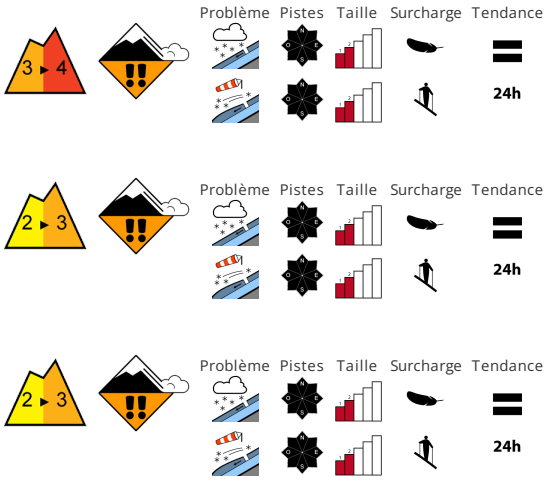

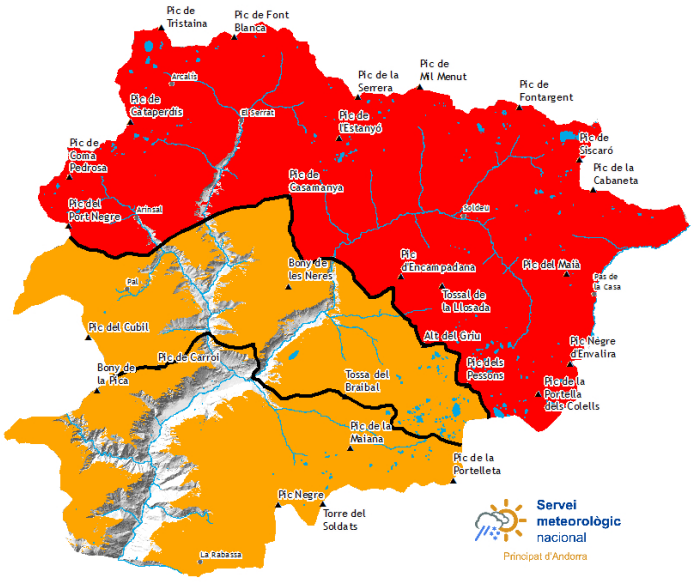

STABILITÉ DU MANTEAU NEIGEUX

Les zones de départ seront à nouveau rechargées avec les chutes de neige et le vent. Le vent parfois fort transporte la neige fraîche et ancienne de manière intensive.. La neige fraîche très abondante et les accumulations de neige soufflée peuvent glisser spontanément à toutes les expositions. Explication: celles-ci ne peut signifier que celles-ci avalanches sont généralement de taille moyenne. Les endroits dangereux se situent à toutes les expositions dans la zone de la limite de la forêt ainsi qu'aux transitions vers les combes et couloirs. Les conditions de randonnées sont défavorables. Les endroits dangereux sont assez fréquents et à peine identifiables par mauvaise visibilité.. Il est déconseillé d'effectuer des sports d'hiver en dehors des pistes sécurisées.

QUALITÈ DE LA NEIGE

Jusqu'à jeudi il tombera beaucoup de neige surtout au nord. Le vent souffle à proximité des crêtes fortement. De manière généralisée le manteau neigeux reste très variable à petite échelle.. À proximité des crêtes on trouve suivant l'influence du vent des hauteurs de neiges très différentes.

EPAISSEUR DE NEIGE HORS PISTE

Zone nord		Epaisseur de neige		
Nival manteau		1500m	2000m	2500m
N	1300 m	10 cm	150 cm	200 cm
S	1500 m	5 cm	100 cm	150 cm

Zone centre		Epaisseur de neige		
Nival manteau		1500m	2000m	2500m
N	1300 m	10 cm	150 cm	200 cm
S	1500 m	5 cm	100 cm	150 cm

Zone sud		Epaisseur de neige		
Nival manteau		1500m	2000m	2500m
N	1300 m	10 cm	120 cm	150 cm
S	1500 m	5 cm	60 cm	100 cm

Govern d'Andorra

EAWS EUROPEAN AVALANCHE WARNING SERVICES

Aquest butlletí ha estat elaborat seguint les normes i recomanacions de l'**European Avalanche Warning Services**, del qual el **Servei meteorològic Nacional** n'és membre

BUTLLETÍ DEL PERILL D'ALLAUS DEL PRINCIPAT D'ANDORRA

Servei meteorològic nacional
Principat d'Andorra

Des informations détaillées par espace naturel protégé

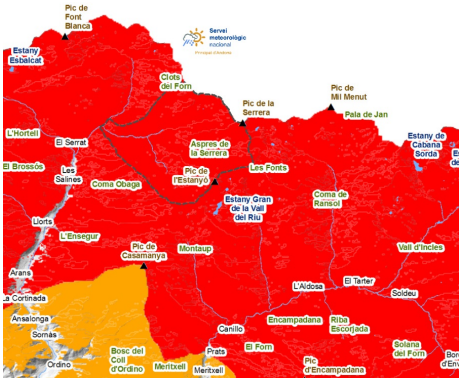

SORTENY

Le vent a façonné la neige récente et continuera de le faire au cours des prochaines heures. En raison des chutes de neige successives qui affecteront principalement le nord d'Andorre et du vent qui soufflera encore fort en altitude, il est conseillé de ne pas sortir de la limite forestière. De plus, les conditions venteuses et neigeuses créeront de la turbidité et une mauvaise visibilité. , , , , ,

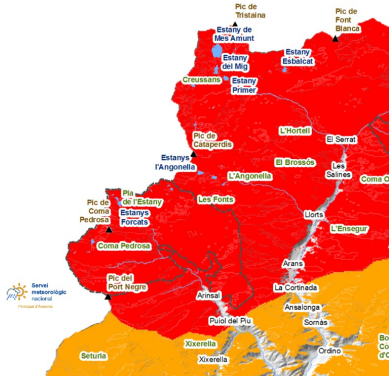

COMAPEDROSA

Les vents devraient rester forts en altitude au cours des prochains jours et des zones de vent continueront à se former, cachées sous la neige récente de mercredi et difficiles à identifier. La situation est défavorable aux excursions. , , ,

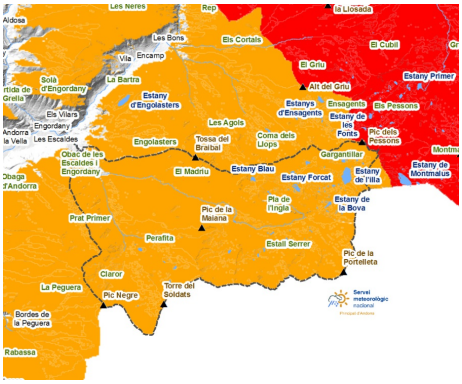

MADRIU-PERAFITA-CLAROR

La neige récente recule rapidement dans les basses altitudes de la vallée, mais à des altitudes plus élevées, l'atmosphère est encore hivernale. Le vent et la mauvaise visibilité nous feront renoncer à atteindre les plus hautes collines. Nous devrons conduire très prudemment, en gardant une distance de sécurité. , , , , ,

Govern d'Andorra

EAWS
EUROPEAN AVALANCHE WARNING SERVICES

Aquest butlletí ha estat elaborat seguint les normes i recomanacions de l'**European Avalanche Warning Services**, del qual el **Servei meteorològic Nacional** n'és membre

BUTLLETÍ DEL PERILL D'ALLAUS DEL PRINCIPAT D'ANDORRA

Servei meteorològic nacional
Principat d'Andorra

Couche de neige fraiche des derniers jours (De 24 h mesurée à 06:00 h UTC)

	27/03/2026	28/03/2026	29/03/2026	30/03/2026
FEDA (Central)	0 cm	0 cm	0 cm	0 cm
Engolasters - FEDA	0 cm	7 cm	0 cm	0 cm
Ransol - FEDA	0 cm	18 cm	0 cm	3 cm
Fontverd	0 cm	17 cm	0 cm	0 cm
Setúria	0 cm	21 cm	0 cm	2 cm
Coll Ordino	0 cm	25 cm	0 cm	0 cm
Bony de les Neres	0 cm	20 cm	0 cm	0 cm
Grau Roig - FEDA	0 cm	16 cm	0 cm	1 cm
Caborreu	0 cm	23 cm	0 cm	5 cm
Sorteny	0 cm	16 cm	15 cm	7 cm
Coll Pa	6 cm	21 cm	0 cm	3 cm
Perafita	0 cm	0 cm	0 cm	0 cm
Tossa Espiolets	0 cm	34 cm	0 cm	4 cm
La Solana	1 cm	30 cm	9 cm	6 cm
Vall del Riu FEDA	0 cm	10 cm	0 cm	1 cm
Envalira Antenes	0 cm	27 cm	11 cm	2 cm
Les Fonts d'Arinsal	0 cm	4 cm	0 cm	7 cm