MINISTERO DELLA DIFESA

meteomont
Servizio Nazionale di previsione neve e valanghe

EAWS EUROPEAN AVALANCHE WARNING SERVICES

CARABINIERI

AERONAUTICA MILITARE SERVIZIO METEOROLOGICO

# TERMINILLO MONTI REATINI E LAGA OVEST

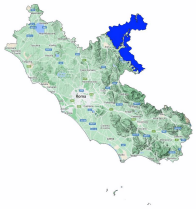

Bollettino Valanghe N. 331/2026 del 30/03/2026 ore 14.00
Validità 48 ore prossima emissione 31/03/2026

**A cura del Servizio METEOMONT dell'ARMA dei CARABINIERI**
**In collaborazione con Servizio Meteorologico dell'Aeronautica militare**

## SITUAZIONE alle 14:00 del 30/03/2026

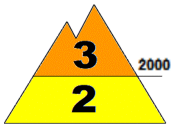


**SITUAZIONE TIPO: neve a debole coesione e vento.**

**SITUAZIONE TIPO: situazione primaverile.**

| Quota neve (mslm) | Nord | Sud |
|---|---|---|
| | 1400 | 1600 |

| Altezza Neve (cm) | Neve al suolo | Neve Fresca | Quota (mslm) |
|---|---|---|---|
| | 037 | 000 | 1762 |
| | 012 | 000 | 1350 |

**VALANGHE OSSERVATE: Nessuna valanga.**

## PREVISIONI 31/03/2026

# GRADO DI PERICOLO: MARCATO 3

## SITUAZIONE TIPO: neve a debole coesione e vento.

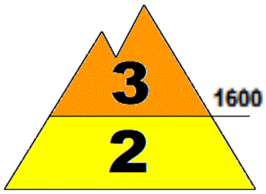


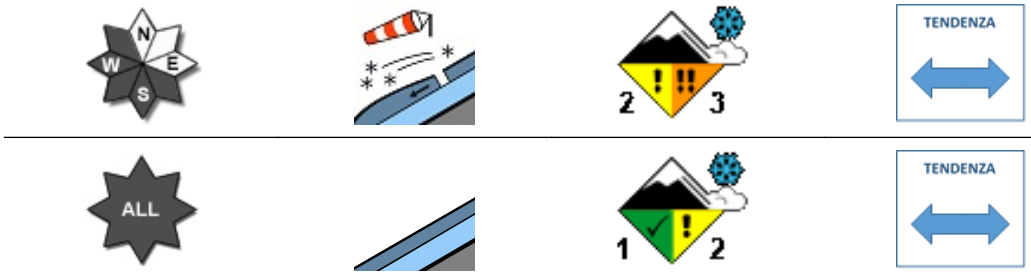


## SITUAZIONE TIPO: nessuna situazione tipo evidente.

**MANTO NEVOSO: La stabilità del manto nevoso è scarsa su alcuni punti (aree) per versanti da sud est a nord ovest al di sopra di 1600 mslm, possibili valanghe di dimensioni grandi.**
**La stabilità del manto nevoso è discreta su alcuni punti (aree) per tutte le esposizioni al di sotto di 1600 mslm, possibili valanghe di dimensioni medie.**

## AVVERTENZE

In considerazione delle avverse condizioni meteorologiche previste , le attività al di fuori delle piste battute e segnalate sono sconsigliate.

## SCALA EUROPEA DEL GRADO DI PERICOLO VALANGHE

## LEGENDA PROBLEMA

**Bollettino realizzato su scala sinottica-regionale (standard EAWS). La sua valutazione non può escludere in alcun modo la necessità di una seria e capace valutazione locale del pericolo (singolo pendio) che può essere anche sensibilmente diverso. Le previsioni meteorologiche sono relative all'orario UTC (per l'Italia +1 in inverno e +2 in estate).**

**Bollettino sottoposto a processi di: Acquisizione e controllo del C-Sifa e della rete di Osservatori e Esperti - Validazione del Previsore di turno - Certificazione della Sezione Meteomont.**

# TERMINILLO MONTI REATINI E LAGA OVEST

## PREVISIONE METEO

| Quota | | 31/03/2026 h6:00 | 31/03/2026 h12:00 | 31/03/2026 h18:00 |
|---|---|---|---|---|
| 1000 | Venti | 10 Nodi da N-Est | 10 Nodi da N-Est | 11 Nodi da N-Est |
| | Temperature | -03 °C | -02 °C | -03 °C |
| | Temp.percepita | -9 °C | -8 °C | -9 °C |
| 2000 | Venti | 24 Nodi da N-Est | 22 Nodi da N-Est | 26 Nodi da N-Est |
| | Temperature | -06 °C | -06 °C | -06 °C |
| | Temp.percepita | -16 °C | -15 °C | -16 °C |
| 3000 | Venti | 19 Nodi da Est | 19 Nodi da Est | 23 Nodi da N-Est |
| | Temperature | -12 °C | -10 °C | -12 °C |
| | Temp.percepita | -23 °C | -20 °C | -24 °C |
| Zero termico | | 1000-1200 m. | 1200-1400 m. | 1000-1200 m. |
| Fenomeno | | | | |
| Stato del cielo | | | | |

## LEGENDA FENOMENI

Assenza Fenomeni — Nebbia — Foschia — Pioggia debole — Pioggia moderata — Pioggia forte — Temporali

Nevicata debole — Nevicata moderata — Nevicata forte

## STATO DEL CIELO

Sereno — Poco nuvoloso — Nuvoloso — Molto nuvoloso — Coperto

## Parametri meteonivometrici registrati presso i campi di rilevamento il 30/03/2026.

| Località | Comune | Quota (m.s.l.m.) | Altezza neve (cm) | Neve caduta nelle 24 ore (cm) | Temp. Min (°C) | Temp. Max (°C) | Condizioni del tempo |
|---|---|---|---|---|---|---|---|
| PESCHIERE | Amatrice (RI) | 1270 | 9 | 0 | -1 | +9 | Assenza di precipitazioni |
| M. CAIDURO | Cittareale (RI) | 1300 | 6 | 0 | -2 | +10 | Assenza di precipitazioni |
| VALLONINA | Leonessa (RI) | 1350 | 12 | 0 | -2 | +12 | Assenza di precipitazioni |
| GIRO DELL'ANELLO - VILLA CHIGI * | Rieti (RI) | 1762 | 37 | 0 | -2 | +1 | Assenza di precipitazioni |

(*) Rilievi fuori campo

**L'INFORMAZIONE E' PREVENZIONE - LEGGI L'ATTUALE GRADO DI PERICOLO VALANGHE!**

**IL CAPO DEL CENTRO NAZIONALE METEOMONT**
**(Ten. Col. RFI Emanuela Gini)**
**FIRMA AUTOGRAFA OMESSA AI SENSI**
**DELL'ART.3 DEL D.LGS N.39/1993**

Bollettino realizzato su scala sinottica-regionale (standard EAWS). La sua valutazione non può escludere in alcun modo la necessità di una seria e capace valutazione locale del pericolo (singolo pendio) che può essere anche sensibilmente diverso. Le previsioni meteorologiche sono relative all'orario UTC (per l'Italia +1 in inverno e +2 in estate).