MINISTERO DELLA DIFESA

meteomont Servizio Nazionale di previsione neve e valanghe

EAWS EUROPEAN AVALANCHE WARNING SERVICES

CARABINIERI

APPENNINO CAMPANO

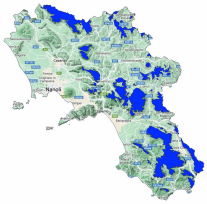

Bollettino Valanghe N. 279/2026 del 31/03/2026 ore 14.00
Validità 48 ore prossima emissione 01/04/2026

A cura del Servizio METEOMONT dell'ARMA dei CARABINIERI
In collaborazione con Servizio Meteorologico dell'Aeronautica militare

SITUAZIONE alle 14:00 del 31/03/2026

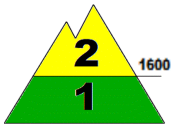

SITUAZIONE TIPO: neve a debole coesione e vento.



SITUAZIONE TIPO: pioggia su neve.

	Nord	Sud
Quota neve (mslm)	*900 - 1000*	*900 - 1000*

	Neve al suolo	Neve Fresca	Quota (mslm)
Altezza Neve (cm)	*20 - 35*	*12 - 22*	*1350*
	010	*010*	*1100*

VALANGHE OSSERVATE: Nessuna valanga.

PREVISIONI 01/04/2026

GRADO DI PERICOLO: MODERATO 2

SITUAZIONE TIPO: neve a debole coesione e vento.

SITUAZIONE TIPO: pioggia su neve.

MANTO NEVOSO: La stabilità del manto nevoso è discreta su alcuni punti (aree) per versanti settentrionali al di sopra di 1600 mslm, possibili valanghe di dimensioni medie.
La stabilità del manto nevoso è discreta su alcuni punti (aree) per tutte le esposizioni al di sotto di 1600 mslm, possibili valanghe di dimensioni piccole.

AVVERTENZE

Viste le condizioni del manto nevoso, le attività al di fuori delle piste battute e segnalate richiedono buone capacità di valutazione del pericolo locale.

SCALA EUROPEA DEL GRADO DI PERICOLO VALANGHE

LEGENDA PROBLEMA

Bollettino realizzato su scala sinottica-regionale (standard EAWS). La sua valutazione non può escludere in alcun modo la necessità di una seria e capace valutazione locale del pericolo (singolo pendio) che può essere anche sensibilmente diverso. Le previsioni meteorologiche sono relative all'orario UTC (per l'Italia +1 in inverno e +2 in estate).

MINISTERO DELLA DIFESA

meteomont
Servizio Nazionale di previsione neve e valanghe

EAWS EUROPEAN AVALANCHE WARNING SERVICES

CARABINIERI

APPENNINO CAMPANO

PREVISIONE METEO

Quota		01/04/2026 h6:00	01/04/2026 h12:00	01/04/2026 h18:00
1000	Venti	13 Nodi da N-Est	08 Nodi da N-Est	11 Nodi da Est
	Temperature	+00 °C	+03 °C	+03 °C
	Temp.percepita	-6 °C	-1 °C	-1 °C
2000	Venti	28 Nodi da N-Est	17 Nodi da Est	20 Nodi da Est
	Temperature	-03 °C	-01 °C	-01 °C
	Temp.percepita	-12 °C	-8 °C	-8 °C
3000	Venti	23 Nodi da Est	17 Nodi da Est	15 Nodi da Est
	Temperature	-05 °C	-06 °C	-06 °C
	Temp.percepita	-14 °C	-14 °C	-14 °C
Zero termico		1100-1300 m.	1700-1900 m.	1700-1900 m.
Fenomeno				
Stato del cielo				

LEGENDA FENOMENI

Assenza Fenomeni · Nebbia · Foschia · Pioggia debole · Pioggia moderata · Pioggia forte · Temporali

Nevicata debole · Nevicata moderata · Nevicata forte

STATO DEL CIELO

Sereno · Poco nuvoloso · Nuvoloso · Molto nuvoloso · Coperto

Parametri meteonivometrici registrati presso i campi di rilevamento il 31/03/2026.

Località	Comune	Quota (m.s.l.m.)	Altezza neve (cm)	Neve caduta nelle 24 ore (cm)	Temp. Min (°C)	Temp. Max (°C)	Condizioni del tempo
DIFESA SAN MATTEO	San Marco in Lamis (FG)	880	0	0	+5	+10	Pioggia debole intermittente
LACENO	Bagnoli Irpino (AV)	1460	19	12	-4	+4	Nevicata debole continua
LAGO PESCARA	Biccari (FG)	920	0	0	+2	+8	Pioggia debole continua
SELLA CESSUTA	Montesano sulla Marcellana (SA)	1042	0	0	+1	+13	Pioggia debole continua
BOCCA DELLA SELVA	Piedimonte Matese (CE)	1350	35	22	-2	+8	Nevicata moderata

(*) Rilievi fuori campo

L'INFORMAZIONE E' PREVENZIONE - LEGGI L'ATTUALE GRADO DI PERICOLO VALANGHE!

IL CAPO DEL CENTRO NAZIONALE METEOMONT
(Ten. Col. RFI Emanuela Gini)
FIRMA AUTOGRAFA OMESSA AI SENSI
DELL'ART.3 DEL D.LGS N.39/1993