Bulletin d'estimation du risque d'avalanche

(valable en dehors des pistes balisées et ouvertes)

MASSIF : Cinto Rotondo

Rédigé le mardi 31 mars 2026 à 15h

Estimation des risques pour le : MERCREDI 01 AVRIL

INSTABILITÉS EN ALTITUDE

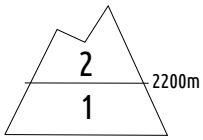

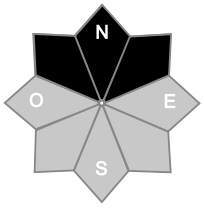

Au-dessus de 2200m indice de risque limité, plus bas indice faible.

Départs spontanés : Peu probables.

Déclenchements provoqués : rares plaques à vent présentes en altitude au-dessus de 2200 m

Indices de risque : 5 très fort - 4 fort - 3 marqué - 2 limité - 1 faible -- En noir : les pentes les plus dangereuses

Stabilité du manteau neigeux

Situation avalancheuse typique : neige ventée

Déclenchements provoqués : de fines plaques à vent sont en place dans les pentes raides, généralement en neige dure bien identifiable, majoritairement au-dessus de 2200 m. Ces plaques surtout présentes dans une large orientation nord peuvent engendrer de petites avalanches rarement moyennes (taille 1 à 2). Départs possibles au passage d'un seul skieur plutôt à distance des crêtes et à proximité des ruptures de pentes.
Départs spontanés : les départs spontanés attendus sont peu probables avec des températures très froides et un rayonnement limité par la couche nuageuse l'après-midi.
Autres : nombreuses surfaces dures et glacées, pouvant être recouvertes de quelques centimètres de neige récente. Présence de corniches.

Qualité de la neige

Qualification de l'enneigement : L'enneigement est excellent pour la saison et même excédentaire au-dessus de 1700 m. Sur la Maniccia, à 2400 m d'altitude dans le massif du Rotondo, on relève pratiquement 3m30 de hauteur de neige totale.
Limite d'enneigement skiable : 1500 m.
État de la neige : Le net refroidissement a permis une consolidation par regel des couches de neige humide. Des croûtes épaisses se sont formées et des surfaces dures et glacées se sont généralisées. Neige regelée mercredi matin restant dure et éventuellement verglacée dans un très large secteur sud, durcie par le vent en versants ombragés d'altitude. Le manque de soleil limite la transformation de cette neige aux altitudes les plus basses avec un décaillage très superficiel.

Aperçu météo pour le mercredi 01 avril

	nuit	matin	après-midi	soir
Pluie-Neige				900 m
Iso 0 °C	1 100 m	1 000 m	1 200 m	1 200 m
Vent 1500 m	95 km/h	100 km/h	50 km/h	55 km/h
Vent 3000 m	80 km/h	70 km/h	45 km/h	60 km/h

Épaisseur de neige hors-piste

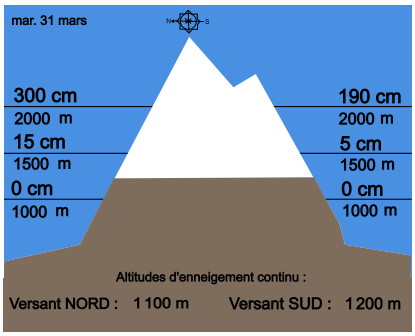

Précipitations à 1800 m

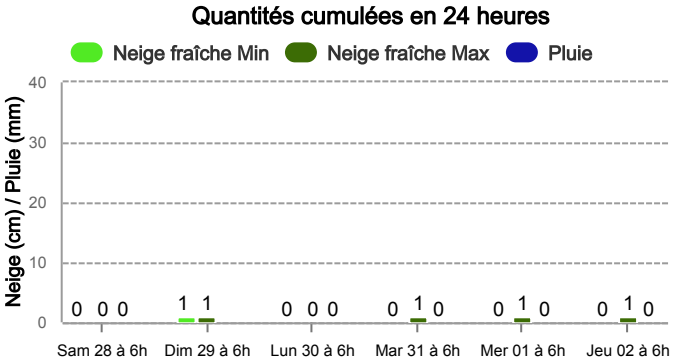

Tendance du jeudi 02 avril

Indice de risque limité

Pas dévolution notable en termes de risque.

Pour consulter la vigilance en cours, veuillez vous rendre sur le site https://vigilance.meteofrance.fr/fr

Météo-France - 73 avenue de Paris, 94165 Saint-Mandé cedex - Contact : contact@meteo.fr

Rédigé par Météo-France avec la contribution des observateurs du réseau nivo-météorologiques. Partenariat : ANMSM (Maires de Stations de Montagne), DSF (Domaines Skiables de France), ADSP (Directeurs de Pistes et de la Sécurité des Stations de Sports d'Hiver) et autres acteurs de la montagne.

Bulletin neige & avalanches par téléphone au 0 892 68 10 20 Service 0,35 € / min + prix appel

RÉPUBLIQUE FRANÇAISE
Liberté Égalité Fraternité

METEO FRANCE
À VOS CÔTÉS, DANS UN CLIMAT QUI CHANGE

Bulletin d'estimation du risque d'avalanche

(valable en dehors des pistes balisées et ouvertes)

MASSIF : Cinto Rotondo

Rédigé le mardi 31 mars 2026 à 15h

Conditions nivo-météo des 7 derniers jours

	mer. 25/03				jeu. 26/03				ven. 27/03				sam. 28/03				dim. 29/03				lun. 30/03				mar. 31/03			
	03h	09h	15h	21h	03h	09h	15h	21h	03h	09h	15h	21h	03h	09h	15h	21h	03h	09h	15h	21h	03h	09h	15h	21h	03h	09h	15h	21h
Météo																												
Vent (km/h)	20	60	80	120	110	85	90	90	50	40	35	50	30	15	20	10	15	35	45	30	25	15	30	40	70	70	70	95
à 3000m																												
Vent (km/h)	10	30	50	80	85	60	60	60	35	10	25	30	20	15	20	10	10	35	45	30	25	15	30	30	40	60	30	70
à 1500m																												

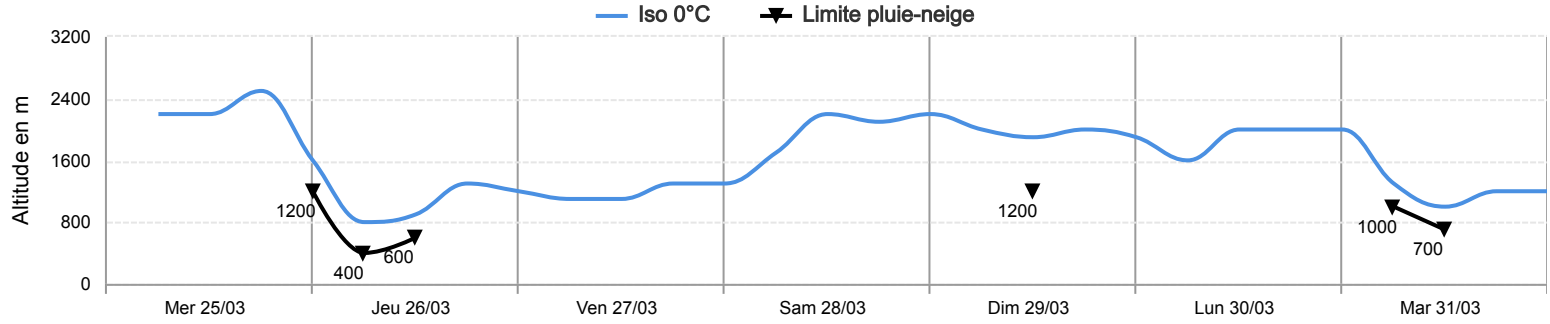

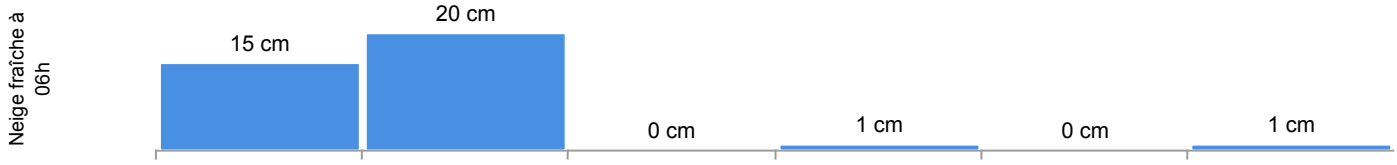

Risque d'avalanche	mer. 25/03	jeu. 26/03	ven. 27/03	sam. 28/03	dim. 29/03	lun. 30/03	mar. 31/03
	2	2	2	2	2	2	2

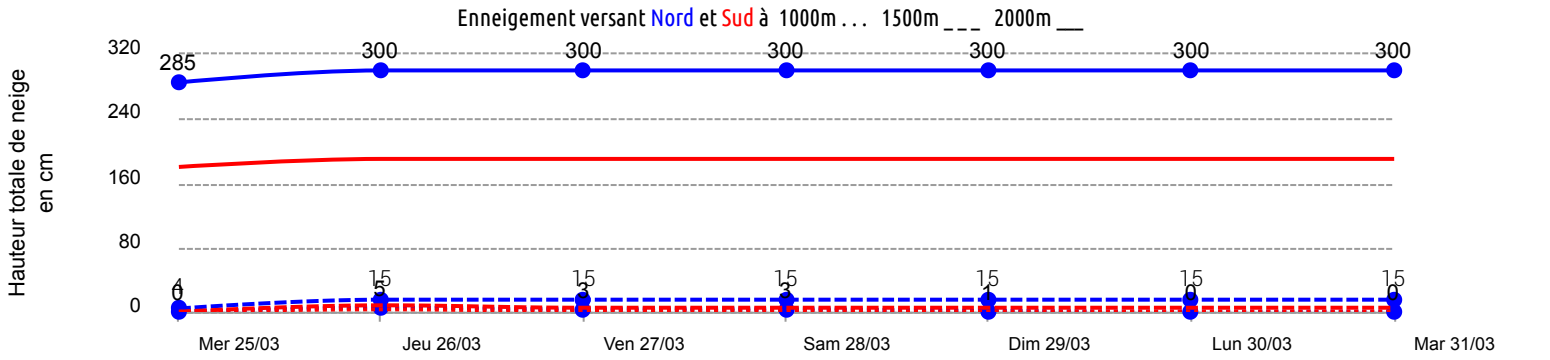

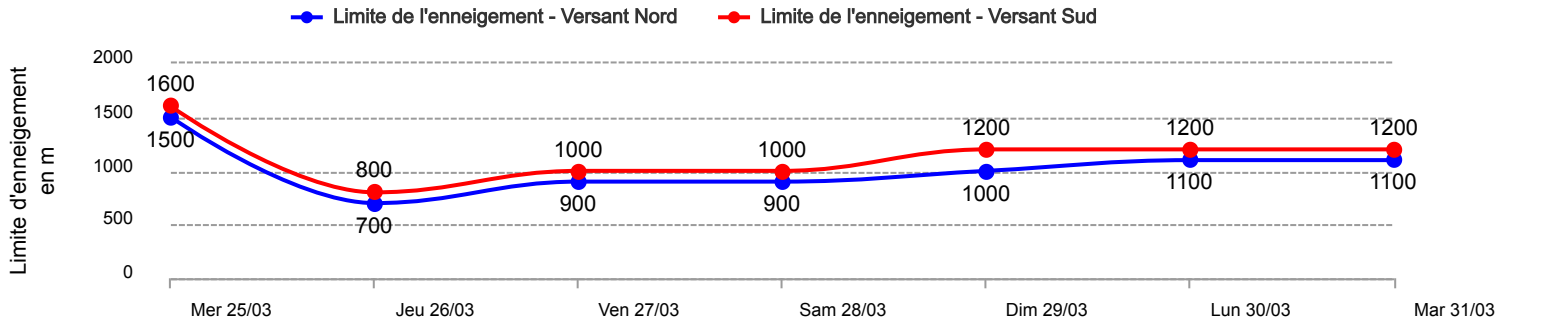

Pour consulter la vigilance en cours, veuillez vous rendre sur le site https://vigilance.meteofrance.fr/fr

Météo-France - 73 avenue de Paris, 94165 Saint-Mandé cedex - Contact : contact@meteo.fr

Bulletin neige & avalanches par téléphone au

0 892 68 10 20 Service 0,35 € / min + prix appel

Rédigé par Météo-France avec la contribution des observateurs du réseau nivo-météorologiques. Partenariat : ANMSM (Maires de Stations de Montagne), DSF (Domaines Skiables de France), ADSP (Directeurs de Pistes et de la Sécurité des Stations de Sports d'Hiver) et autres acteurs de la montagne.