Bulletin d'estimation du risque d'avalanche
(valable en dehors des pistes balisées et ouvertes)

MASSIF : Aravis

Rédigé le mardi 31 mars 2026 à 16h

Estimation des risques pour le : MERCREDI 01 AVRIL

NOUVELLES PLAQUES À VENT SOUS LA BISE DE NNE.

3

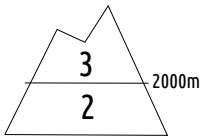

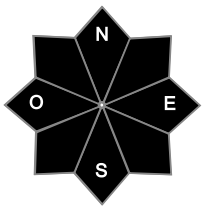

Au-dessus de 2000m indice de risque marqué, plus bas indice limité.

Départs spontanés : quelques accumulations dans la neige récente peuvent céder

Déclenchements provoqués : nouvelles plaques à vent dans la neige récente

Indices de risque : 5 très fort - 4 fort - 3 marqué - 2 limité - 1 faible -- En noir : les pentes les plus dangereuses

Stabilité du manteau neigeux

Situation avalancheuse typique : neige ventée

Déclenchements provoqués :

Quelques plaques à vent dans la neige récente, elles continuent de se former mercredi en journée sous le vent de NNE. Elles sont friables voir dures, réactives au passage d'un skieur. Elles sont proches des crêtes (qui auront moins pris le vent) ou derrière les ruptures de pente. La Bise de NNE a soufflé fort ce lundi, les plaques peuvent aussi localement se trouver jusqu'en milieu des pentes, loin des crêtes (souvent décapées). Les cassures sont entre 20/30 cm et parfois 50/60 cm dans les accumulations. Taille 1 à 2, rarement 3 (petite à moyenne, rarement 3).

Observables : accumulations, fissures devant les skis, changement de qualité de neige sur une courte distance.

Départs spontanés :

Rares voir quelques départs spontanés à cause du vent sont encore possibles. Taille 1.

Rares coulées de neige humide sous une éclaircie dans les versants ensoleillés (sous les rochers), mais très limité à cause du vent. Taille 1.

Qualité de la neige

Enneigement :

Bon pour une fin mars. On peut chausser skis ou raquettes dès 1200/1300 m. Attention, absence de sous-couches sous 1500/1600 m en versants S.

Qualité de la neige ce mercredi :

Sous 2000 m : 5/15 cm de neige récente reposant sur une neige encore froide, présence d'une croute en profondeur sauf en Nord. Dans les versants ensoleillés, la neige s'humidifie en surface.

Au-dessus de 2000 m : 5/20 cm de neige récente, soufflée dans les secteurs soumis à la Bise. Dure ou glacée près des crêtes.

Nombreuses corniches et accumulations/congères.

Aperçu météo pour le mercredi 01 avril

nuit	matin	après-midi	soir

Entre nuages et éclaircies, encore bien venté et frais.

Pluie-Neige				
Iso 0 °C	1 200 m	1 400 m	1 500 m	1 400 m
Vent 2000 m	40 km/h	35 km/h	25 km/h	10 km/h
Vent 2500 m	65 km/h	50 km/h	40 km/h	20 km/h

Épaisseur de neige hors-piste

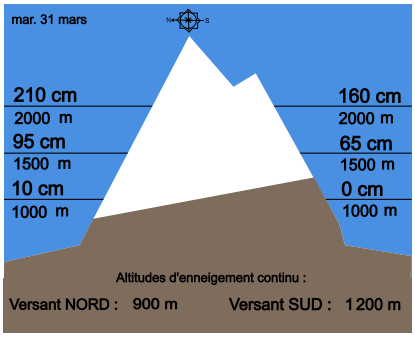

Précipitations à 1800 m

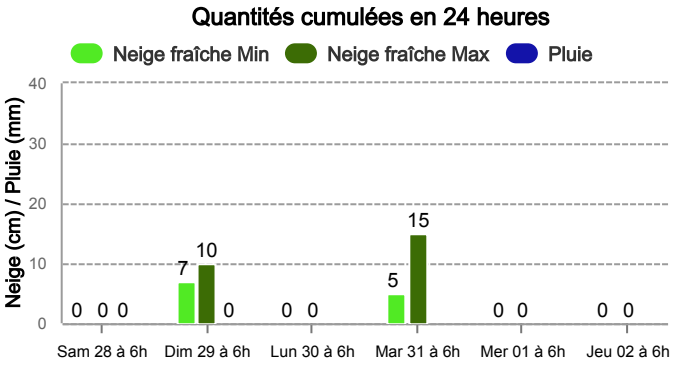

Tendance du jeudi 02 avril

2

Indice de risque limité

Les instabilités temporaires dues au vent diminuent rapidement avec la nette baisse du vent en soirée de mercredi.

Pour consulter la vigilance en cours, veuillez vous rendre sur le site https://vigilance.meteofrance.fr/fr

Météo-France - 73 avenue de Paris, 94165 Saint-Mandé cedex - Contact : contact@meteo.fr

Rédigé par Météo-France avec la contribution des observateurs du réseau nivo-météorologiques. Partenariat : ANMSM (Maires de Stations de Montagne), DSF (Domaines Skiables de France), ADSP (Directeurs de Pistes et de la Sécurité des Stations de Sports d'Hiver) et autres acteurs de la montagne.

Bulletin neige & avalanches par téléphone au
0 892 68 10 20 Service 0,35 € / min + prix appel

RÉPUBLIQUE FRANÇAISE
Liberté Égalité Fraternité

METEO FRANCE
À VOS CÔTÉS, DANS UN CLIMAT QUI CHANGE

Bulletin d'estimation du risque d'avalanche

(valable en dehors des pistes balisées et ouvertes)

MASSIF : Aravis

Rédigé le mardi 31 mars 2026 à 16h

Conditions nivo-météo des 7 derniers jours

	mer. 25/03				jeu. 26/03				ven. 27/03				sam. 28/03				dim. 29/03				lun. 30/03				mar. 31/03			
	03h	09h	15h	21h	03h	09h	15h	21h	03h	09h	15h	21h	03h	09h	15h	21h	03h	09h	15h	21h	03h	09h	15h	21h	03h	09h	15h	21h
Météo																												
Vent (km/h)	40	60	70	60	60	60	60	60	60	80	40	30	40	40	30	50	60	50	30	30	25	35	45	65	65	65	60	65
à 2500m																												
Vent (km/h)	30	40	60	45	45	40	50	50	45	60	30	20	30	30	20	40	50	30	20	20	10	20	35	40	45	40	45	40
à 2000m																												

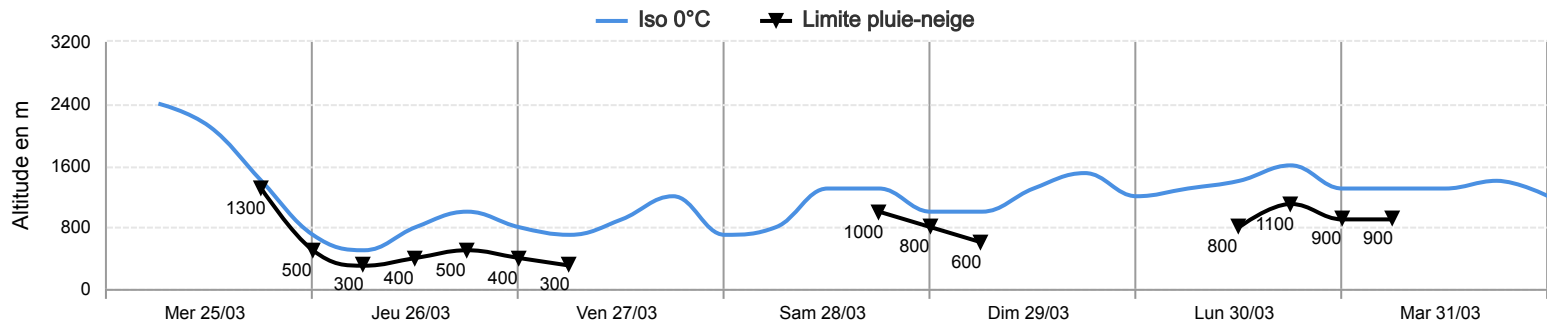

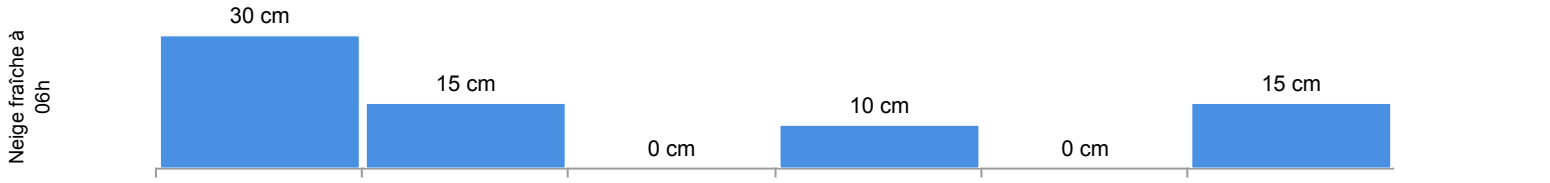

Risque d'avalanche	mer. 25/03	jeu. 26/03	ven. 27/03	sam. 28/03	dim. 29/03	lun. 30/03	mar. 31/03
	3	3	3	2	2	2	3

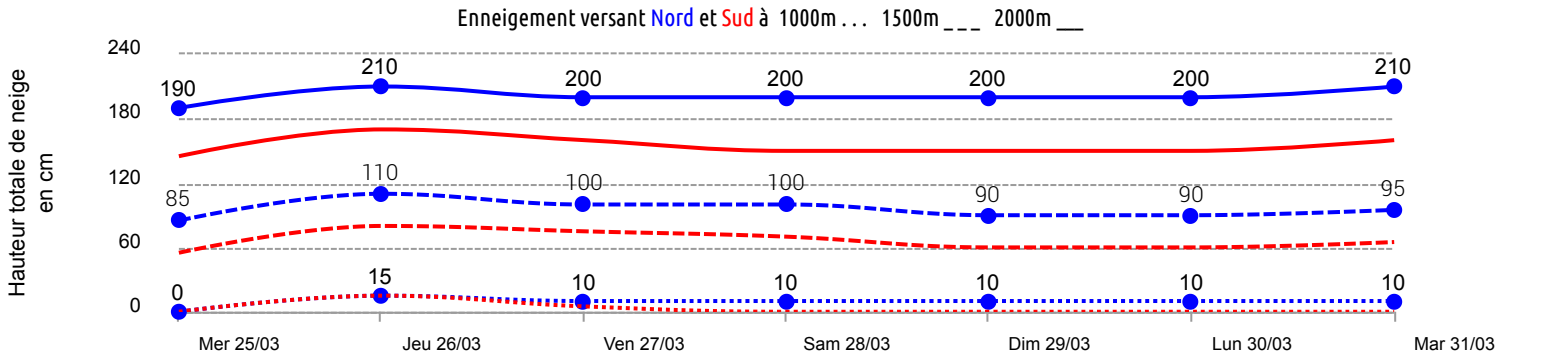

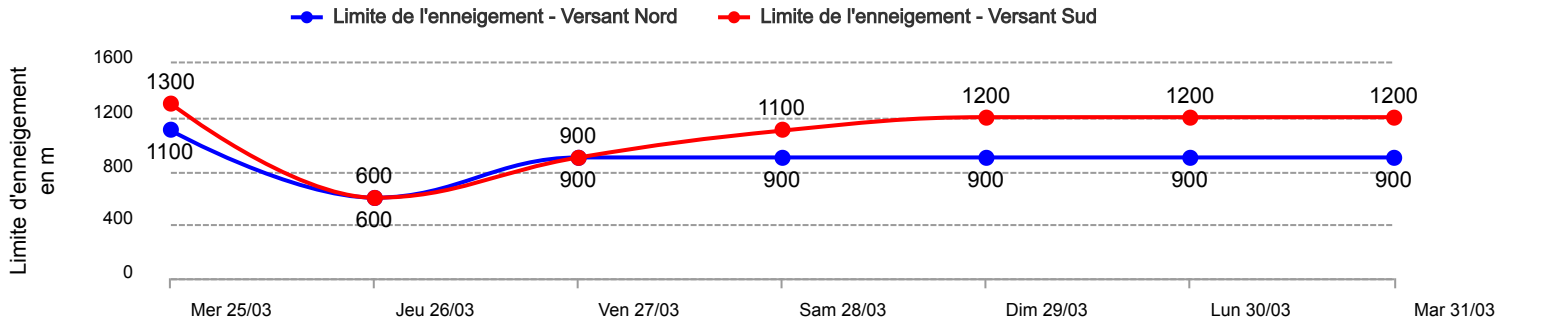

Pour consulter la vigilance en cours, veuillez vous rendre sur le site https://vigilance.meteofrance.fr/fr

Météo-France - 73 avenue de Paris, 94165 Saint-Mandé cedex - Contact : contact@meteo.fr

Bulletin neige & avalanches par téléphone au

0 892 68 10 20 Service 0,35 € / min + prix appel

Rédigé par Météo-France avec la contribution des observateurs du réseau nivo-météorologiques. Partenariat : ANMSM (Maires de Stations de Montagne), DSF (Domaines Skiables de France), ADSP (Directeurs de Pistes et de la Sécurité des Stations de Sports d'Hiver) et autres acteurs de la montagne.