Bulletin d'estimation du risque d'avalanche

(valable en dehors des pistes balisées et ouvertes)

MASSIF : Beaufortain

Rédigé le mardi 31 mars 2026 à 16h

Estimation des risques pour le : MERCREDI 01 AVRIL

LE MANTEAU ENCORE HIVERNAL ET LE VENT TOUJOURS SENSIBLE EN MATINÉE MAINTIENNENT LE RISQUE DE PLAQUES RÉACTIVES.

3

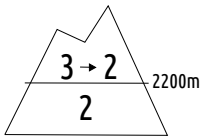

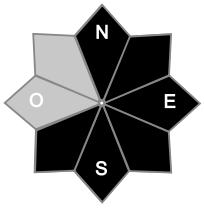

Au-dessus de 2200m indice de risque marqué évoluant en limité, plus bas indice limité.

Départs spontanés : petits départs sous le vent et au soleil.

Déclenchements provoqués : quelques plaques encore sensibles.

Indices de risque : 5 très fort - 4 fort - 3 marqué - 2 limité - 1 faible -- En noir : les pentes les plus dangereuses

Stabilité du manteau neigeux

Situation avalancheuse typique : neige ventée

Déclenchements provoqués : Quelques plaques sont encore alimentées par le vent de Nord à Nord-Est en matinée. Elles sont temporairement très réactives tant que le vent transporte encore la neige. On les trouve surtout dans les zones d'accumulation sous le vent (derrière les crêtes, croupes ou ruptures de pente), et jusqu'en bas des versants. Elles sont plus fréquentes au-dessus de 2000 m (limite haute des arbres) et dans les versants Sud-Ouest à Est (et Nord dans une moindre mesure). Les cassures atteignent 30 à 50 cm, pour des avalanches peu larges, de taille 1 à 2 (petite à moyenne). L'après-midi, avec la décélération du vent, les plaques tendent à être moins réactives.

Départs spontanés :
- Quelques petites coulées sont attendues dans les pentes raides avec l'humidification de la neige fraîche par le soleil. Taille 1.
- Un petit départ linéaire sous le vent de Nord à Nord-Est reste possible le matin. Taille 1 à 2.

Qualité de la neige

Enneigement : un peu au dessus de la moyenne, ces derniers jours hivernaux retardent quelques peu l'inéluctable fonte printanière.

Limite skiable : vers 1200 m en Nord, 1500 m en Sud.

Qualité de la neige : couche de neige fraîche rendue très hétérogène par le vent : en moyenne ~10/15 cm vers 2000 m, parfois rien et l'ancienne neige est en surface, parfois plus du double dans les trous, qu'il faut viser pour faire du bon ski. Généralement densifiée par le vent, et même cartonnée à durcie près des crêtes. Seules les zones très abritées ou boisées sont encore en poudre légère. Une croute peut-être présente en Sud à Ouest.

Aperçu météo pour le mercredi 01 avril

	nuit	matin	après-midi	soir

Beau le matin, nombreux nuages sur le relief l'après-midi. Vent faiblissant.

Pluie-Neige				
Iso 0 °C	1 200 m	1 500 m	2 000 m	1 400 m
Vent 2000 m	30 km/h	30 km/h	10 km/h	15 km/h
Vent 3000 m	50 km/h	40 km/h	20 km/h	30 km/h

Épaisseur de neige hors-piste

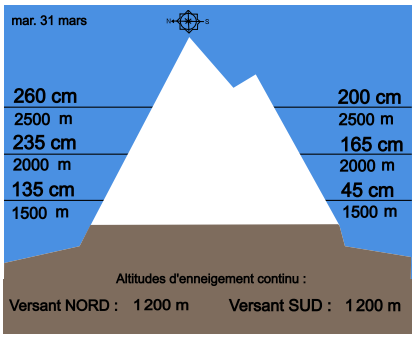

Précipitations à 1800 m

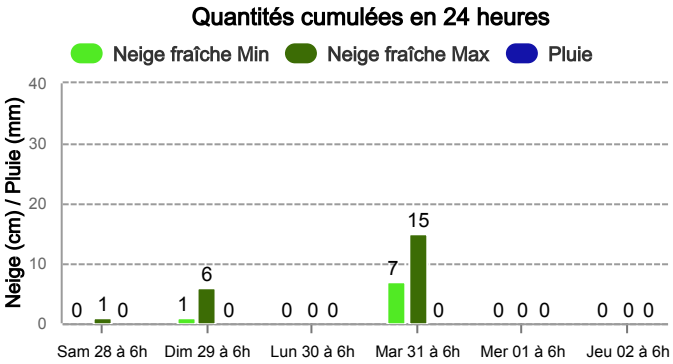

Tendance du jeudi 02 avril

2

Indice de risque limité

Le temps reste frais et calme, permettant la neutralisation progressive des instabilités.

Pour consulter la vigilance en cours, veuillez vous rendre sur le site https://vigilance.meteofrance.fr/fr

Météo-France - 73 avenue de Paris, 94165 Saint-Mandé cedex - Contact : contact@meteo.fr

Rédigé par Météo-France avec la contribution des observateurs du réseau nivo-météorologiques. Partenariat : ANMSM (Maires de Stations de Montagne), DSF (Domaines Skiables de France), ADSP (Directeurs de Pistes et de la Sécurité des Stations de Sports d'Hiver) et autres acteurs de la montagne.

Bulletin neige & avalanches par téléphone au

0 892 68 10 20 Service 0,35 € / min + prix appel

RÉPUBLIQUE FRANÇAISE
Liberté Égalité Fraternité

METEO FRANCE
À VOS CÔTÉS, DANS UN CLIMAT QUI CHANGE

Bulletin d'estimation du risque d'avalanche

(valable en dehors des pistes balisées et ouvertes)

MASSIF : Beaufortain

Rédigé le mardi 31 mars 2026 à 16h

Conditions nivo-météo des 7 derniers jours

	mer. 25/03				jeu. 26/03				ven. 27/03				sam. 28/03				dim. 29/03				lun. 30/03				mar. 31/03			
	03h	09h	15h	21h	03h	09h	15h	21h	03h	09h	15h	21h	03h	09h	15h	21h	03h	09h	15h	21h	03h	09h	15h	21h	03h	09h	15h	21h
Météo																												
Vent (km/h)	50	60	80	80	75	65	70	60	50	50	30	30	30	30	30	30	30	20	20	15	15	45	55	60	65	65	65	55
à 3000m																												
Vent (km/h)	30	40	65	65	60	50	55	50	45	30	20	20	20	20	20	20	20	15	15	5	5	15	45	50	50	50	50	35
à 2000m																												

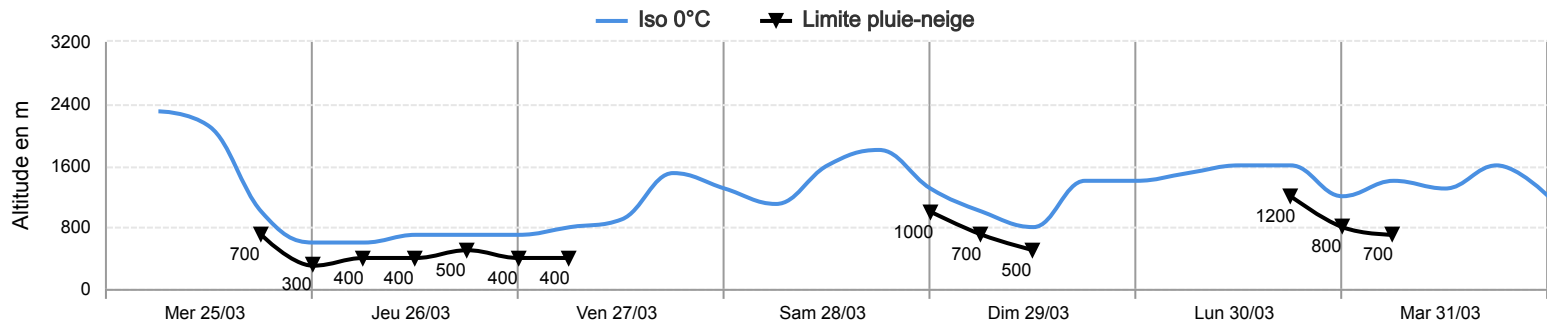

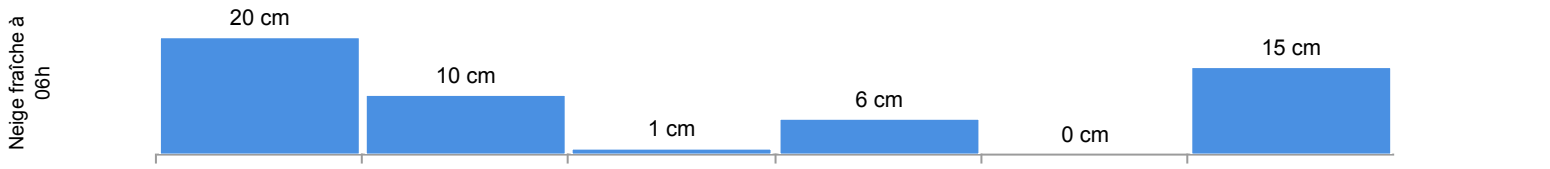

Risque d'avalanche	mer. 25/03	jeu. 26/03	ven. 27/03	sam. 28/03	dim. 29/03	lun. 30/03	mar. 31/03
	3	3	3	2	2	2	3

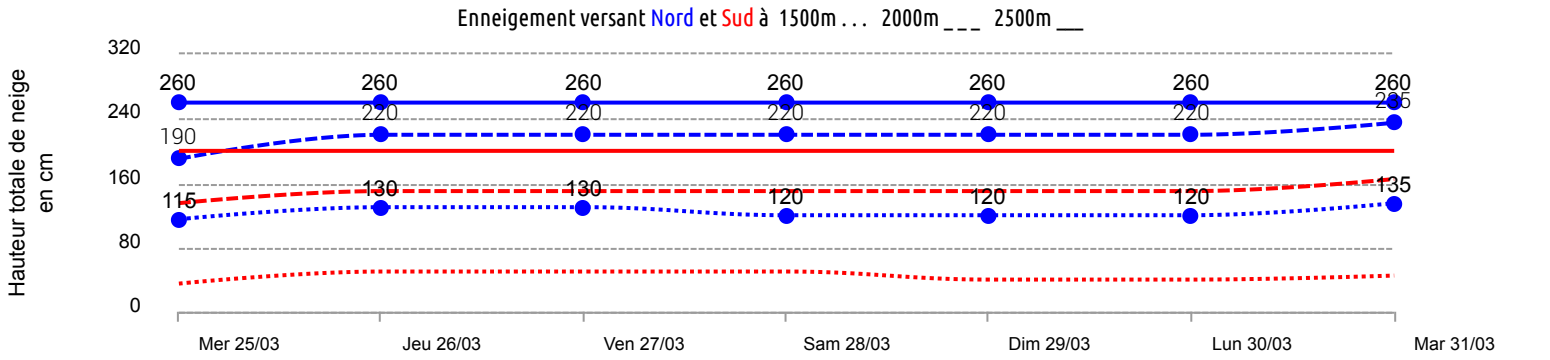

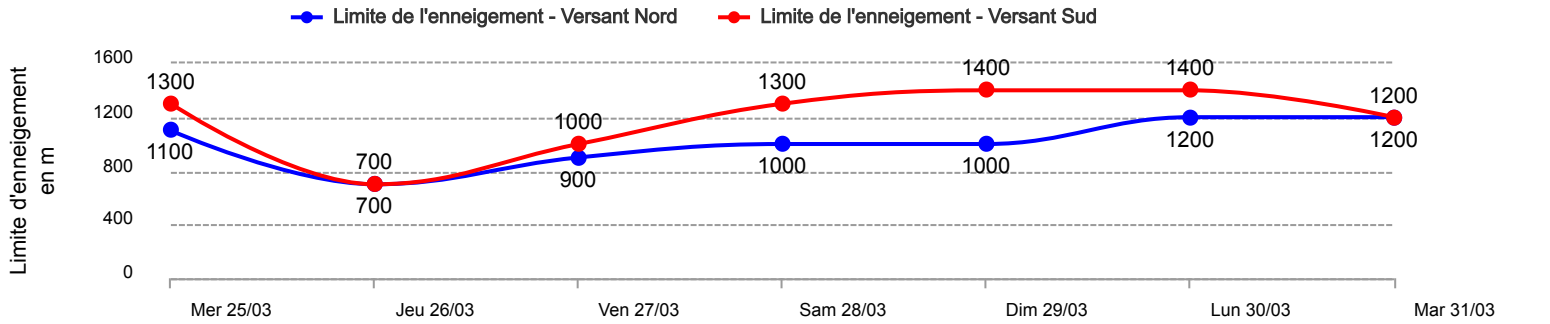

Pour consulter la vigilance en cours, veuillez vous rendre sur le site https://vigilance.meteofrance.fr/fr

Météo-France - 73 avenue de Paris, 94165 Saint-Mandé cedex - Contact : contact@meteo.fr

Rédigé par Météo-France avec la contribution des observateurs du réseau nivo-météorologiques. Partenariat : ANMSM (Maires de Stations de Montagne), DSF (Domaines Skiables de France), ADSP (Directeurs de Pistes et de la Sécurité des Stations de Sports d'Hiver) et autres acteurs de la montagne.

Bulletin neige & avalanches par téléphone au
0 892 68 10 20 Service 0,35 € / min + prix appel