Bulletin d'estimation du risque d'avalanche

(valable en dehors des pistes balisées et ouvertes)

MASSIF : Capcir Puymorens

Rédigé le mardi 31 mars 2026 à 16h

Estimation des risques pour le : MERCREDI 01 AVRIL

INSTABILITÉS DANS LA NEIGE FRAICHE

3

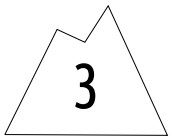

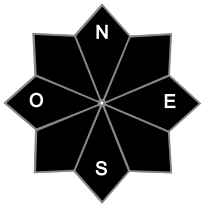

Indice de risque marqué.

Départs spontanés : En pentes raides au fur et à mesure des chutes et du transport

Déclenchements provoqués : Nombreuses plaques facilement déclenchables

Indices de risque : 5 très fort - 4 fort - 3 marqué - 2 limité - 1 faible -- En noir : les pentes les plus dangereuses

Stabilité du manteau neigeux

Situation avalancheuse typique : neige fraîche neige ventée

Départs spontanés :

Des départs ponctuels ou linéaires d'avalanches de neige fraiche sont attendus dans les pentes raides en toutes orientations. Ces avalanches seront de plus en plus nombreuses et volumineuses au fil des heures et en prenant de l'altitude : de taille petite à moyenne en matinée, moyenne à grande en fin d'échéance avec des précipitations qui se renforcent en fin d'après-midi et soirée.

Facteurs aggravants : le vent turbulent qui souffle encore fort et qui formera des accumulations parfois loin des crêtes, créant localement des surcharges additionnelles.

Déclenchements provoqués :

De nombreuses structures de plaques facilement déclenchables sont présentes dans la neige récente et continuent de se former avec les nouvelles chutes et le vent turbulent. Les plus épaisses sont situées préférentiellement dans un large versant sud, mais pas uniquement. Elles sont parfois difficilement détectables, masquées par les chutes récentes. Elles donnent des avalanches de taille petite à moyenne, plus rarement grande en fin de journée.

Observables : Quantité de neige fraiche, surface hétérogène travaillée par le vent, fissures devant les skis, "woomfs".

Autre :

Faible visibilité pendant les chutes et avec le transport, froid sensible avec le vent, corniches volumineuses sous les crêtes

Qualité de la neige

Enneigement :

L'enneigement est excellent et parmi les meilleurs de ces 20 dernières années. En altitude, les cumuls sont très conséquents, même si les crêtes et sommets exposés au vent d'ouest à nord-ouest sont souvent dégarnis.

Il est envisageable de chausser les skis vers 1300m mais on retrouvera une sous-couche permettant de progresser plus sereinement plutôt à partir de 1600 m.

Qualité de la neige :

Mercredi matin on trouvera une petite couche de neige fraîche au-dessus d'une neige récente qui aura commencé à s'humidifier sous 1700m/1800m. En altitude, l'enneigement et la qualité de la neige seront hétérogènes sous l'action du vent soufflant depuis samedi, avec des zones d'accumulations où la neige fraîche et/ou récente reste localement légère et des zones proches des crêtes Ouest à Nord-Ouest pelées ou en neige dure, voire glacée.

Aperçu météo pour le mercredi 01 avril

Temps hivernal	nuit	matin	après-midi	soir
Pluie-Neige	1 200 m	1 100 m	1 400 m	1 400 m
Iso 0 °C	1 600 m	1 700 m	1 900 m	1 700 m
Vent 2000 m	↓ 80 km/h	↘ 75 km/h	↘ 85 km/h	↓ 85 km/h
Vent 3000 m	↘ 90 km/h	↘ 85 km/h	↘ 90 km/h	↘ 95 km/h

Épaisseur de neige hors-piste

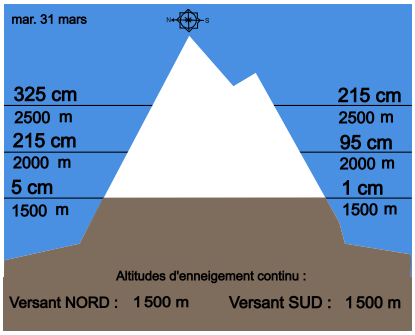

Précipitations à 1800 m

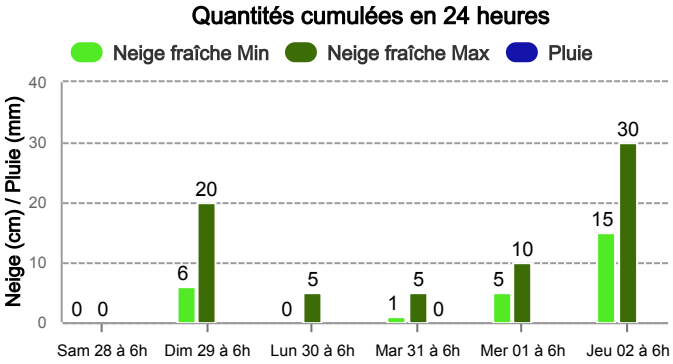

Tendance du jeudi 02 avril

3

Indice de risque marqué

Maintien d'un risque marqué avec de nouvelles chutes de neige et un manteau encore peu stabilisé

Pour consulter la vigilance en cours, veuillez vous rendre sur le site https://vigilance.meteofrance.fr/fr

Météo-France - 73 avenue de Paris, 94165 Saint-Mandé cedex - Contact : contact@meteo.fr

Rédigé par Météo-France avec la contribution des observateurs du réseau nivo-météorologiques. Partenariat : ANMSM (Maires de Stations de Montagne), DSF (Domaines Skiables de France), ADSP (Directeurs de Pistes et de la Sécurité des Stations de Sports d'Hiver) et autres acteurs de la montagne.

Bulletin neige & avalanches par téléphone au

0 892 68 10 20 Service 0,35 € / min + prix appel

RÉPUBLIQUE FRANÇAISE
Liberté Égalité Fraternité

METEO FRANCE
À VOS CÔTÉS, DANS UN CLIMAT QUI CHANGE

Bulletin d'estimation du risque d'avalanche

(valable en dehors des pistes balisées et ouvertes)

MASSIF : Capcir Puymorens

Rédigé le mardi 31 mars 2026 à 16h

Conditions nivo-météo des 7 derniers jours

	mer. 25/03				jeu. 26/03				ven. 27/03				sam. 28/03				dim. 29/03				lun. 30/03				mar. 31/03			
	03h	09h	15h	21h	03h	09h	15h	21h	03h	09h	15h	21h	03h	09h	15h	21h	03h	09h	15h	21h	03h	09h	15h	21h	03h	09h	15h	21h
Météo																												
Vent (km/h)	30	55	75	90	90	100	95	105	95	95	85	70	60	70	85	105	115	110	95	85	80	80	95	100	95	85	95	95
à 3000m	↘	↘	↘	↘	↘	↘	↘	↘	↘	↓	↓	↘	↓	↓	↘	↘	↓	↓	↘	↘	↘	↓	↘	↘	↘	↘	↘	↘
Vent (km/h)	15	35	50	70	75	80	80	85	75	75	65	60	45	60	60	80	90	90	80	65	70	70	80	85	80	80	80	80
à 2000m	→	↘	↘	↘	↘	↘	↘	↘	↘	↘	↘	↘	↓	↓	↓	↓	↘	↓	↓	↓	↓	↓	↘	↓	↘	↘	↘	↓

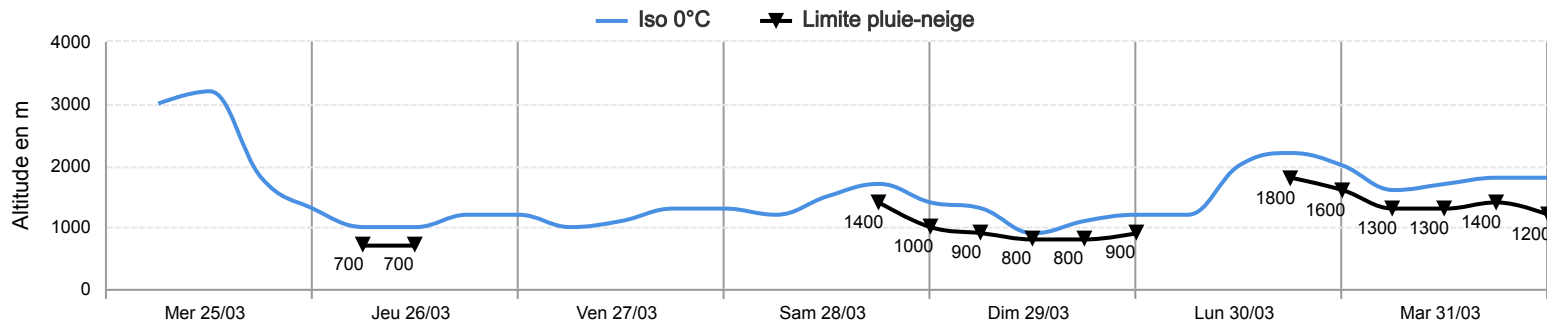

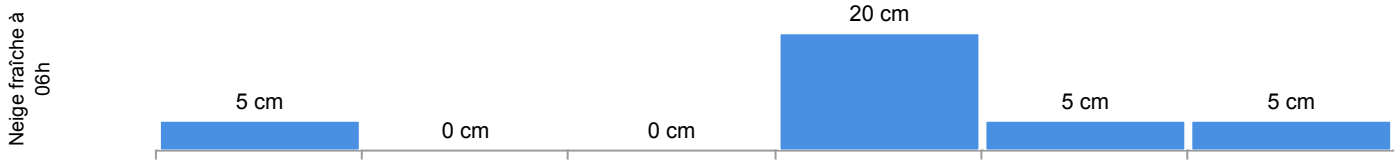

Risque d'avalanche	mer. 25/03	jeu. 26/03	ven. 27/03	sam. 28/03	dim. 29/03	lun. 30/03	mar. 31/03
	2	2	2	2	3	3	3

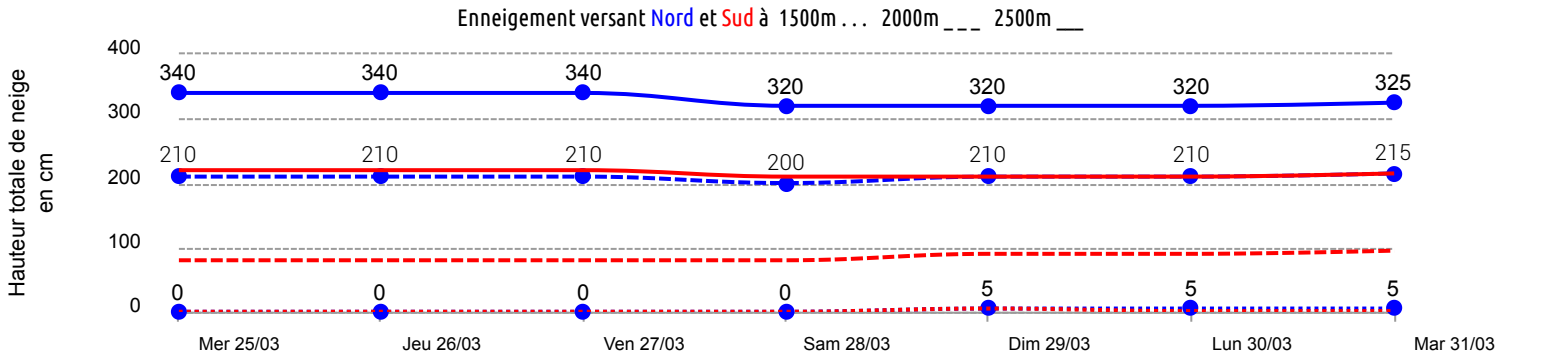

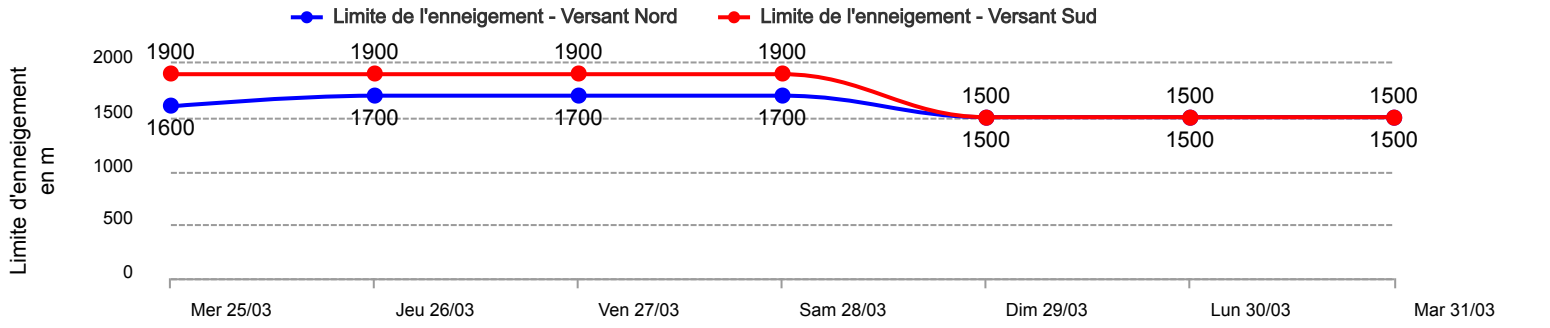

Pour consulter la vigilance en cours, veuillez vous rendre sur le site https://vigilance.meteofrance.fr/fr

Météo-France - 73 avenue de Paris, 94165 Saint-Mandé cedex - Contact : contact@meteo.fr

Rédigé par Météo-France avec la contribution des observateurs du réseau nivo-météorologiques. Partenariat : ANMSM (Maires de Stations de Montagne), DSF (Domaines Skiables de France), ADSP (Directeurs de Pistes et de la Sécurité des Stations de Sports d'Hiver) et autres acteurs de la montagne.

Bulletin neige & avalanches par téléphone au
0 892 68 10 20 Service 0,35 € / min + prix appel