Bulletin d'estimation du risque d'avalanche

(valable en dehors des pistes balisées et ouvertes)

MASSIF : Chartreuse

Rédigé le mardi 31 mars 2026 à 16h

Estimation des risques pour le : MERCREDI 01 AVRIL

MANTEAU HIVERNAL, HEBERGEANT QUELQUES PLAQUES FORMEES PAR LE VENT

2

2

N O E S

Indice de risque limité.

Départs spontanés : De rares ruptures de petites plaques possibles dans les pentes sous le vent

Déclenchements provoqués : Quelques plaques à vent peu épaisses mais réactives

Indices de risque : 5 très fort - 4 fort - 3 marqué - 2 limité - 1 faible -- En noir : les pentes les plus dangereuses

Stabilité du manteau neigeux

Situation avalancheuse typique : neige ventée

Déclenchements provoqués : Quelques nouvelles plaques se forment encore ce mercredi sous le vent de Nord à Nord-Est. Ces instabilités se retrouvent même loin des crêtes / jusque dans les bas de pentes et en tout versant, mais sont de manière générale plus nombreuses en large Sud. Les plaques restent très localisées, sont peu larges et peu épaisses, mais peuvent être réactives pendant l'épisode de vent. L'après-midi, le vent faiblit et n'est plus suffisamment fort pour transporter efficacement de la neige et former de nouvelles instabilités. Les plaques formées en matinée se stabilisent progressivement.
Observables : Transport en cours, accumulation, neige sculptée par le vent.
Départs spontanés : Dans les pentes chargées par le vent (généralement en large Sud) de rares ruptures de plaques de tailles petites à moyennes restent possible jusqu'à la fin de l'épisode de vent, autour du milieu de journée. L'après-midi, de petites coulées sont possibles sous les rochers qui prennent le soleil.

Qualité de la neige

Qualification de l'enneigement : L'enneigement est bon à basse altitude, et même très bon dés 1800 / 2000m mais avec des répartitions assez hétérogènes à cause du vent. Peu de sous couche sous 1700m en plein Sud.
Limites skiables : Vers 1000 / 1200m selon le versant, avec prudence en Sud / sous les sapins

Qualité de la neige mercredi : Neige souvent travaillée voire cartonnée par le vent. Les crêtes et versants Nord exposés au vent sont souvent pelés, faisant ressortir une vieille neige dure / croûtée. On peut encore retrouver quelques combes en poudreuse, à priori plutôt celles abritées du vent de Nord (où la neige aura été soufflée, ou parfois croûtée par la pluie).

Aperçu météo pour le mercredi 01 avril

nuit	matin	après-midi	soir

Assez belle matinée, avec quelques nuages vers les sommets, mais sous un vent de Nord toujours fort. L'après-midi le vent baisse d'un cran mais le ciel se charge à nouveau.

Pluie-Neige				
Iso 0 °C	1 100 m	1 200 m	1 500 m	1 300 m
Vent 1500 m	35 km/h	35 km/h	45 km/h	20 km/h
Vent 2000 m	60 km/h	50 km/h	40 km/h	30 km/h

Épaisseur de neige hors-piste

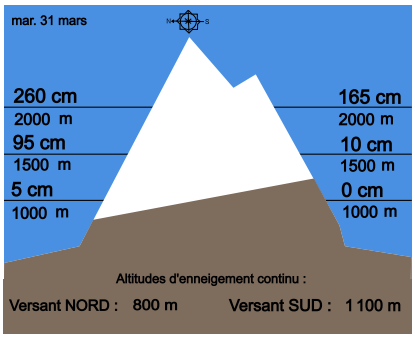

Précipitations à 1800 m

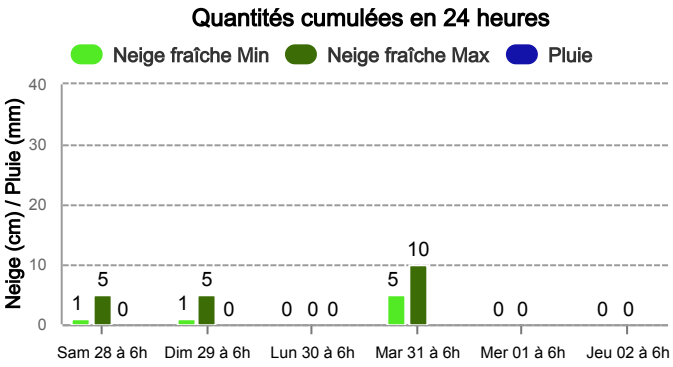

Tendance du jeudi 02 avril

2

Indice de risque limité

Jeudi, risque limité. Assez belle journée, sous un léger vent de Nord. Les plaques se stabilisent. Quelques coulées de petites tailles au soleil.

Pour consulter la vigilance en cours, veuillez vous rendre sur le site https://vigilance.meteofrance.fr/fr

Météo-France - 73 avenue de Paris, 94165 Saint-Mandé cedex - Contact : contact@meteo.fr

Rédigé par Météo-France avec la contribution des observateurs du réseau nivo-météorologiques. Partenariat : ANMSM (Maires de Stations de Montagne), DSF (Domaines Skiables de France), ADSP (Directeurs de Pistes et de la Sécurité des Stations de Sports d'Hiver) et autres acteurs de la montagne.

Bulletin neige & avalanches par téléphone au 0 892 68 10 20 Service 0,35 € / min + prix appel

RÉPUBLIQUE FRANÇAISE
Liberté Égalité Fraternité

METEO FRANCE
À VOS CÔTÉS, DANS UN CLIMAT QUI CHANGE

Bulletin d'estimation du risque d'avalanche

(valable en dehors des pistes balisées et ouvertes)

MASSIF : Chartreuse

Rédigé le mardi 31 mars 2026 à 16h

Conditions nivo-météo des 7 derniers jours

	mer. 25/03				jeu. 26/03				ven. 27/03				sam. 28/03				dim. 29/03				lun. 30/03				mar. 31/03			
	03h	09h	15h	21h	03h	09h	15h	21h	03h	09h	15h	21h	03h	09h	15h	21h	03h	09h	15h	21h	03h	09h	15h	21h	03h	09h	15h	21h
Météo																												
Vent (km/h)	25	50	80	80	90	80	75	70	75	70	45	30	45	55	40	60	60	50	35	40	45	40	60	65	75	65	65	70
à 2000m																												
Vent (km/h)	10	25	55	50	50	45	55	45	40	55	35	20	35	40	25	40	40	35	20	30	30	30	50	50	50	55	55	60
à 1500m																												

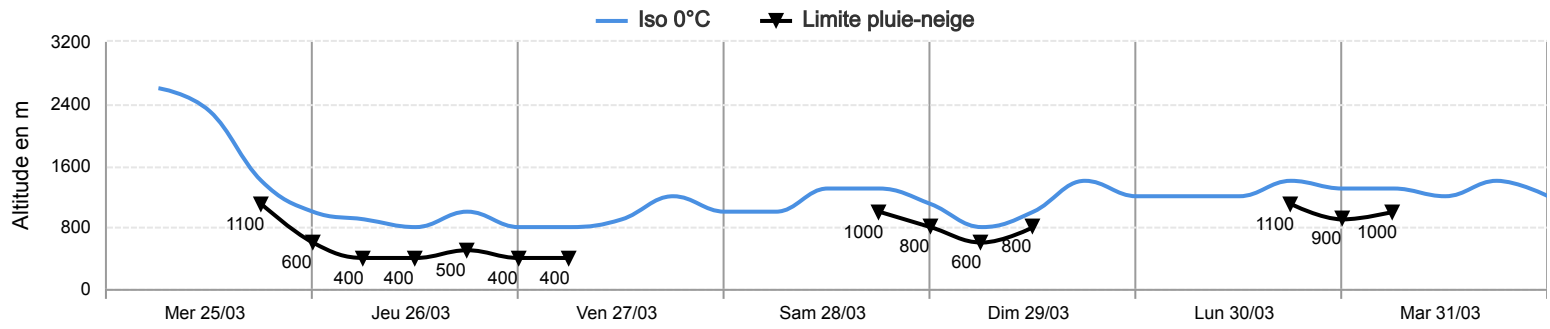

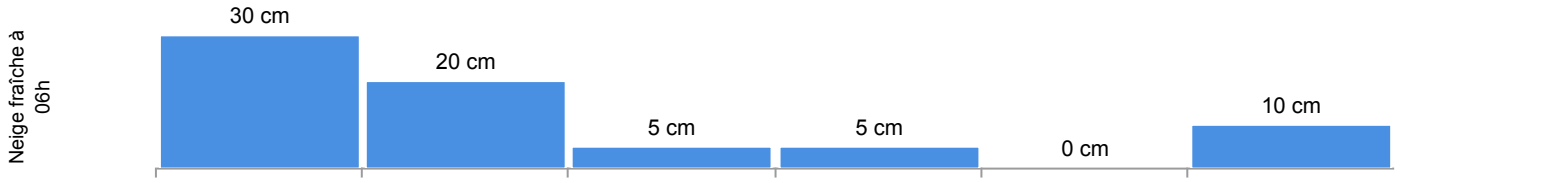

Risque d'avalanche	mer. 25/03	jeu. 26/03	ven. 27/03	sam. 28/03	dim. 29/03	lun. 30/03	mar. 31/03
	2	4	3	2	2	2	2

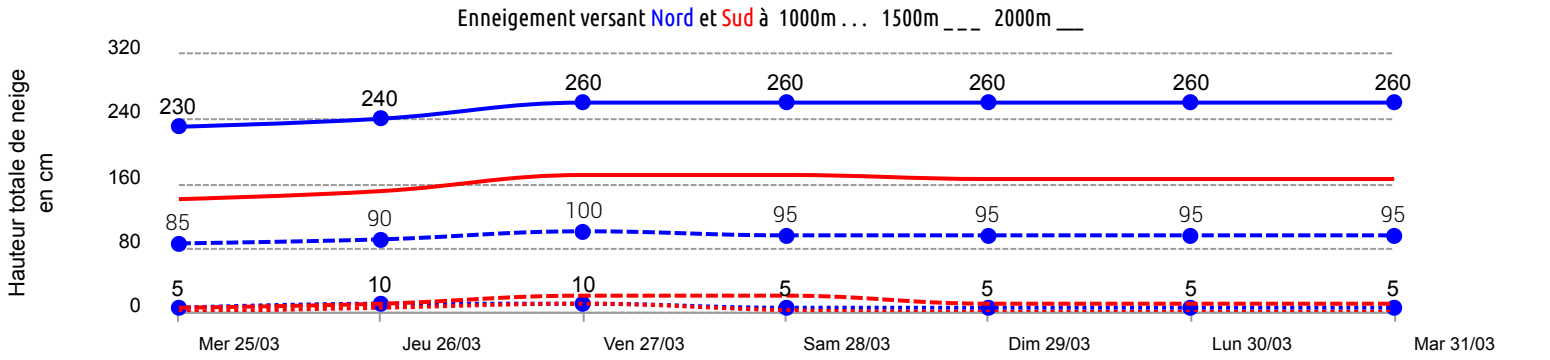

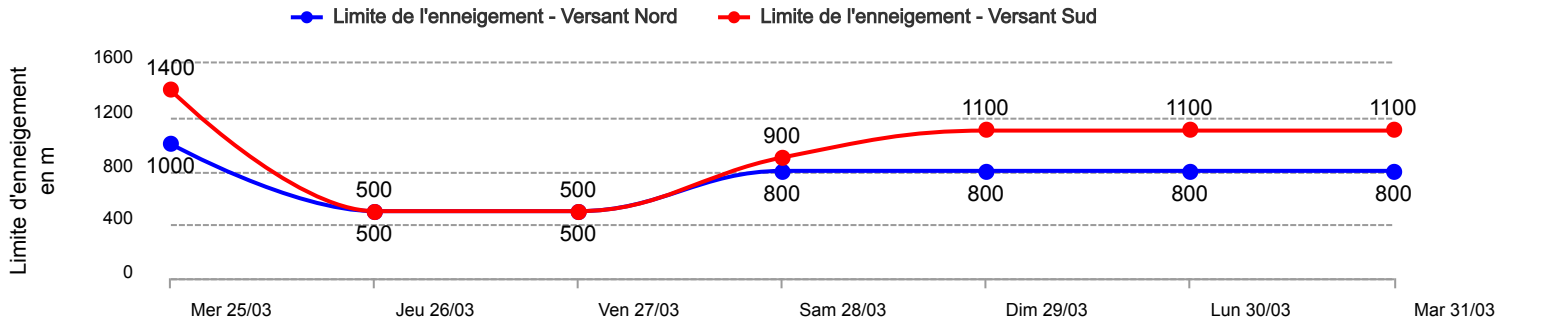

Pour consulter la vigilance en cours, veuillez vous rendre sur le site https://vigilance.meteofrance.fr/fr

Météo-France - 73 avenue de Paris, 94165 Saint-Mandé cedex - Contact : contact@meteo.fr

Rédigé par Météo-France avec la contribution des observateurs du réseau nivo-météorologiques. Partenariat : ANMSM (Maires de Stations de Montagne), DSF (Domaines Skiables de France), ADSP (Directeurs de Pistes et de la Sécurité des Stations de Sports d'Hiver) et autres acteurs de la montagne.

Bulletin neige & avalanches par téléphone au
0 892 68 10 20 Service 0,35 € / min + prix appel