Bulletin d'estimation du risque d'avalanche
(valable en dehors des pistes balisées et ouvertes)

MASSIF : Embrunais Parpaillon

Rédigé le mardi 31 mars 2026 à 16h

Estimation des risques pour le : MERCREDI 01 AVRIL

QUELQUES PLAQUES EN ALTITUDE DANS LA NEIGE VENTÉE

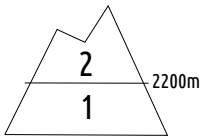

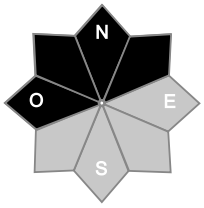

Au-dessus de 2200m indice de risque limité, plus bas indice faible.

Départs spontanés : peu probables

Déclenchements provoqués : quelques plaques dans la neige ventée, plus épaisses en altitude

Indices de risque : 5 très fort - 4 fort - 3 marqué - 2 limité - 1 faible -- En noir : les pentes les plus dangereuses

Stabilité du manteau neigeux

Situation avalancheuse typique : neige ventée

Déclenchements provoqués : plaques dures en place dans la neige ventée et entretenues par la Lombarde modérée. Présentes au-dessus de 2200 m environ dans les orientations d'un large secteur nord (ouest, nord et nord-est) , ces plaques sont néanmoins plus nombreuses et sensibles vers le Parpaillon où les quantités de neige récente sont un peu plus importantes. Facilement déclenchables par le passage d'un skieur, ces instabilités génèrent des avalanches de taille petite (taille 1), voire moyenne (taille 2) aux plus hautes altitudes du massif.

Départs spontanés : rares ruptures par surcharge du au vent. Avalanche petite à moyenne (taille 1, rarement 2).

Qualité de la neige

L'enneigement est proche des normales pour une fin mars.
Hauteurs de neige observées : 107 cm à la nivôse du Parpaillon à 2500 m.

Limite d'enneigement skiable : au plus bas à 1500 m en ubacs bien protégés ou sur pistes forestières, plutôt 2000/2100 m en adrets.

État de la neige de surface : neige récente fortement travaillée par le vent, mais localement encore légère dans les secteurs bien abrités. Crêtes parfois décapées. En versant sud, neige croutée sous 2500 m.

Aperçu météo pour le mercredi 01 avril

	nuit	matin	après-midi	soir

Temps sec et encore venté. 0° à 2000 m et -8° à 3000 m.

Pluie-Neige				
Iso 0 °C	1 600 m	1 800 m	2 100 m	1 700 m
Vent 2000 m	↙ 25 km/h	↙ 25 km/h	↙ 35 km/h	↙ 35 km/h
Vent 3000 m	↙ 40 km/h	↙ 40 km/h	↙ 50 km/h	← 50 km/h

Épaisseur de neige hors-piste

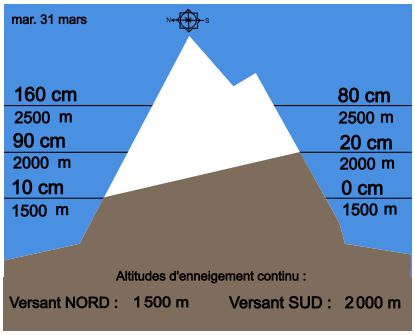

Précipitations à 1800 m

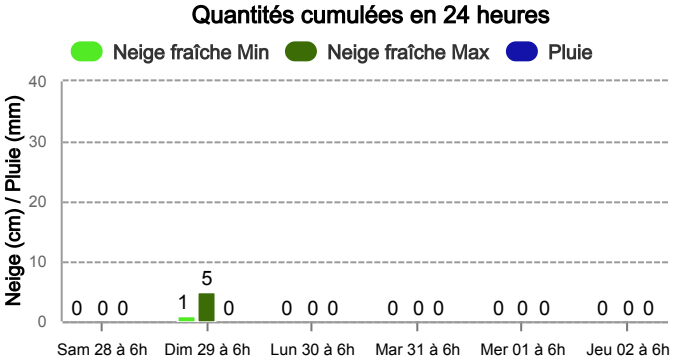

Tendance du jeudi 02 avril

Indice de risque limité

Maintien d'un risque limité avec des plaques résiduelles en altitude. Reprise de l'humidification en sud.

Pour consulter la vigilance en cours, veuillez vous rendre sur le site https://vigilance.meteofrance.fr/fr

Météo-France - 73 avenue de Paris, 94165 Saint-Mandé cedex - Contact : contact@meteo.fr

Rédigé par Météo-France avec la contribution des observateurs du réseau nivo-météorologiques. Partenariat : ANMSM (Maires de Stations de Montagne), DSF (Domaines Skiables de France), ADSP (Directeurs de Pistes et de la Sécurité des Stations de Sports d'Hiver) et autres acteurs de la montagne.

Bulletin neige & avalanches par téléphone au **0 892 68 10 20** Service 0,35 € / min + prix appel

RÉPUBLIQUE FRANÇAISE
Liberté Égalité Fraternité

METEO FRANCE
À VOS CÔTÉS, DANS UN CLIMAT QUI CHANGE

Bulletin d'estimation du risque d'avalanche
(valable en dehors des pistes balisées et ouvertes)
MASSIF : Embrunais Parpaillon

Rédigé le mardi 31 mars 2026 à 16h

Conditions nivo-météo des 7 derniers jours

	mer. 25/03				jeu. 26/03				ven. 27/03				sam. 28/03				dim. 29/03				lun. 30/03				mar. 31/03			
	03h	09h	15h	21h	03h	09h	15h	21h	03h	09h	15h	21h	03h	09h	15h	21h	03h	09h	15h	21h	03h	09h	15h	21h	03h	09h	15h	21h
Météo																												
Vent (km/h)	30	50	60	70	30	60	70	70	50	40	30	10	30	25	30	25	25	40	25	20	30	50	80	90	80	70	60	45
à 3000m																												
Vent (km/h)	10	15	50	30	20	50	60	50	45	40	20	10	10	10	20	20	20	30	25	15	10	20	50	70	70	60	45	30
à 2000m																												

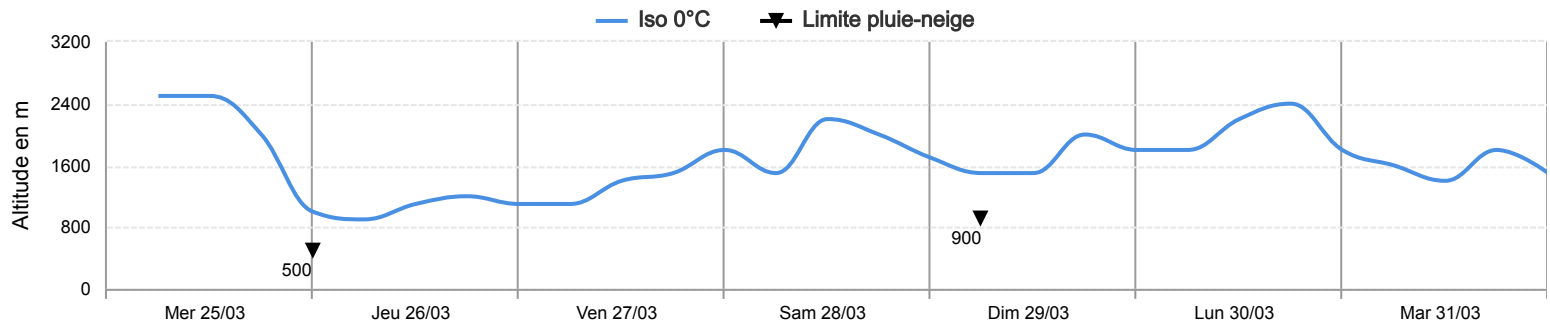

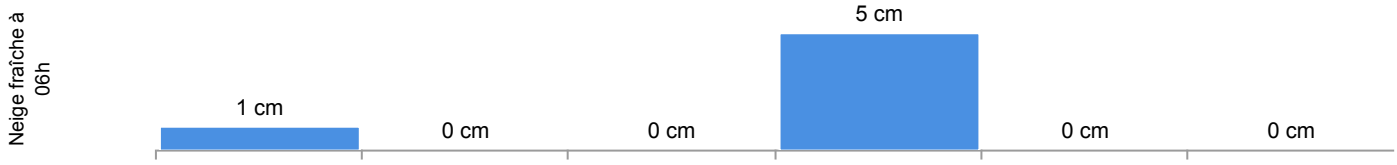

Risque d'avalanche	mer. 25/03	jeu. 26/03	ven. 27/03	sam. 28/03	dim. 29/03	lun. 30/03	mar. 31/03
	2	3	2	2	2	2	2

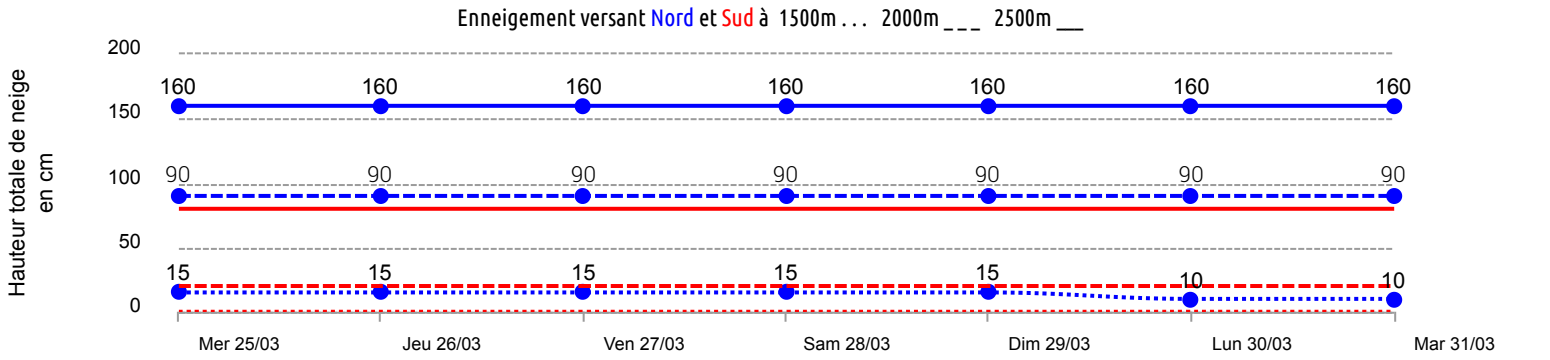

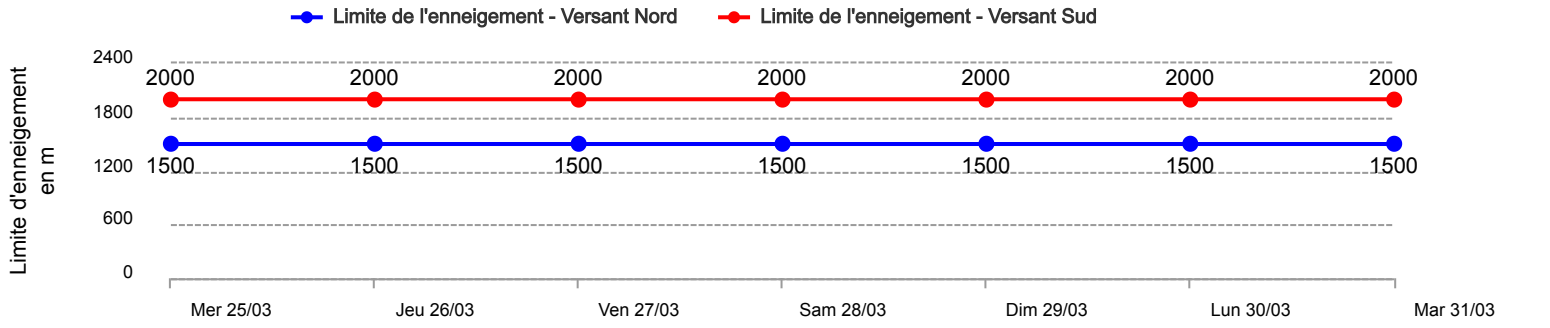

Pour consulter la vigilance en cours, veuillez vous rendre sur le site https://vigilance.meteofrance.fr/fr

Météo-France - 73 avenue de Paris, 94165 Saint-Mandé cedex - Contact : contact@meteo.fr

Rédigé par Météo-France avec la contribution des observateurs du réseau nivo-météorologiques. Partenariat : ANMSM (Maires de Stations de Montagne), DSF (Domaines Skiables de France), ADSP (Directeurs de Pistes et de la Sécurité des Stations de Sports d'Hiver) et autres acteurs de la montagne.

Bulletin neige & avalanches par téléphone au
0 892 68 10 20 Service 0,35 € / min + prix appel