Bulletin d'estimation du risque d'avalanche
(valable en dehors des pistes balisées et ouvertes)
MASSIF : Haute-Ariege

Rédigé le mardi 31 mars 2026 à 16h

Estimation des risques pour le : MERCREDI 01 AVRIL

INSTABILITÉS SE GÉNÉRALISANT DANS LA NEIGE FRAICHE

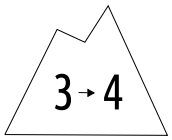

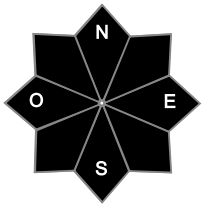

Indice de risque marqué évoluant en fort.

Départs spontanés : De plus en plus nombreux et volumineux

Déclenchements provoqués : Plaques épaisses et facilement déclenchables

Indices de risque : 5 très fort - 4 fort - 3 marqué - 2 limité - 1 faible -- En noir : les pentes les plus dangereuses

Stabilité du manteau neigeux

Situation avalancheuse typique : neige fraîche

Départs spontanés :
Des départs ponctuels ou linéaires d'avalanches de neige fraiche sont attendus dans les pentes raides en toutes orientations. Ces avalanches seront de plus en plus nombreuses et volumineuses en prenant de l'altitude : de taille petite à moyenne en matinée, moyenne à grande, voir exceptionnellement très grande en fin d'échéance avec des précipitations qui se renforcent en fin d'après-midi et soirée.
Facteurs aggravants : le vent turbulent qui souffle encore fort et qui formera des accumulations parfois loin des crêtes, créant localement des surcharges importantes.

Déclenchements provoqués :
De nombreuses structures de plaques facilement déclenchables sont présentes dans la neige récente et continuent de se former avec les nouvelles chutes et le vent turbulent. Les plus épaisses sont situées préférentiellement dans un large versant sud, mais pas uniquement. Elles sont parfois difficilement détectables, masquées par les chutes récentes. Elles donnent des avalanches de taille moyenne à grande en fin de journée.
Observables : Quantité de neige fraiche, surface hétérogène travaillée par le vent, fissures devant les skis, "woomfs".

Autre :
Faible visibilité pendant les chutes et avec le transport, froid sensible avec le vent, corniches volumineuses sous les crêtes

Qualité de la neige

Enneigement :
L'enneigement est très bon pour la saison. En altitude, les cumuls sont conséquents, mais les crêtes et sommets exposés au vent d'ouest à nord-ouest sont souvent dégarnis.
Il est envisageable de chausser les skis vers 1200/1300m mais on retrouvera une sous-couche permettant de progresser plus sereinement plutôt à partir de 1500 m.

Qualité de la neige :
Mercredi matin on trouvera une petite couche de neige fraîche au-dessus d'une neige récente qui aura commencé à s'humidifier sous 1700m/1800m. En altitude, l'enneigement et la qualité de la neige seront hétérogènes sous l'action du vent soufflant depuis samedi, avec des zones d'accumulations où la neige fraîche et/ou récente reste localement légère et des zones proches des crêtes Ouest à Nord-Ouest pelées ou en neige dure, voire glacée.

Aperçu météo pour le mercredi 01 avril

	nuit	matin	après-midi	soir
Temps hivernal				
Pluie-Neige	1 200 m	1 100 m	1 300 m	1 300 m
Iso 0 °C	1 500 m	1 400 m	1 700 m	1 600 m
Vent 2000 m	↓ 50 km/h	↓ 50 km/h	↓ 60 km/h	↓ 70 km/h
Vent 3000 m	↻ 75 km/h	↓ 75 km/h	↓ 85 km/h	↓ 85 km/h

Épaisseur de neige hors-piste

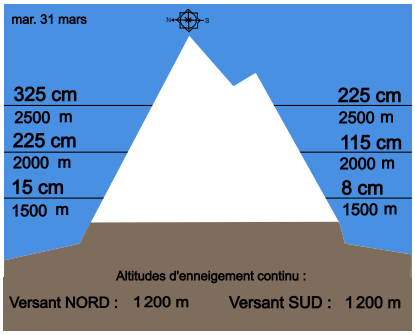

Précipitations à 1800 m

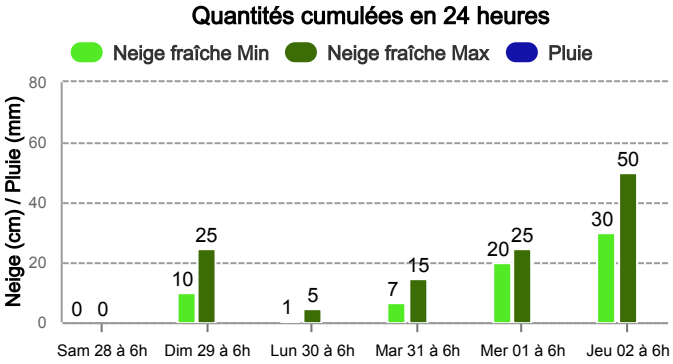

Tendance du jeudi 02 avril

Indice de risque fort

Maintien d'un risque fort avec de nouvelles chutes de neige et un manteau encore peu stabilisé

Pour consulter la vigilance en cours, veuillez vous rendre sur le site https://vigilance.meteofrance.fr/fr

Météo-France - 73 avenue de Paris, 94165 Saint-Mandé cedex - Contact : contact@meteo.fr

Rédigé par Météo-France avec la contribution des observateurs du réseau nivo-météorologiques. Partenariat : ANMSM (Maires de Stations de Montagne), DSF (Domaines Skiables de France), ADSP (Directeurs de Pistes et de la Sécurité des Stations de Sports d'Hiver) et autres acteurs de la montagne.

Bulletin neige & avalanches par téléphone au
0 892 68 10 20 Service 0,35 € / min + prix appel

RÉPUBLIQUE FRANÇAISE
Liberté Égalité Fraternité

METEO FRANCE
À VOS CÔTÉS, DANS UN CLIMAT QUI CHANGE

Bulletin d'estimation du risque d'avalanche

(valable en dehors des pistes balisées et ouvertes)

MASSIF : Haute-Ariege

Rédigé le mardi 31 mars 2026 à 16h

Conditions nivo-météo des 7 derniers jours

	mer. 25/03				jeu. 26/03				ven. 27/03				sam. 28/03				dim. 29/03				lun. 30/03				mar. 31/03			
	03h	09h	15h	21h	03h	09h	15h	21h	03h	09h	15h	21h	03h	09h	15h	21h	03h	09h	15h	21h	03h	09h	15h	21h	03h	09h	15h	21h
Météo																												
Vent (km/h)	30	35	45	75	85	85	80	75	80	80	65	45	40	45	70	90	100	100	85	65	60	60	65	70	70	65	70	75
à 3000m																												
Vent (km/h)	10	15	30	45	55	50	50	45	50	50	40	20	20	20	30	60	80	80	50	45	35	30	45	50	45	40	50	55
à 2000m																												

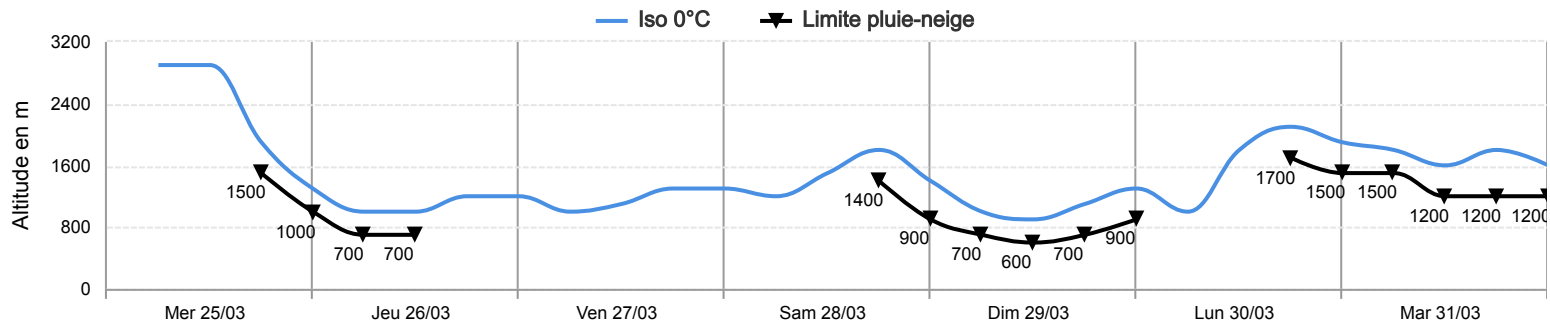

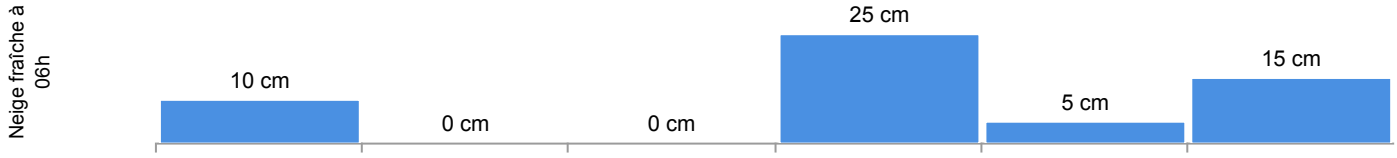

Risque d'avalanche	mer. 25/03	jeu. 26/03	ven. 27/03	sam. 28/03	dim. 29/03	lun. 30/03	mar. 31/03
	2	2	2	2	3	3	3

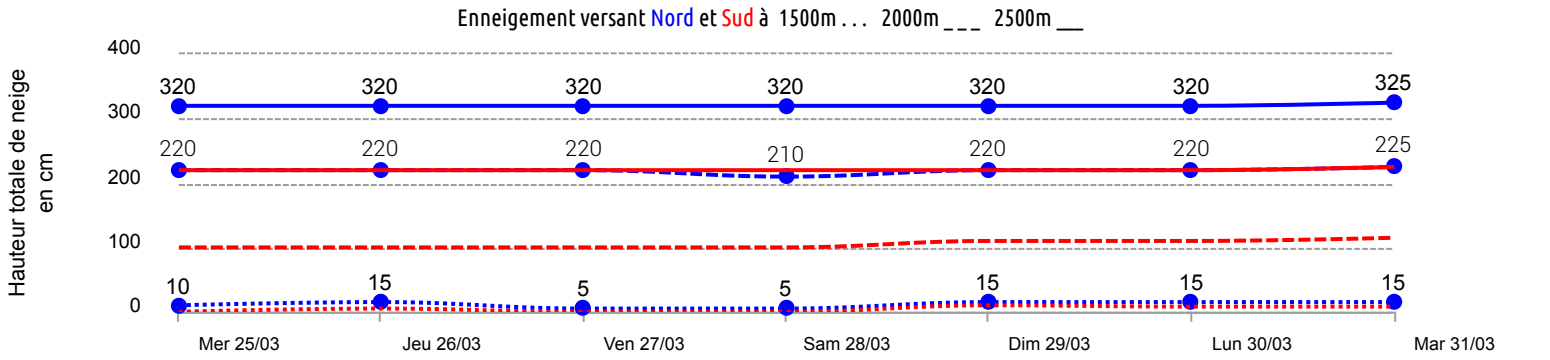

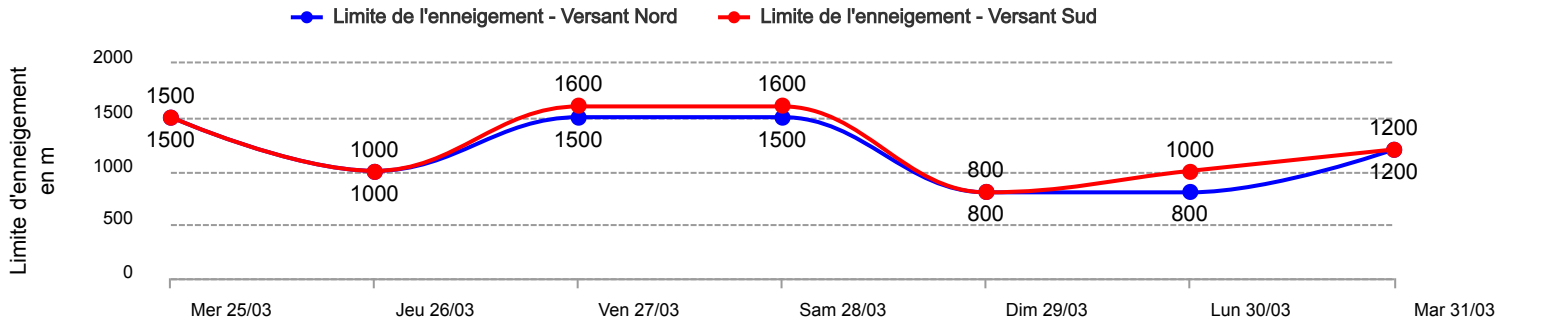

Pour consulter la vigilance en cours, veuillez vous rendre sur le site https://vigilance.meteofrance.fr/fr

Météo-France - 73 avenue de Paris, 94165 Saint-Mandé cedex - Contact : contact@meteo.fr

Bulletin neige & avalanches par téléphone au

0 892 68 10 20 Service 0,35 € / min + prix appel

Rédigé par Météo-France avec la contribution des observateurs du réseau nivo-météorologiques. Partenariat : ANMSM (Maires de Stations de Montagne), DSF (Domaines Skiables de France), ADSP (Directeurs de Pistes et de la Sécurité des Stations de Sports d'Hiver) et autres acteurs de la montagne.