Bulletin d'estimation du risque d'avalanche

(valable en dehors des pistes balisées et ouvertes)

MASSIF : Haute-Bigorre

Rédigé le mardi 31 mars 2026 à 16h

Estimation des risques pour le : MERCREDI 01 AVRIL

CHUTES DE NEIGE MARQUÉES, FORMATION DE PLAQUES ÉPAISSES EN ALTITUDE REPOSANT SUR UN MANTEAU NEIGEUX INSTABLE.

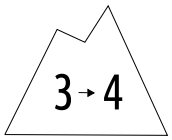

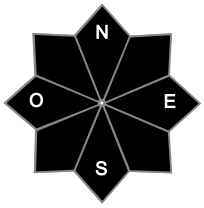

Indice de risque marqué évoluant en fort.

Départs spontanés : Nombreux départs ponctuels en pentes raides au fil des chutes de neige.

Déclenchements provoqués : Formations de plaques épaisses, reposant sur un manteau neigeux instable au-dessus de 2200m.

Indices de risque : 5 très fort - 4 fort - 3 marqué - 2 limité - 1 faible -- En noir : les pentes les plus dangereuses

Stabilité du manteau neigeux

Situation avalancheuse typique : neige fraîche

Déclenchements provoqués :
Au-dessus de 2200m, des plaques à vent se forment au fil des chutes de neige de ce mercredi dans les pentes raides préférentiellement à l'abri du vent de Nord à Nord-Est (large secteur Sud, en y ajoutant l'Ouest et l'Est). Ces plaques à vent sont de plus en plus épaisses au fil de chutes de neige et sont aussi susceptibles de se trouver dans les autres versants avec du vent fort de Nord à Nord-Est. Elles viennent reposer sur des plaques déjà formées la veille et en place mercredi matin, masquant elles-mêmes les accumulations du week-end qui ne sont pas encore totalement stabilisées. Un simple skieur peut ainsi facilement solliciter ces plaques, et ainsi engendrer des avalanches moyennes à grandes dès la matinée (taille 2 à 3), parfois même de très grandes avalanches (taille 4) au fil des chutes de neige de la journée et dans les zones d'accumulation importantes.
Sous 2200m, les plaques en cours de formation viennent reposer sur les plaques de la veille déjà en place le matin, elles-mêmes reposant sur un manteau dur à regelé. Elles sont aussi facilement déclenchables par un simple skieur, engendrant des cassures linéaires moyennes à grandes (taille 2 à 3) au fil des chutes de neige et de la journée.

Départs spontanés :
Avec les chutes de neige attendues, des avalanches moyennes à grandes sont attendues dès mercredi matin en tous versants raides. Au fur et à mesure des chutes de neige de la journée, les cumuls de neige augmentent nettement, donnant lieu à de nombreuses avalanches de tailles moyennes à grandes (taille 2 à 3), voire de très grandes avalanches (taille 4), notamment en partant de couloirs très chargés ou de zones d'accumulation raides à l'abri du vent de Nord, donc plutôt des secteurs Nord-Est à Sud-Ouest.
Il est aussi possible d'avoir des départs ponctuels des plaques décrites ci-dessus, **au-dessus de 2200m,** par surcharge par le vent, engendrant des avalanches moyennes à grandes (taille 2 à 3), parfois même de très grandes avalanches (taille 4) au fil des chutes de neige de la journée.

Qualité de la neige

Enneigement : Correct pour la saison au-dessus de 1800m, mais restant assez maigre en versants exposés aux vents de nord à ouest. Chutes de neige importantes attendues ce mercredi, poursuivant celles de mardi, les cumuls de neige vont nettement augmenter au fil de la journée. Des centimètres de neige supplémentaires sont attendues dès 1300m ce mercredi.
État de la neige : Mercredi matin, plusieurs centimètres de neige fraîche datant de la veille et de la nuit. Cette couche de neige s'épaissit considérablement au fil des chutes de neige de la journée, recouvrant un manteau neigeux en général printanier sous 2000m, bien regelé. Plus haut, la neige fraîche est de plus en plus travaillée par le vent de Nord, alternant surface dures pelées par le vent et accumulations plus meubles.

Aperçu météo pour le mercredi 01 avril

	nuit	matin	après-midi	soir

Chutes de neige fréquentes en journée avec des cumuls importants, du vent de Nord fort en altitude, de la neige dès 1300m environ.

	nuit	matin	après-midi	soir
Pluie-Neige	1 300 m	1 300 m	1 500 m	1 200 m
Iso 0 °C	1 600 m	1 700 m	1 600 m	1 400 m
Vent 2000 m	↓ 40 km/h	↓ 40 km/h	↓ 45 km/h	↓ 60 km/h
Vent 3000 m	↓ 75 km/h	↓ 80 km/h	↓ 85 km/h	↓ 90 km/h

Épaisseur de neige hors-piste

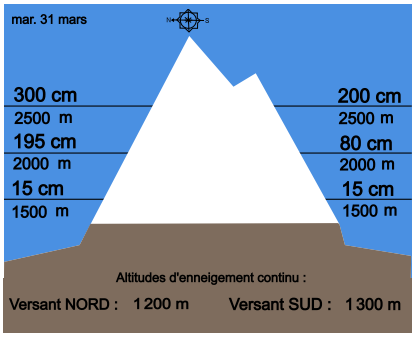

Précipitations à 1800 m

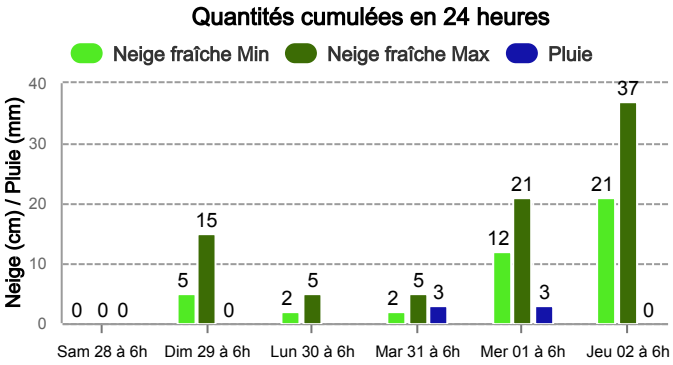

Tendance du jeudi 02 avril

Indice de risque fort

Maintien d'un risque fort dans une ambiance encore ventée de Nord. Nouvelles chutes de neige à venir.

Pour consulter la vigilance en cours, veuillez vous rendre sur le site https://vigilance.meteofrance.fr/fr

Météo-France - 73 avenue de Paris, 94165 Saint-Mandé cedex - Contact : contact@meteo.fr

Rédigé par Météo-France avec la contribution des observateurs du réseau nivo-météorologiques. Partenariat : ANMSM (Maires de Stations de Montagne), DSF (Domaines Skiables de France), ADSP (Directeurs de Pistes et de la Sécurité des Stations de Sports d'Hiver) et autres acteurs de la montagne.

Bulletin neige & avalanches par téléphone au **0 892 68 10 20** Service 0,35 € / min + prix appel

RÉPUBLIQUE FRANÇAISE
Liberté Égalité Fraternité

METEO FRANCE
À VOS CÔTÉS, DANS UN CLIMAT QUI CHANGE

Bulletin d'estimation du risque d'avalanche

(valable en dehors des pistes balisées et ouvertes)

MASSIF : Haute-Bigorre

Rédigé le mardi 31 mars 2026 à 16h

Conditions nivo-météo des 7 derniers jours

	mer. 25/03				jeu. 26/03				ven. 27/03				sam. 28/03				dim. 29/03				lun. 30/03				mar. 31/03			
	03h	09h	15h	21h	03h	09h	15h	21h	03h	09h	15h	21h	03h	09h	15h	21h	03h	09h	15h	21h	03h	09h	15h	21h	03h	09h	15h	21h
Météo																												
Vent (km/h)	70	70	75	80	90	80	75	80	70	70	65	50	45	55	60	85	90	105	85	75	65	70	75	80	70	70	70	90
à 3000m																												
Vent (km/h)	15	10	25	35	35	30	20	30	25	25	25	15	15	20	30	55	65	70	60	40	25	25	35	40	35	35	35	45
à 2000m																												

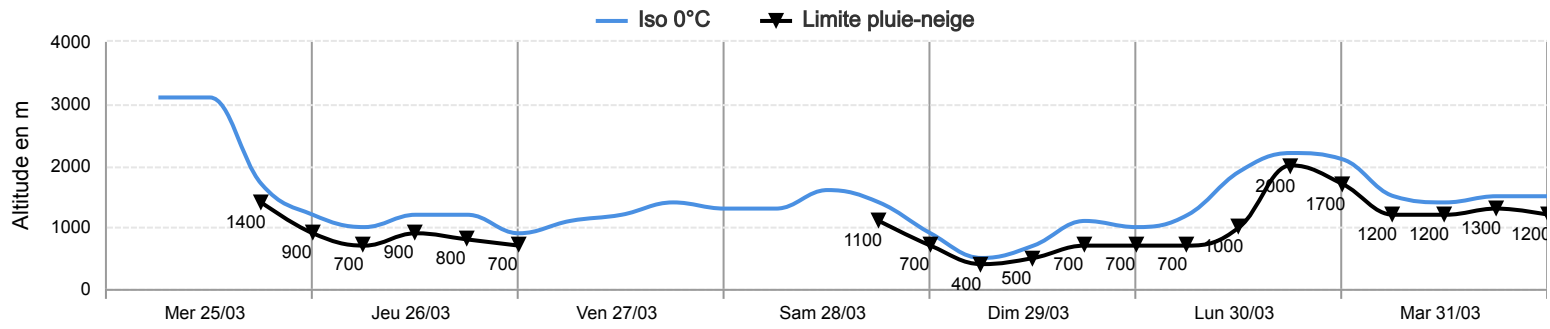

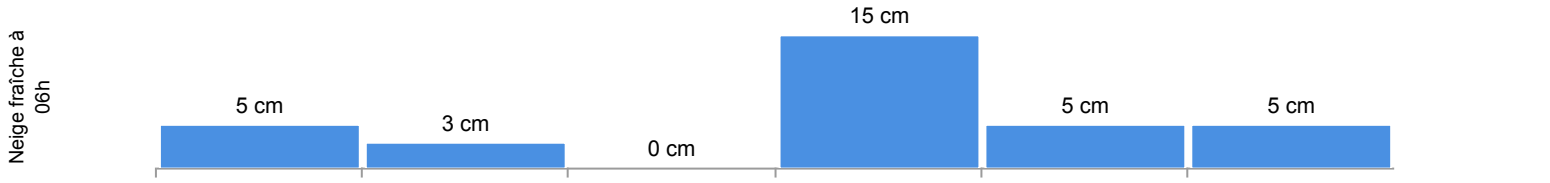

Risque d'avalanche	mer. 25/03	jeu. 26/03	ven. 27/03	sam. 28/03	dim. 29/03	lun. 30/03	mar. 31/03
	2	2	2	2	3	3	3

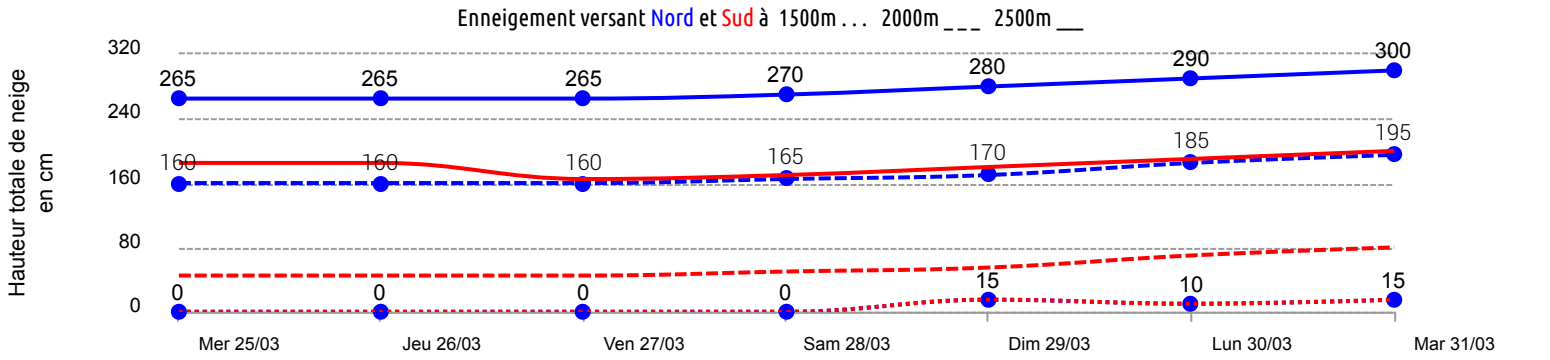

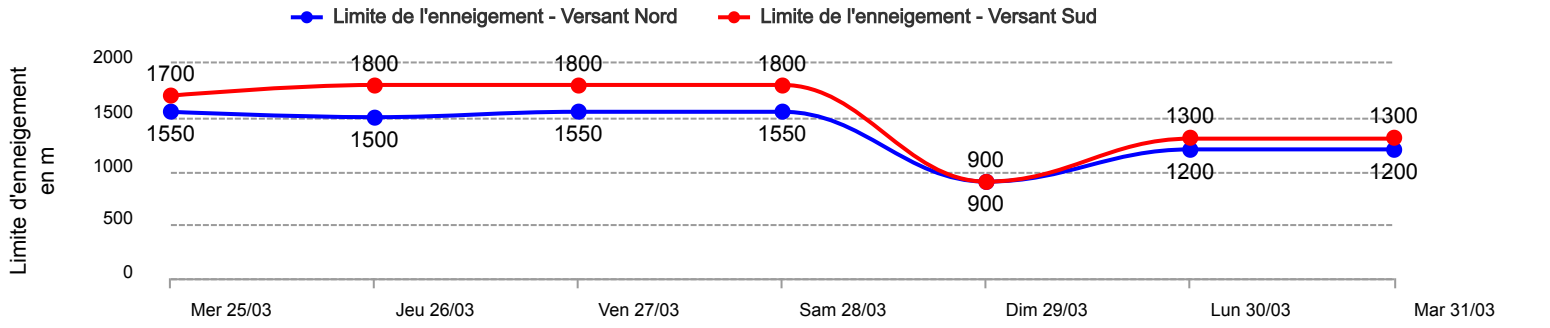

Pour consulter la vigilance en cours, veuillez vous rendre sur le site https://vigilance.meteofrance.fr/fr

Météo-France - 73 avenue de Paris, 94165 Saint-Mandé cedex - Contact : contact@meteo.fr

Rédigé par Météo-France avec la contribution des observateurs du réseau nivo-météorologiques. Partenariat : ANMSM (Maires de Stations de Montagne), DSF (Domaines Skiables de France), ADSP (Directeurs de Pistes et de la Sécurité des Stations de Sports d'Hiver) et autres acteurs de la montagne.

Bulletin neige & avalanches par téléphone au
0 892 68 10 20 Service 0,35 € / min + prix appel