Bulletin d'estimation du risque d'avalanche

(valable en dehors des pistes balisées et ouvertes)

MASSIF : Haute-Tarentaise

Rédigé le mardi 31 mars 2026 à 16h

Estimation des risques pour le : MERCREDI 01 AVRIL

MANTEAU ENCORE HIVERNAL, PORTANT LES STIGMATES DU VENT.

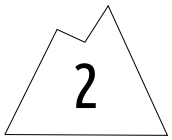

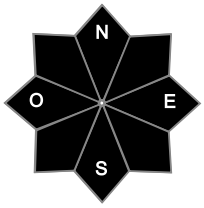

Indice de risque limité.

Départs spontanés : petites coulées au soleil.

Déclenchements provoqués : quelques plaques encore sensibles, surtout au moyennes altitudes.

Indices de risque : 5 très fort - 4 fort - 3 marqué - 2 limité - 1 faible -- En noir : les pentes les plus dangereuses

Stabilité du manteau neigeux

Situation avalancheuse typique : neige ventée

Déclenchements provoqués : Quelques plaques sont en place, formées par le vent de secteur Nord-Ouest à Nord-Est ces dernier jours. Leur neutralisation est en cours mais elles sont encore localement réactives, surtout là où le vent a tardé à se calmer. On les trouve dans les **zones d'accumulation** sous le vent (croupes, ruptures de pente), **plutôt loin des crêtes et jusqu'en bas des versants**. Elles sont plus fréquentes entre ~2200 m (limite haute des arbres) et ~3200 m (la haute montagne est souvent pelée mais on peut trouver de profondes accumulations), ainsi que dans les versants Sud-Ouest à Est (et Nord dans une moindre mesure). Les cassures atteignent 30 à 50 cm (localement 80 cm en altitude), pour des avalanches peu larges, de taille 1 à 2 (petite à moyenne).

Départs spontanés : Quelques petites coulées sont attendues dans les pentes raides avec l'humidification de la neige fraîche par le soleil. Taille 1.

Qualité de la neige

Enneigement : un peu au dessus de la moyenne, ces derniers jours hivernaux retardent quelques peu l'inéluctable fonte printanière.

Limite skiable : vers 1300 m en Nord, 1600 m en Sud.

Qualité de la neige : couche de neige fraîche rendue très hétérogène par le vent : en moyenne ~10/15 cm vers 2000 m, parfois rien et l'ancienne neige est en surface, parfois plus du double dans les trous, qu'il faut viser pour faire du bon ski. Généralement densifiée par le vent, et même cartonnée à durcie près des crêtes (où les cailloux ressortent). Seules les zones très abritées ou boisées sont encore en poudre légère. Une croute peut-être présente en Sud à Ouest.

Aperçu météo pour le mercredi 01 avril

nuit	matin	après-midi	soir

Beau le matin, nombreux nuages sur le relief l'après-midi. Vent faiblissant.

Pluie-Neige				
Iso 0 °C	1 300 m	1 600 m	1 900 m	1 500 m
Vent 2500 m	↙ 30 km/h	↙ 15 km/h	↓ 10 km/h	← 15 km/h
Vent 3500 m	↙ 50 km/h	↙ 30 km/h	← 20 km/h	← 30 km/h

Épaisseur de neige hors-piste

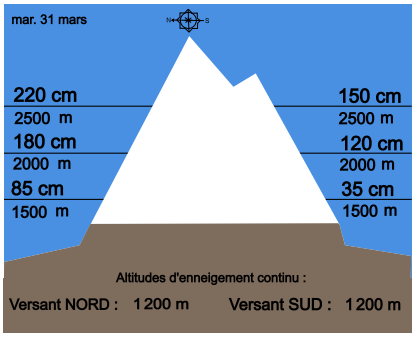

Précipitations à 1800 m

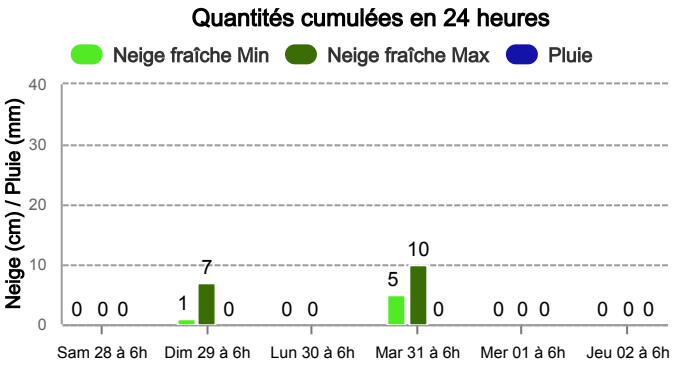

Tendance du jeudi 02 avril

Indice de risque limité

Le temps reste frais et calme, permettant la neutralisation progressive des instabilités.

Pour consulter la vigilance en cours, veuillez vous rendre sur le site https://vigilance.meteofrance.fr/fr

Météo-France - 73 avenue de Paris, 94165 Saint-Mandé cedex - Contact : contact@meteo.fr

Rédigé par Météo-France avec la contribution des observateurs du réseau nivo-météorologiques. Partenariat : ANMSM (Maires de Stations de Montagne), DSF (Domaines Skiables de France), ADSP (Directeurs de Pistes et de la Sécurité des Stations de Sports d'Hiver) et autres acteurs de la montagne.

Bulletin neige & avalanches par téléphone au 0 892 68 10 20 Service 0,35 € / min + prix appel

RÉPUBLIQUE FRANÇAISE
Liberté Égalité Fraternité

METEO FRANCE
À VOS CÔTÉS, DANS UN CLIMAT QUI CHANGE

Bulletin d'estimation du risque d'avalanche

(valable en dehors des pistes balisées et ouvertes)

MASSIF : Haute-Tarentaise

Rédigé le mardi 31 mars 2026 à 16h

Conditions nivo-météo des 7 derniers jours

	mer. 25/03				jeu. 26/03				ven. 27/03				sam. 28/03				dim. 29/03				lun. 30/03				mar. 31/03			
	03h	09h	15h	21h	03h	09h	15h	21h	03h	09h	15h	21h	03h	09h	15h	21h	03h	09h	15h	21h	03h	09h	15h	21h	03h	09h	15h	21h
Météo																												
Vent (km/h)	50	65	85	95	95	85	80	75	60	50	30	30	30	40	40	30	25	25	20	20	30	65	70	75	80	50	45	50
à 3500m																												
Vent (km/h)	25	45	70	85	85	75	70	65	40	30	20	20	20	30	30	20	20	20	15	15	15	30	55	60	50	30	30	35
à 2500m																												

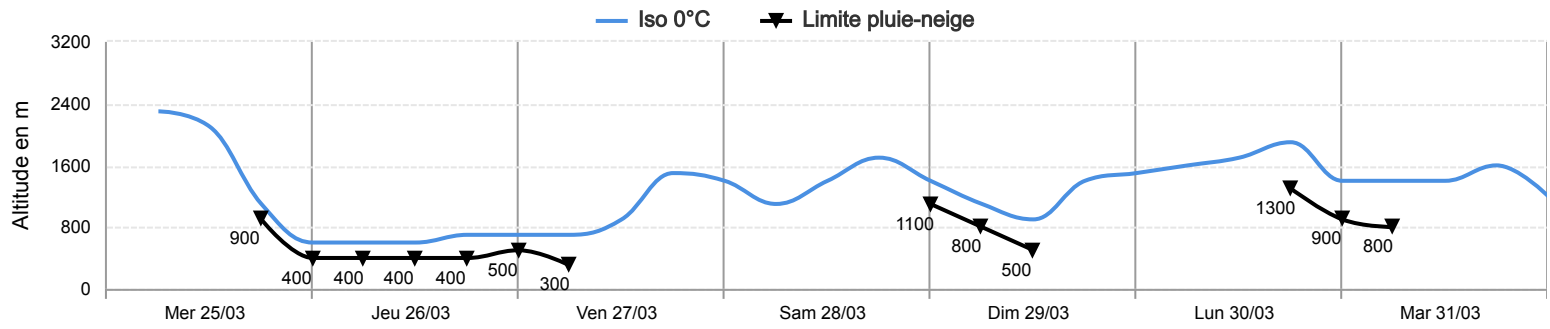

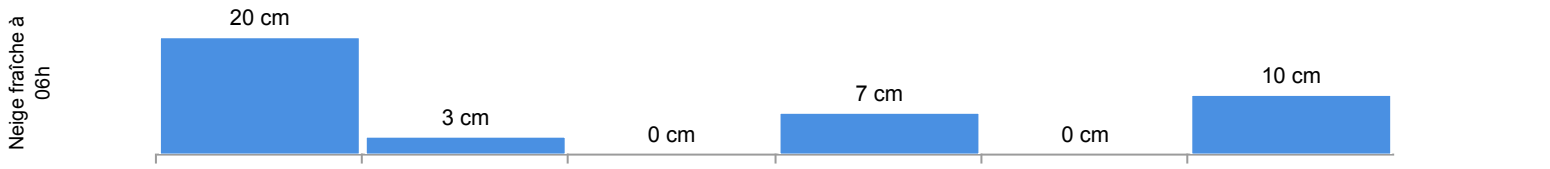

Risque d'avalanche	mer. 25/03	jeu. 26/03	ven. 27/03	sam. 28/03	dim. 29/03	lun. 30/03	mar. 31/03
	3	3	3	2	2	2	3

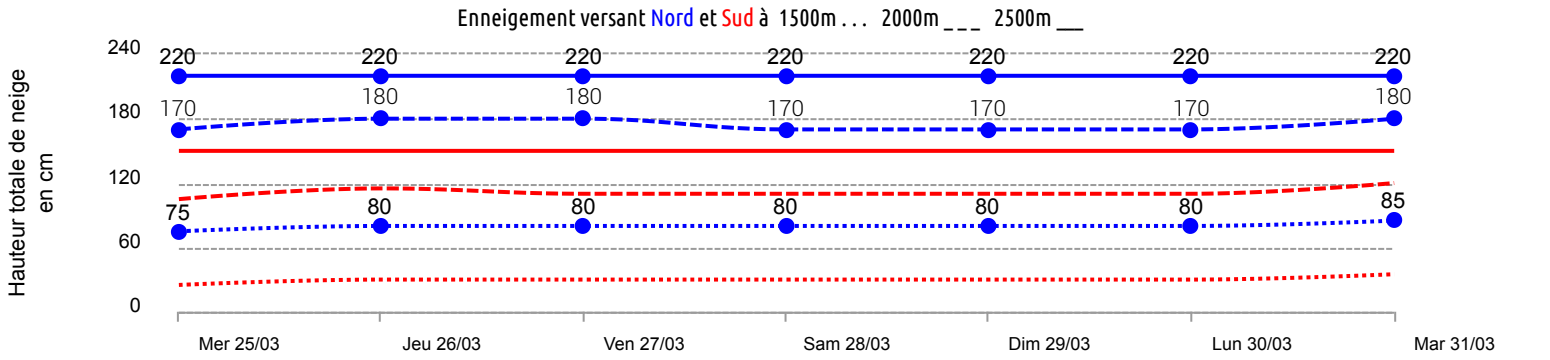

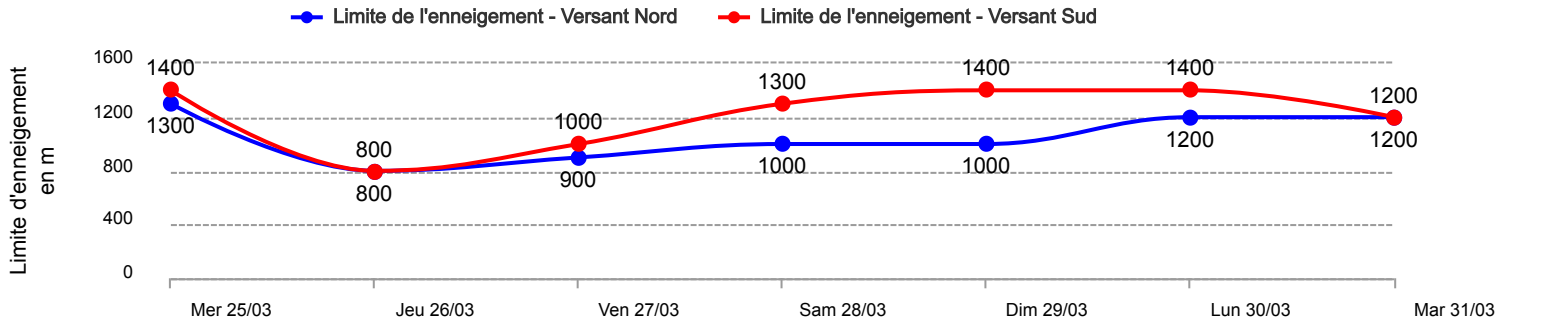

Pour consulter la vigilance en cours, veuillez vous rendre sur le site https://vigilance.meteofrance.fr/fr

Météo-France - 73 avenue de Paris, 94165 Saint-Mandé cedex - Contact : contact@meteo.fr

Rédigé par Météo-France avec la contribution des observateurs du réseau nivo-météorologiques. Partenariat : ANMSM (Maires de Stations de Montagne), DSF (Domaines Skiables de France), ADSP (Directeurs de Pistes et de la Sécurité des Stations de Sports d'Hiver) et autres acteurs de la montagne.

Bulletin neige & avalanches par téléphone au
0 892 68 10 20 Service 0,35 € / min + prix appel