Bulletin d'estimation du risque d'avalanche
(valable en dehors des pistes balisées et ouvertes)

MASSIF : Mercantour

Rédigé le mardi 31 mars 2026 à 16h

Estimation des risques pour le : MERCREDI 01 AVRIL

RARES INSTABILITÉS EN ALTITUDE DANS LA NEIGE VENTÉE

2

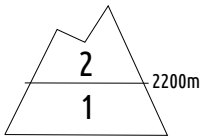

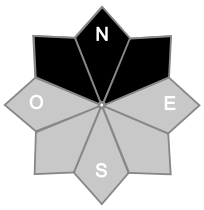

Au-dessus de 2200m indice de risque limité, plus bas indice faible.

Départs spontanés : rares départs en altitude

Déclenchements provoqués : rares plaques à vent en altitude

Indices de risque : 5 très fort - 4 fort - 3 marqué - 2 limité - 1 faible -- En noir : les pentes les plus dangereuses

Stabilité du manteau neigeux

Situation avalancheuse typique : neige ventée

Déclenchements provoqués : instabilités limitées à de rares pentes d'altitude, entretenues par le transport de la neige encore mobilisable par le vent. Possibles surtout en versants de large nord au-dessus de 2200/2400 m environ, plutôt loin des crêtes. Ces plaques à vent sont généralement bien identifiables. Un skieur peut encore les déclencher, générant une avalanche de petite taille, rarement moyenne.

Départs spontanés : rares départs spontanés, restants peu volumineux, en pente raide dans les secteurs d'accumulation de la neige par le vent en altitude. Taille généralement petite.

Qualité de la neige

Enneigement plutôt excédentaire pour une fin mars.
Hauteurs de neige observées : 152 cm à la nivose de Millefonts à 2430 m, 103 cm à Isola 2000 à 1912 m.

Enneigement skiable : vers 1400/1500 m en terrain favorable en ubacs, 1800/1900 m en adrets peu pentus.

État de la neige en surface : manteau neigeux souvent dur/regelé en adrets, durcis par le vent en ubacs d'altitude. On retrouve localement un peu de neige légère en surface dans les combes nord bien abritées du vent. Pas ou peu d'humidification au soleil en journée.

Aperçu météo pour le mercredi 01 avril

nuit	matin	après-midi	soir

Ambiance restant fraiche et ventée. L'après-midi sur la frontière italiene les nuages s'imposent, quelques flocons, ailleurs le soleil continue de briller.

Pluie-Neige				
Iso 0 °C	1 000 m	1 200 m	1 400 m	1 400 m
Vent 2000 m	75 km/h	70 km/h	65 km/h	60 km/h
Vent 3000 m	110 km/h	70 km/h	65 km/h	65 km/h

Épaisseur de neige hors-piste

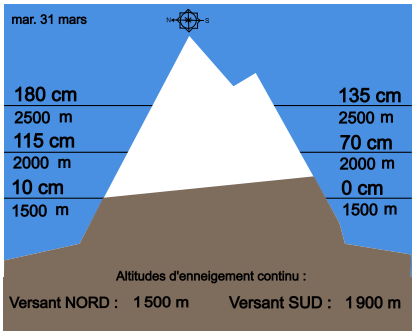

Précipitations à 1800 m

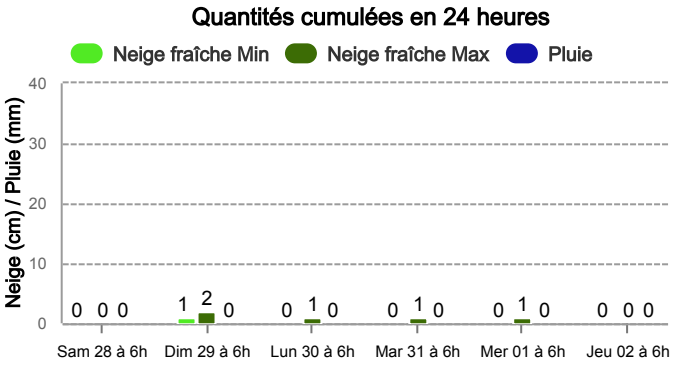

Tendance du jeudi 02 avril

2

Indice de risque limité

Peu d'évolution de la situation nivologique. De rares instabilités persistent en altitude dans la neige ventée.

Pour consulter la vigilance en cours, veuillez vous rendre sur le site https://vigilance.meteofrance.fr/fr

Météo-France - 73 avenue de Paris, 94165 Saint-Mandé cedex - Contact : contact@meteo.fr

Rédigé par Météo-France avec la contribution des observateurs du réseau nivo-météorologiques. Partenariat : ANMSM (Maires de Stations de Montagne), DSF (Domaines Skiables de France), ADSP (Directeurs de Pistes et de la Sécurité des Stations de Sports d'Hiver) et autres acteurs de la montagne.

Bulletin neige & avalanches par téléphone au 0 892 68 10 20 Service 0,35 € / min + prix appel

RÉPUBLIQUE FRANÇAISE
Liberté Égalité Fraternité

METEO FRANCE
À VOS CÔTÉS, DANS UN CLIMAT QUI CHANGE

Bulletin d'estimation du risque d'avalanche
(valable en dehors des pistes balisées et ouvertes)
MASSIF : Mercantour

Rédigé le mardi 31 mars 2026 à 16h

Conditions nivo-météo des 7 derniers jours

	mer. 25/03				jeu. 26/03				ven. 27/03				sam. 28/03				dim. 29/03				lun. 30/03				mar. 31/03			
	03h	09h	15h	21h	03h	09h	15h	21h	03h	09h	15h	21h	03h	09h	15h	21h	03h	09h	15h	21h	03h	09h	15h	21h	03h	09h	15h	21h
Météo																												
Vent (km/h)	30	40	70	100	100	80	70	60	55	50	40	30	25	25	25	25	40	35	35	15	40	50	80	95	65	60	90	100
à 3000m																												
Vent (km/h)	10	20	50	80	80	65	65	60	60	65	40	25	10	15	20	20	30	30	20	10	25	20	40	55	40	50	60	65
à 2000m																												

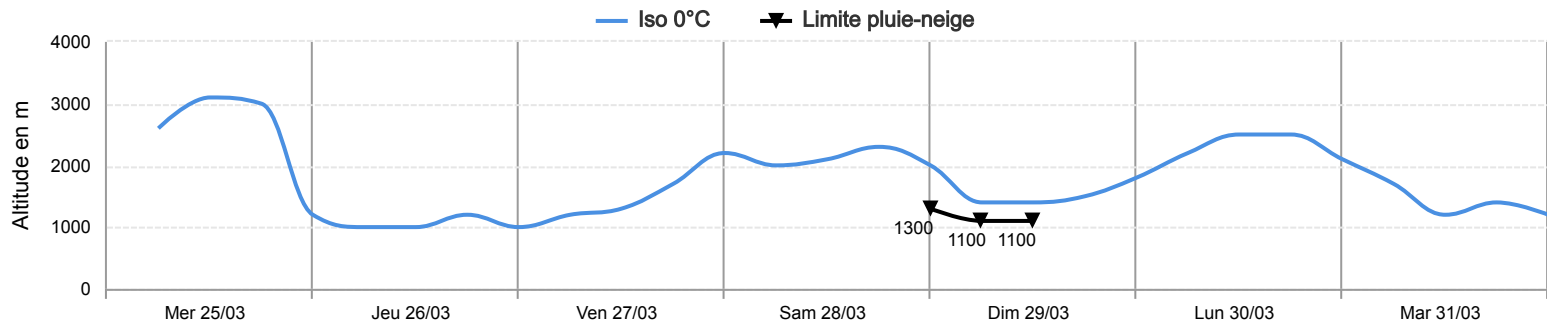

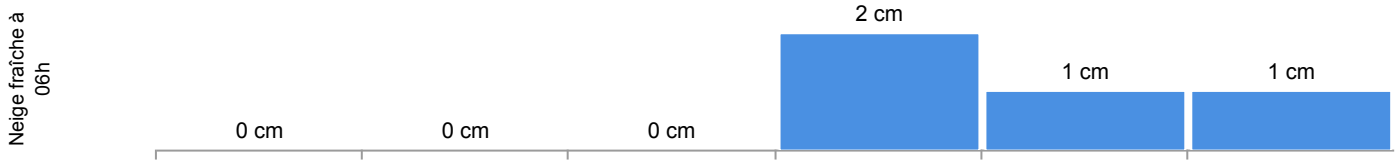

Risque d'avalanche	mer. 25/03	jeu. 26/03	ven. 27/03	sam. 28/03	dim. 29/03	lun. 30/03	mar. 31/03
	2	3	2	2	2	2	2

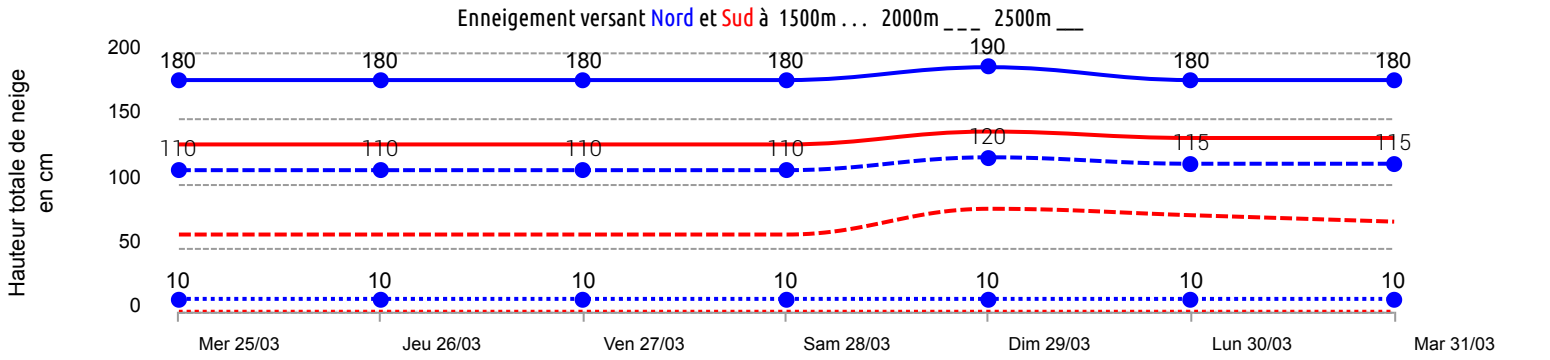

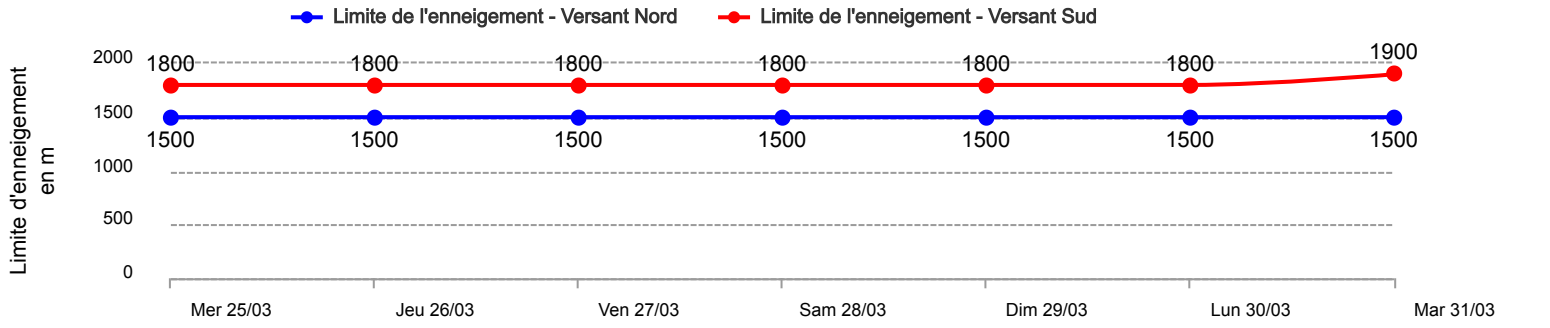

Pour consulter la vigilance en cours, veuillez vous rendre sur le site https://vigilance.meteofrance.fr/fr

Météo-France - 73 avenue de Paris, 94165 Saint-Mandé cedex - Contact : contact@meteo.fr

Rédigé par Météo-France avec la contribution des observateurs du réseau nivo-météorologiques. Partenariat : ANMSM (Maires de Stations de Montagne), DSF (Domaines Skiables de France), ADSP (Directeurs de Pistes et de la Sécurité des Stations de Sports d'Hiver) et autres acteurs de la montagne.

Bulletin neige & avalanches par téléphone au
0 892 68 10 20 Service 0,35 € / min + prix appel