Bulletin d'estimation du risque d'avalanche
(valable en dehors des pistes balisées et ouvertes)

MASSIF : Oisans

Rédigé le mardi 31 mars 2026 à 16h

Estimation des risques pour le : MERCREDI 01 AVRIL

MANTEAU HIVERNAL, AVEC DE NOMBREUSES PLAQUES SE FORMANT SOUS LE VENT EN ALTITUDE

3

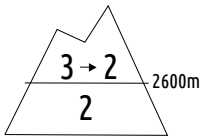

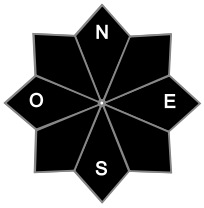

Au-dessus de 2600m indice de risque marqué évoluant en limité, plus bas indice limité.

Départs spontanés : Quelques ruptures de plaques possibles dans les pentes chargées par le vent

Déclenchements provoqués : Plaques à vent plus nombreuses en altitude, généralement peu épaisses mais réactives

Indices de risque : 5 très fort - 4 fort - 3 marqué - 2 limité - 1 faible -- En noir : les pentes les plus dangereuses

Stabilité du manteau neigeux

Situation avalancheuse typique : neige ventée

Déclenchements provoqués : De nouvelles plaques se forment encore ce mercredi sous le vent de Nord à Nord-Est, surtout au-dessus de 2600m où il est tempétueux. Ces instabilités se retrouvent même loin des crêtes / jusque dans les bas de pentes et en tout versant, mais sont de manière générale plus nombreuses en large Sud. Les plaques restent généralement peu larges et peu épaisses, mais peuvent être de plus grandes tailles sur certains secteurs où les chutes de neige de lundi ont été plus marquéess (notamment vers les Ecrins, refuge du Promontoire). Les plaques sont encore très réactives le matin, puis le manteau commence à se stabiliser l'après-midi avec l'afaiblissement du vent et l'arrêt du transport de neige.

Observables : Transport en cours, accumulation, neige sculptée par le vent.

Départs spontanés : Surtout au-dessus de 2600m, dans les pentes chargées par le vent (généralement en large Sud) quelques ruptures de plaques de tailles petites à moyennes restent possible jusqu'à la fin de l'épisode de vent, autour du milieu de journée. L'après-midi, de petites coulées sont possibles sous les rochers qui prennent le soleil, surtout à basse altitude.

Qualité de la neige

Qualification de l'enneigement : L'enneigement est bon à basse altitude, et même très bon dés 1800 / 2000m mais avec des répartitions assez hétérogènes à cause du vent. Peu de sous couche sous 1700m en plein Sud.

Limites skiables : Vers 1000 / 1200m selon le versant, avec prudence en Sud / sous les sapins

Qualité de la neige mercredi : Neige de qualité très variable sur le massif. Alternance de neige durcie / cartonnée par le vent et de zones pelées, faisant ressortir une vieille neige très dure / croûtée. Certaines lentilles de neige plus meubles sont parfois présentes (souvent synonyme de plaques). Les crêtes et pentes exposées au vent de Nord sont souvent dégarnie. En versants Sud, dans certaines combes abritées et en bas de pentes / secteurs forestiers, la neige est parfois restée poudreuse, avec encore du bon ski par endroits.

Aperçu météo pour le mercredi 01 avril

nuit	matin	après-midi	soir

Ciel assez dégagé en matinée, avec quelques nuages près des sommets, sous un vent de Nord-Est encore tempétueux. L'après-midi les nuages bourgeonnent, accrochant les sommets, sous un vent plus faible.

Pluie-Neige				
Iso 0 °C	1 300 m	1 500 m	1 900 m	1 400 m
Vent 2500 m	↓ 60 km/h	↓ 50 km/h	← 25 km/h	← 20 km/h
Vent 3500 m	↙ 85 km/h	↙ 75 km/h	← 40 km/h	← 40 km/h

Épaisseur de neige hors-piste

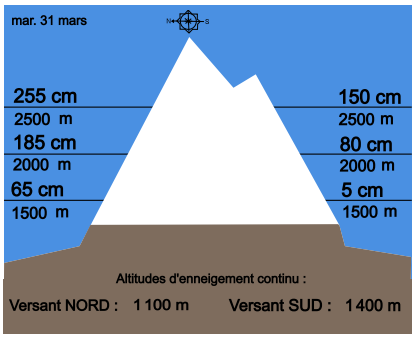

Précipitations à 1800 m

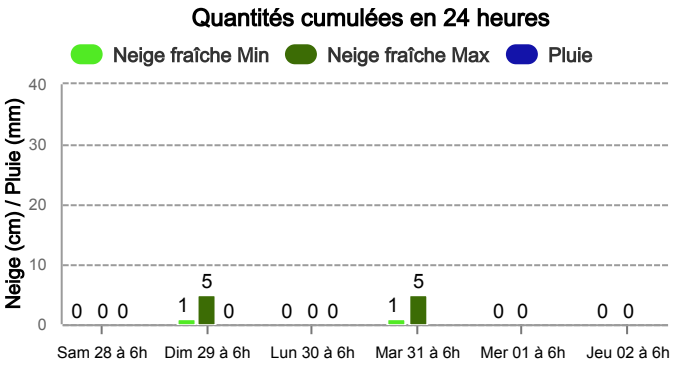

Tendance du jeudi 02 avril

2

Indice de risque limité

Jeudi, risque limité. Les quelques plaques présentes en altitude poursuivent leur stabilisation.

Pour consulter la vigilance en cours, veuillez vous rendre sur le site https://vigilance.meteofrance.fr/fr

Météo-France - 73 avenue de Paris, 94165 Saint-Mandé cedex - Contact : contact@meteo.fr

Rédigé par Météo-France avec la contribution des observateurs du réseau nivo-météorologiques. Partenariat : ANMSM (Maires de Stations de Montagne), DSF (Domaines Skiables de France), ADSP (Directeurs de Pistes et de la Sécurité des Stations de Sports d'Hiver) et autres acteurs de la montagne.

Bulletin neige & avalanches par téléphone au

0 892 68 10 20 Service 0,35 € / min + prix appel

RÉPUBLIQUE FRANÇAISE
Liberté Égalité Fraternité

METEO FRANCE
À VOS CÔTÉS, DANS UN CLIMAT QUI CHANGE

Bulletin d'estimation du risque d'avalanche

(valable en dehors des pistes balisées et ouvertes)

MASSIF : Oisans

Rédigé le mardi 31 mars 2026 à 16h

Conditions nivo-météo des 7 derniers jours

	mer. 25/03				jeu. 26/03				ven. 27/03				sam. 28/03				dim. 29/03				lun. 30/03				mar. 31/03			
	03h	09h	15h	21h	03h	09h	15h	21h	03h	09h	15h	21h	03h	09h	15h	21h	03h	09h	15h	21h	03h	09h	15h	21h	03h	09h	15h	21h
Météo																												
Vent (km/h)	15	60	85	100	100	85	85	100	80	70	50	40	55	50	55	55	50	35	30	25	50	80	95	105	120	120	110	100
à 3500m																												
Vent (km/h)	10	40	75	75	70	70	70	75	65	50	40	25	40	45	50	50	45	30	25	20	35	65	70	85	85	90	80	80
à 2500m																												

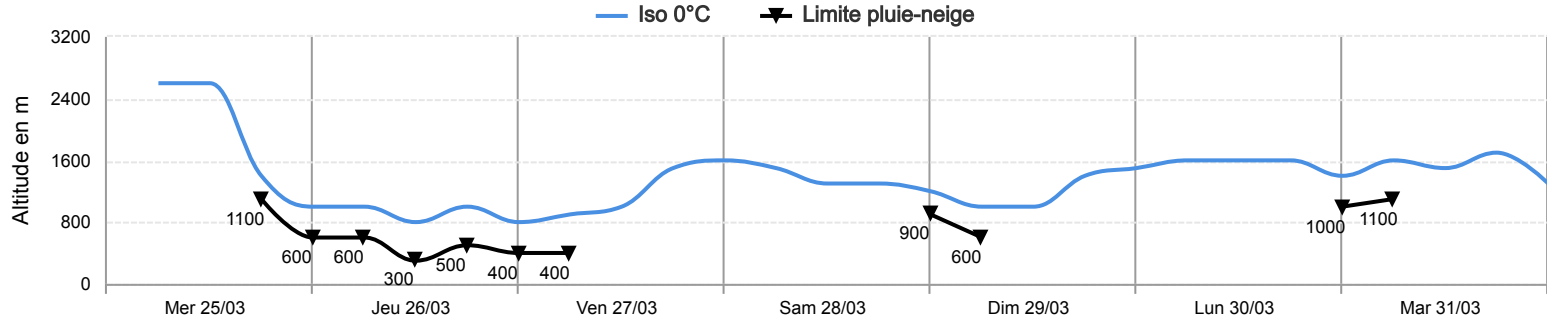

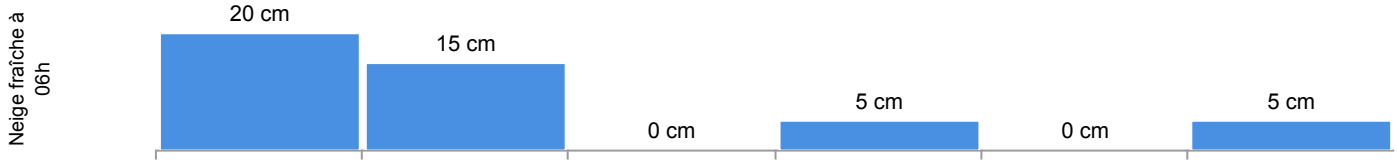

Risque d'avalanche	mer. 25/03	jeu. 26/03	ven. 27/03	sam. 28/03	dim. 29/03	lun. 30/03	mar. 31/03
	3	4	3	2	2	2	2

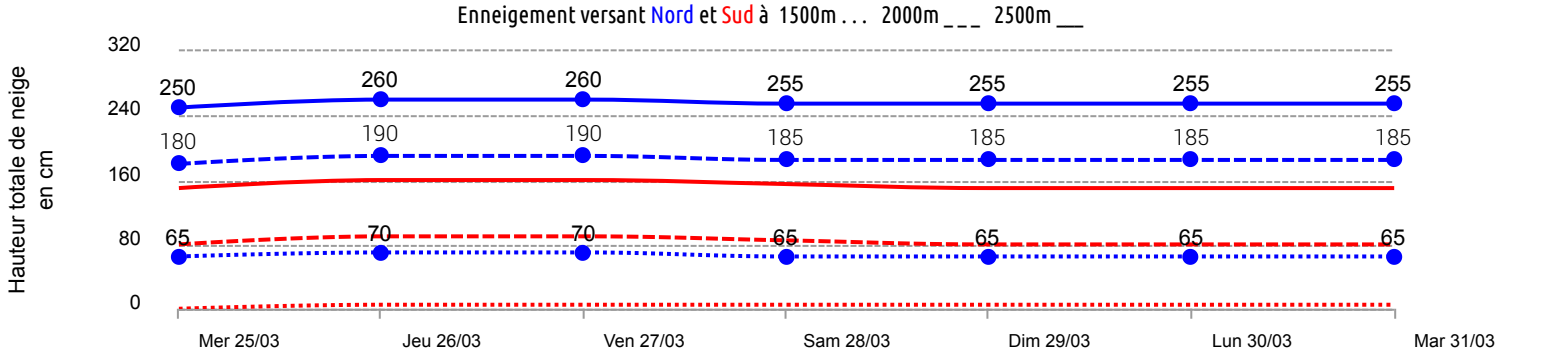

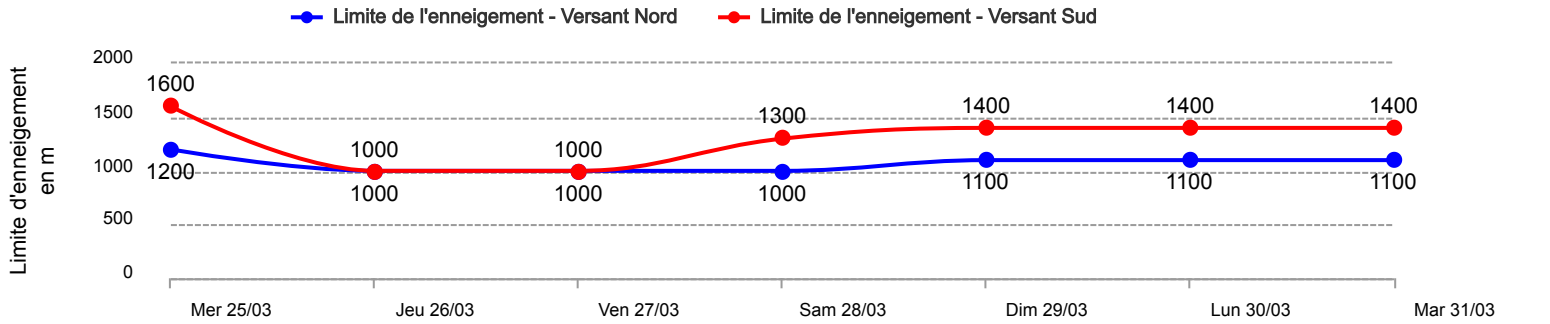

Pour consulter la vigilance en cours, veuillez vous rendre sur le site https://vigilance.meteofrance.fr/fr

Météo-France - 73 avenue de Paris, 94165 Saint-Mandé cedex - Contact : contact@meteo.fr

Bulletin neige & avalanches par téléphone au

0 892 68 10 20 Service 0,35 € / min + prix appel

Rédigé par Météo-France avec la contribution des observateurs du réseau nivo-météorologiques. Partenariat : ANMSM (Maires de Stations de Montagne), DSF (Domaines Skiables de France), ADSP (Directeurs de Pistes et de la Sécurité des Stations de Sports d'Hiver) et autres acteurs de la montagne.