Bulletin d'estimation du risque d'avalanche

(valable en dehors des pistes balisées et ouvertes)

MASSIF : Pays-Basque

Rédigé le mardi 31 mars 2026 à 16h

Estimation des risques pour le : MERCREDI 01 AVRIL

CHUTES DE NEIGE MARQUÉES, FORMATION DE PLAQUES ÉPAISSES EN ALTITUDE.

3

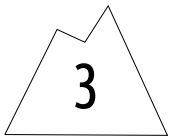

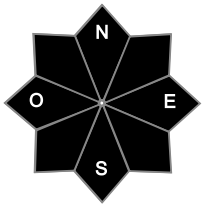

Indice de risque marqué.

Départs spontanés : Départs ponctuels en pentes raides au fil des chutes de neige.

Déclenchements provoqués : Formation de plaques épaisses.

Indices de risque : 5 très fort - 4 fort - 3 marqué - 2 limité - 1 faible -- En noir : les pentes les plus dangereuses

Stabilité du manteau neigeux

Situation avalancheuse typique : neige fraîche

Déclenchements provoqués :
Des plaques à vent se forment au fil des chutes de neige de ce mercredi dans les pentes raides préférentiellement à l'abri du vent de Nord à Nord-Est (large secteur Sud, en y ajoutant l'Ouest et l'Est). Ces plaques à vent sont de plus en plus épaisses au fil de chutes de neige et sont aussi susceptibles de se trouver dans les autres versants avec du vent fort de Nord à Nord-Est. Elles viennent reposer sur des plaques déjà formées la veille et en place mercredi matin, elles-mêmes reposant sur un manteau dur à regelé. Elles sont facilement déclenchables par un simple skieur, engendrant des cassures linéaires moyennes, voire des grandes (taille 2 à 3) au fil des chutes de neige de la journée.

Départs spontanés :
Avec les chutes de neige attendues, des avalanches moyennes à parfois grandes (taille 2 à 3) sont attendues dès mercredi matin en tous versants raides. Au fil des chutes de neige et de la journée, les cumuls de neige seront de plus en plus importants, les grandes avalanches (taille 3) pourraient être ainsi plus nombreuses et plus récurrentes, se trouvant notamment en partant de couloirs très chargés ou de zones d'accumulation raides à l'abri du vent de Nord, donc plutôt des secteurs Nord-Est à Sud-Ouest.
Il est aussi possible d'avoir des départs ponctuels des plaques décrites ci-dessus, par surcharge par le vent, engendrant des avalanches moyennes à parfois grandes (taille 2 à 3) en matinée, même si les grandes avalanches restent plus probables en journée au fil des chutes de neige.

Qualité de la neige

Enneigement : Correct pour la saison au-dessus de 1800m, mais restant assez maigre en versants exposés au vent d'ouest. Chutes de neige importantes attendues ce mercredi, poursuivant celles de mardi, les cumuls de neige vont nettement augmenter au fil de la journée. Des centimètres de neige supplémentaires sont attendues dès 1300m ce mercredi.
État de la neige : Mercredi matin, plusieurs centimètres de neige fraîche datant de la veille et de la nuit. Cette couche de neige s'épaissit considérablement au fil des chutes de neige de la journée, recouvrant un manteau neigeux en général printanier, bien regelé. La neige fraîche est de plus en plus travaillée par le vent de Nord, alternant surface dures pelées par le vent et accumulations plus meubles.

Aperçu météo pour le mercredi 01 avril

	nuit	matin	après-midi	soir

Chutes de neige fréquentes en journée avec des cumuls importants, du vent de Nord fort en altitude, de la neige dès 1300m environ.

Pluie-Neige	1 200 m	1 300 m	1 400 m	1 300 m
Iso 0 °C	1 500 m	1 600 m	1 600 m	1 500 m
Vent 1000 m	35 km/h	35 km/h	45 km/h	45 km/h
Vent 2000 m	60 km/h	60 km/h	70 km/h	65 km/h

Épaisseur de neige hors-piste

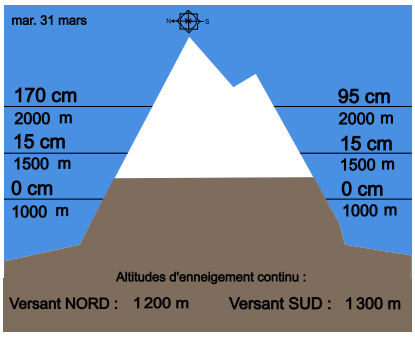

Précipitations à 1800 m

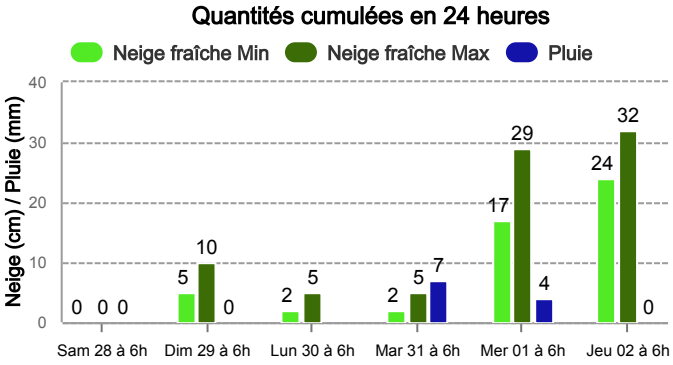

Tendance du jeudi 02 avril

3

Indice de risque marqué

Risque potentiellement en augmentation dans une ambiance encore ventée de Nord. Nouvelles chutes de neige à venir.

Pour consulter la vigilance en cours, veuillez vous rendre sur le site https://vigilance.meteofrance.fr/fr

Météo-France - 73 avenue de Paris, 94165 Saint-Mandé cedex - Contact : contact@meteo.fr

Rédigé par Météo-France avec la contribution des observateurs du réseau nivo-météorologiques. Partenariat : ANMSM (Maires de Stations de Montagne), DSF (Domaines Skiables de France), ADSP (Directeurs de Pistes et de la Sécurité des Stations de Sports d'Hiver) et autres acteurs de la montagne.

Bulletin neige & avalanches par téléphone au

0 892 68 10 20 Service 0,35 € / min + prix appel

RÉPUBLIQUE FRANÇAISE
Liberté Égalité Fraternité

METEO FRANCE
À VOS CÔTÉS, DANS UN CLIMAT QUI CHANGE

Bulletin d'estimation du risque d'avalanche
(valable en dehors des pistes balisées et ouvertes)

MASSIF : Pays-Basque

Rédigé le mardi 31 mars 2026 à 16h

Conditions nivo-météo des 7 derniers jours

	mer. 25/03				jeu. 26/03				ven. 27/03				sam. 28/03				dim. 29/03				lun. 30/03				mar. 31/03			
	03h	09h	15h	21h	03h	09h	15h	21h	03h	09h	15h	21h	03h	09h	15h	21h	03h	09h	15h	21h	03h	09h	15h	21h	03h	09h	15h	21h
Météo																												
Vent (km/h)	15	10	50	65	75	80	85	85	75	65	55	55	55	55	65	75	80	85	75	75	60	45	50	50	55	50	50	55
à 2000m																												
Vent (km/h)	5	2	15	25	35	40	50	50	35	35	35	25	20	25	40	45	45	40	50	40	35	25	35	40	40	30	35	40
à 1000m																												

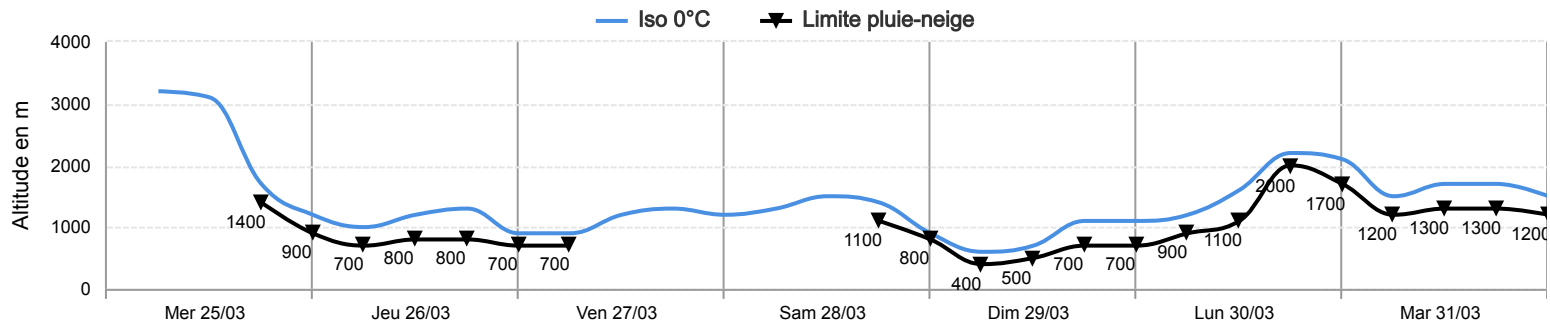

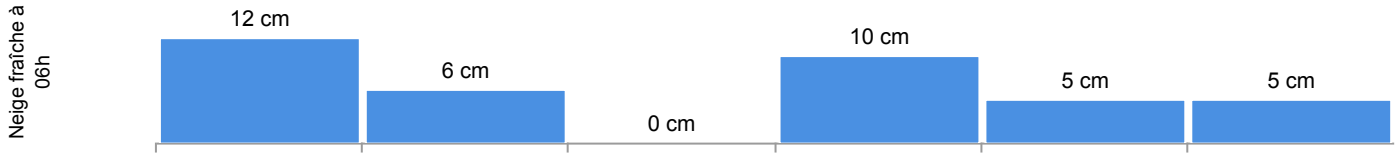

Risque d'avalanche	mer. 25/03	jeu. 26/03	ven. 27/03	sam. 28/03	dim. 29/03	lun. 30/03	mar. 31/03
	2	2	2	2	3	3	2

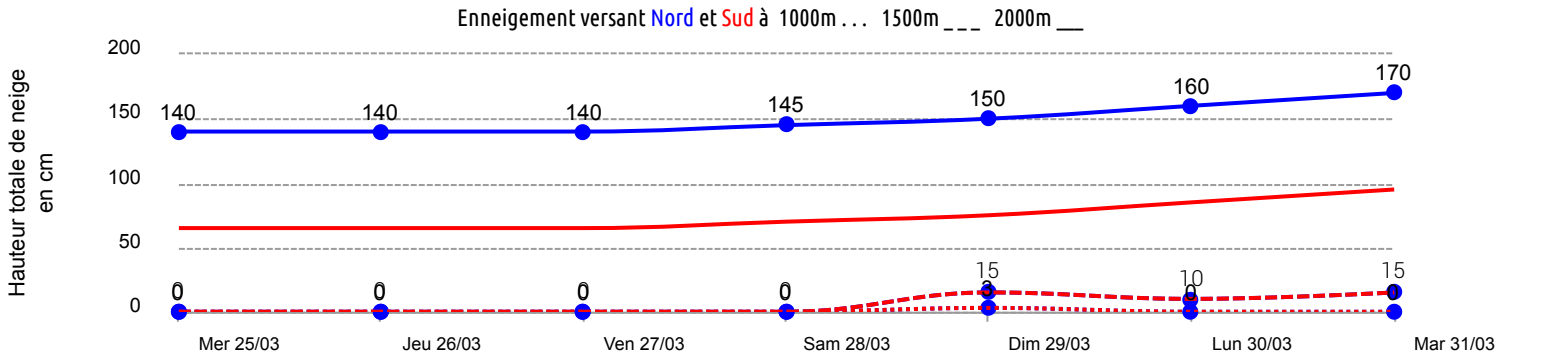

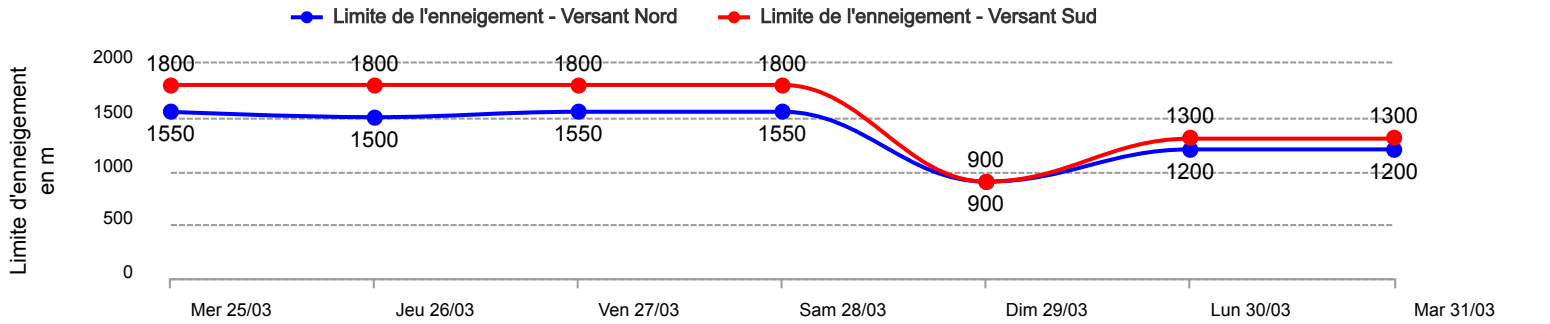

Pour consulter la vigilance en cours, veuillez vous rendre sur le site https://vigilance.meteofrance.fr/fr

Météo-France - 73 avenue de Paris, 94165 Saint-Mandé cedex - Contact : contact@meteo.fr

Rédigé par Météo-France avec la contribution des observateurs du réseau nivo-météorologiques. Partenariat : ANMSM (Maires de Stations de Montagne), DSF (Domaines Skiables de France), ADSP (Directeurs de Pistes et de la Sécurité des Stations de Sports d'Hiver) et autres acteurs de la montagne.

Bulletin neige & avalanches par téléphone au

0 892 68 10 20 Service 0,35 € / min + prix appel