GOBIERNO DE ESPAÑA
VICEPRESIDENCIA TERCERA DEL GOBIERNO
MINISTERIO PARA LA TRANSICIÓN ECOLÓGICA Y EL RETO DEMOGRÁFICO

Boletín de información nivológica y de peligro de aludes

Pirineo Navarro y Aragonés

aemet Agencia Estatal de Meteorología

miércoles, 1 de abril de 2026

Pronóstico hasta las 24 horas del jueves, día 2 de abril

(Válido fuera de pistas de esquí balizadas y abiertas)

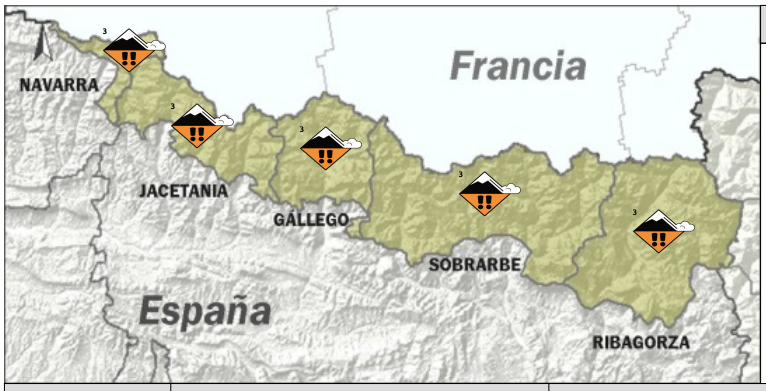

Problemas de aludes

Placas de viento

Nieve reciente

Macizo	Peligro	Problemas de aludes, cota, orientación, tamaño	Innivación observada (m)
Navarra	3 / 3 2 1800 / Notable	Placas de viento: 1800, N O E S, 3 / Nieve reciente: N O E S, 2	2026-04-01 N S Cota más baja caras N
Jacetania	3 / 3 2 1800 / Notable	Placas de viento: 1800, N O E S, 3 / Nieve reciente: N O E S, 2	2026-04-01 N S Cota más baja caras N
Gállego	3 / 3 2 1800 / Notable	Placas de viento: 1800, N O E S, 3 / Nieve reciente: N O E S, 2	2026-04-01 N S Cota más baja caras N

AEMET. Se autoriza la reproducción de su contenido citando la fuente.

Boletín de información nivológica y de peligro de aludes

Pirineo Navarro y Aragonés

Sobrarbe	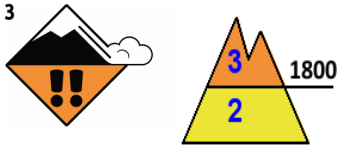 **Notable**	**Placas de viento** **Nieve reciente** 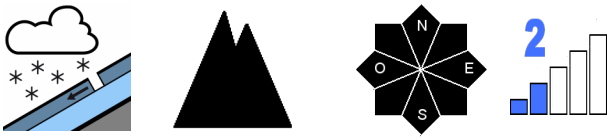	2026-04-01 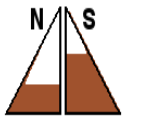 Cota más baja caras N
Ribagorza	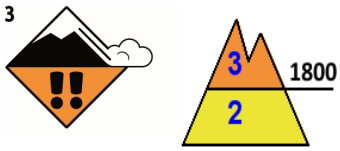 **Notable**	**Placas de viento** 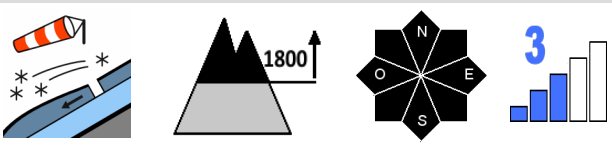 **Nieve reciente** 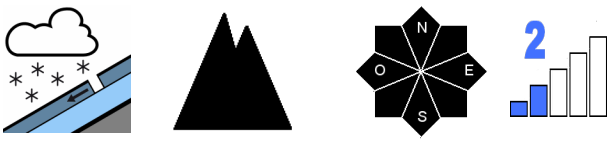	2026-04-01 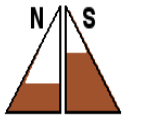 Cota más baja caras N

Estado del manto y observaciones recientes

En las últimas 24 h se han registrado precipitaciones localmente moderadas (17.5 mm en Estós, 13.7 mm en Candanchú, 8.9 mm en Panticosa Casa de Piedra) más intensas en el extremo occidental (28 mm en Linza y 39.6 mm en Belagua), en forma de nieve-lluvia a 1300-1500 m, acompañadas de ventisca en cotas medias-altas con rachas muy fuertes o incluso huracanadas del norte y noroeste.
Se han observado nuevas placas de viento en zonas protegidas del viento del N. Preferentemente en S y SW, aunque afectan a cualquier orientación y altitud por encima de 1800 m. Y mucha nieve reciente en canales, vaguadas, bajo crestas y en inflexiones del terreno, sobre un manto viejo duro y encostrado.
Hay también alguna placa de viento viento vieja en terreno muy inclinado y umbrío por encima de los 2500 m y en la base del manto capas débiles persistentes mostrando a veces reactividad aunque solo ante sobrecargas fuertes.
El manto presenta continuidad desde cotas medias, más abajo en las laderas norte (1600 m) que en las sur (1800 m). Los espesores continúan por encima de lo habitual para estas fechas con valores de 150-200 cm en cota 2200.
No se han reportado aludes en las últimas 24 h desde los puntos de observación.

Evolución del manto y peligro de aludes para el jueves, día 2

Problemas de placas de viento y nieve reciente.

Las placas de viento, a veces de tamaño grande, se mantendrán frágiles sobre un manto nivoso inestable, susceptibles de colapsar ante sobrecargas débiles y continuarán formándose a lo largo del día. Serán abundantes, sobre todo en orientaciones sur, en cotas altas alejadas incluso de crestas y cordales. Se podrán desprender de forma natural o accidental, alcanzando los aludes tamaño mediano o localmente grande. Se esperan también aludes de nieve reciente de tamaño pequeño o mediano, tanto en forma de placa como de salida

AEMET. Se autoriza la reproducción de su contenido citando la fuente.

puntual, en zonas menos afectadas por el viento y con la suficiente inclinación.
El nivel de peligro será más elevado en el entorno de la divisoria fronteriza, disminuyendo de manera significativa en picos más al sur. Concretamente, el nivel 4 se podría alcanzar en la Ribagorza, tercio norte (área Posets-Maladeta), o incluso en el sector navarro, no descartándose aludes de tamaño grande o muy grande en zonas con una acumulación de nieve significativa.

Predicción meteorológica para el jueves, día 2

Pirineo navarro:
Muy nuboso o cubierto, con visibilidad localmente reducida. Precipitaciones débiles o moderadas, podrían ser persistentes en el entorno de la divisoria fronteriza. Cota de nieve en torno a 1200-1400 metros. Temperaturas mínimas sin cambios. Máximas en ligero descenso. Heladas débiles, moderadas en cotas altas. Viento fuerte de componente norte, con rachas muy fuertes en cotas altas y zonas expuestas.
Pirineo aragonés:
Muy nuboso o cubierto en la divisoria fronteriza, con visibilidad localmente reducida. Intervalos nubosos al sur. Precipitaciones débiles o localmente moderadas, principalmente en la divisoria fronteriza, donde podrían ser persistentes. Cota de nieve en torno a 1200-1400 metros. Temperaturas mínimas sin cambios. Máximas en ligero descenso. Heladas débiles, moderadas en cotas altas, donde podrán ser localmente fuertes y persistentes. Viento moderado o fuerte de componente norte, con rachas muy fuertes en cotas altas y zonas expuestas, que podrán superar los 100 km/h.

Datos en la atmósfera libre:

Altitud de la isoterma de 0 ºC: 1600 m
Altitud de la isoterma de -10 ºC: 3700 m

Viento a 1500 m: N 40 km/h
Viento a 3000 m: N 100 km/h

Evolución para el viernes día 3

Nivel de peligro en descenso.

(Información elaborada a partir de los datos recibidos de los refugios de Linza, Lizara, Panticosa, Bachimaña, Góriz, Pineta, Estós, Angel Orús, La Renclusa y Belagua, de las estaciones de esquí de Candanchú, Astún y Panticosa (lagos), de la estación de esquí de fondo de Llanos del Hospital y de Ordesa Pradera)

Escala europea de peligro de aludes

Débil | Limitado | Notable | Fuerte | Muy Fuerte

Problemas de aludes

Nieve reciente | Placas de viento | Capas débiles persistentes | Nieve húmeda | Deslizamientos basales | Sin problema evidente

Nota1: Se recuerda que, siempre que haya nieve, la ausencia total de peligro no existe. Hay que tener presente que en circunstancias desfavorables, con aludes de tamaño 1 (alud pequeño o colada) y tamaño 2 (alud mediano), se pueden sufrir severos daños personales.
Nota2: Los BPA se elaboran en base a información meteorológica así como al estado del manto nivoso a través de sondeos puntuales. Se advierte a los usuarios de la variabilidad de esta información al extrapolarla a zonas extensas de montaña. Por ello, AEMET no se hace responsable de su uso para la toma de decisiones que conciernen a la seguridad personal, ni de los riesgos físicos o materiales de ellas derivadas.

AEMET. Se autoriza la reproducción de su contenido citando la fuente.