aineva.it

Donnerstag 02.04.2026

Veröffentlicht am 01.04.2026 um 17:00

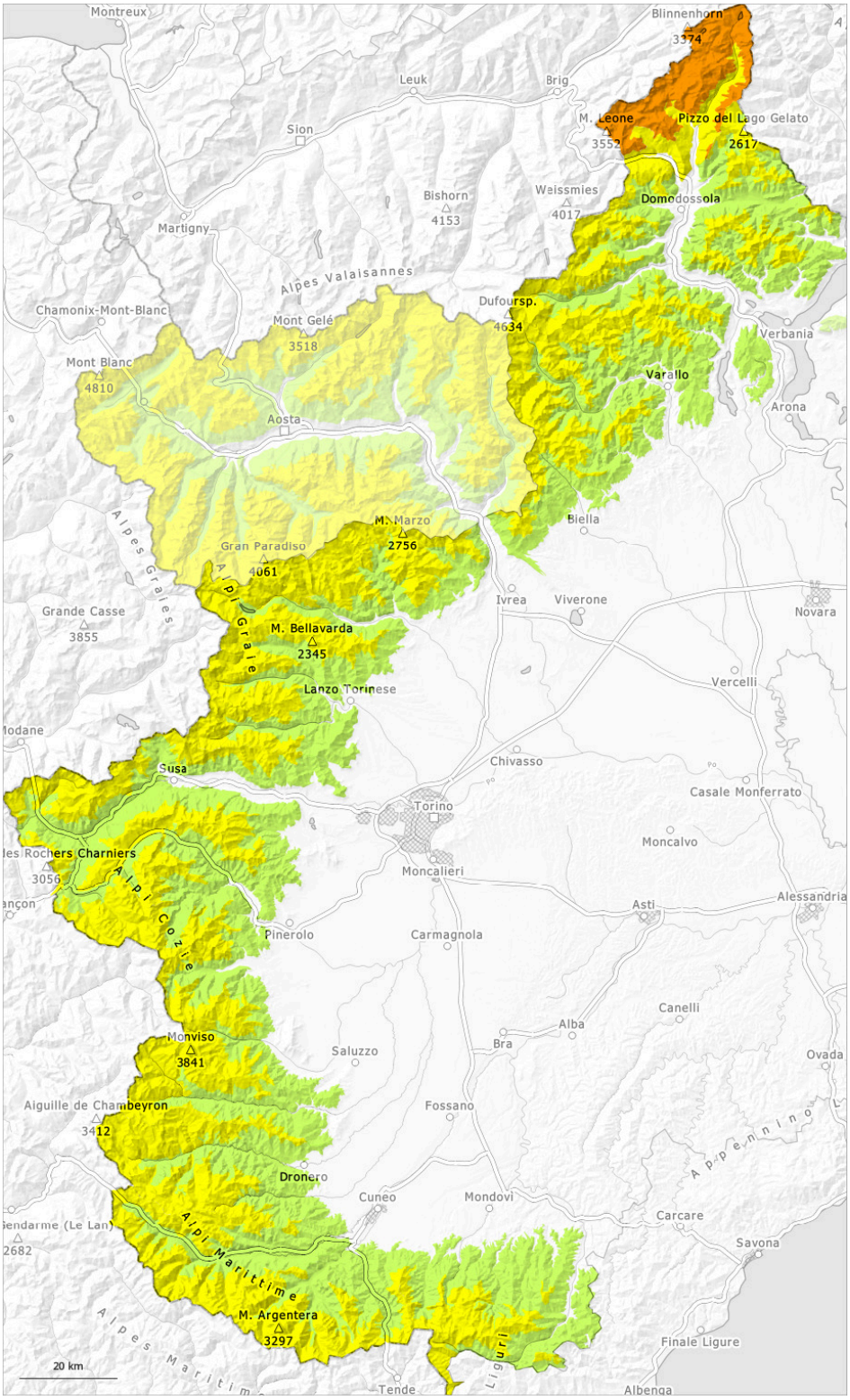

1	2	3	4	5
gering	mäßig	erheblich	groß	sehr groß

Gefahrenstufe 3 - Erheblich

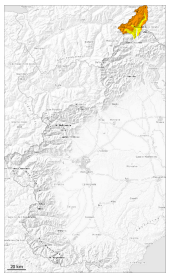

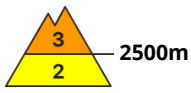

Tendenz: Lawinengefahr bleibt gleich
am Freitag, den 03.04.2026

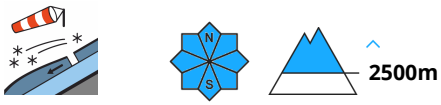

Triebschnee

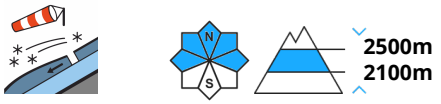

Triebschnee

Triebschnee ist die Hauptgefahr.

Seit Sonntag fielen oberhalb von rund 1600 m 20 bis 40 cm Schnee. Seit Montag blies der Wind stark.

Die gut sichtbaren Triebschneeansammlungen der letzten Tage können vor allem an den Expositionen West über Nord bis Ost oberhalb der Waldgrenze von einzelnen Wintersportlern ausgelöst werden. Die Lawinen können an Triebschneehängen in den verschiedenen Triebschneeschichten ausgelöst werden und groß werden. Ungünstig sind v.a. Stellen, wo Schwachstellen im Altschnee vorhanden sind.

Vorsicht vor allem in Rinnen, Mulden und hinter Geländekanten in mittleren und hohen Lagen.

Schneedecke

Gefahrenmuster gm.6: lockerer schnee und wind

Mit starkem Nordostwind entstanden seit Montag vor allem kammfern teils dicke Triebschneeansammlungen.
Zudem entstanden in windgeschützten Lagen weiche Triebschneeansammlungen.

Die nächtliche Abstrahlung war gut. Tiefe und mittlere Lagen Sonnenhänge: Die Schneeoberfläche ist tragfähig gefroren.

In Kammlagen im Hochgebirge liegen je nach Windeinfluss sehr unterschiedliche Schneehöhen.

Gefahrenstufe 2 - Mäßig

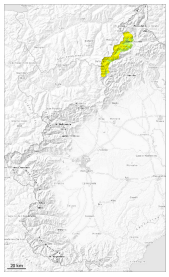

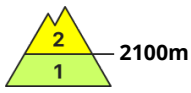

Tendenz: Lawinengefahr bleibt gleich
am Freitag, den 03.04.2026

Triebschnee

2100m

Triebschnee ist die Hauptgefahr.

Seit Sonntag fielen oberhalb von rund 1600 m 10 bis 20 cm Schnee, lokal auch mehr. Seit Montag blies der Wind stark.

Die gut sichtbaren Triebschneeansammlungen der letzten Tage können vor allem an den Expositionen West über Nord bis Ost in hohen Lagen und im Hochgebirge teilweise von einzelnen Wintersportlern ausgelöst werden. Die Lawinen können an Triebschneehängen in den verschiedenen Triebschneeschichten ausgelöst werden und mittlere Größe erreichen. Ungünstig sind v.a. Stellen, wo Schwachstellen im Altschnee vorhanden sind.

Vorsicht vor allem in Rinnen, Mulden und hinter Geländekanten in mittleren und hohen Lagen.

Schneedecke

Gefahrenmuster gm.6: lockerer schnee und wind

Mit starkem Nordostwind entstanden seit Montag an allen Expositionen gut sichtbare Triebschneeansammlungen.

Die nächtliche Abstrahlung war gut. Vor allem tiefe und mittlere Lagen Sonnenhänge: Die Schneeoberfläche ist tragfähig gefroren.

In Kammlagen im Hochgebirge liegen je nach Windeinfluss sehr unterschiedliche Schneehöhen.

Gefahrenstufe 2 - Mäßig

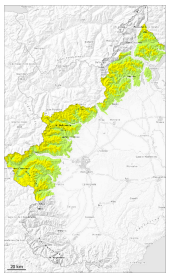

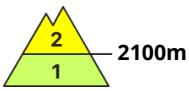

Tendenz: Lawinengefahr bleibt gleich
am Freitag, den 03.04.2026

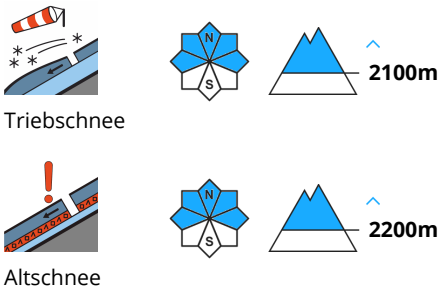

Triebschnee und schwacher Altschnee sind die Hauptgefahr.

Seit Sonntag fiel gebietsweise etwas Schnee. Seit Montag blies der Wind stark. Die gut sichtbaren Triebschneeansammlungen der letzten Tage können in mittleren und hohen Lagen teilweise von einzelnen Wintersportlern ausgelöst werden, besonders in ihren Randbereichen.

Ungünstig sind Stellen, wo im Altschnee persistente Schwachschichten vorhanden sind, die teilweise aus eingeschneitem Oberflächenreif bestehen. Die Lawinen können besonders an steilen West-, Nord- und Osthängen im schwachen Altschnee ausgelöst werden und mittlere Größe erreichen. Dies vor allem mit großer Belastung.

Schneedecke

Gefahrenmuster gm.6: lockerer schnee und wind

Seit Sonntag fielen gebietsweise oberhalb von rund 1700 m 5 bis 20 cm Schnee.

Mit starkem Nordwestwind entstanden seit Montag vor allem kammfern harte Triebschneeansammlungen. Im mittleren Teil der Schneedecke sind in mittleren und hohen Lagen einzelne Schwachschichten vorhanden.

Die nächtliche Abstrahlung war gut. Die Schneeoberfläche ist tragfähig gefroren und weicht im Tagesverlauf auf, v.a. an Sonnenhängen in tiefen und mittleren Lagen.

In Kammlagen in hohen Lagen liegen je nach Windeinfluss sehr unterschiedliche Schneehöhen. Unterhalb der vom Wind erodierten Gipfel, oberhalb von etwa 1600 m, liegt mehr Schnee als im saisonalen Durchschnitt.

Gefahrenstufe 2 - Mäßig

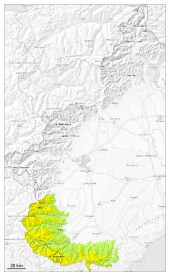

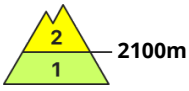

Tendenz: Lawinengefahr bleibt gleich
am Freitag, den 03.04.2026

Triebschnee

2100m

Die Triebschneeansammlungen sind gut erkennbar und vor allem mit großer Belastung auslösbar.

Die Schneedecke ist in tiefen und mittleren Lagen gut verfestigt.

Mittlere und hohe Lagen: Mit Neuschnee und mäßigem bis starkem Wind aus nordöstlichen Richtungen entstanden in den letzten Tagen in Rinnen, Mulden und hinter Geländekanten gut sichtbare Triebschneeansammlungen. Diese können vor allem mit großer Belastung ausgelöst werden und mittlere Größe erreichen.

Auf der eisigen Kruste besteht im Steilgelände Absturzgefahr.

Schneedecke

Gefahrenmuster gm.6: lockerer schnee und wind

Seit Montag blies der Wind verbreitet stark. In Gipfellagen liegen je nach Windeinfluss sehr unterschiedliche Schneehöhen.

Vor allem Sonnenhänge tiefe und mittlere Lagen: Die Schneeoberfläche ist tragfähig gefroren und weicht im Tagesverlauf auf.

In schattigen, windgeschützten Lagen hohe Lagen und Hochgebirge: Der obere Bereich der Schneedecke ist trocken, mit einer nicht tragfähigen Kruste an der Oberfläche. Im oberen Teil der Schneedecke sind vor allem an steilen Schattenhängen sehr vereinzelt Schwachschichten vorhanden.

Tendenz

Mit der tageszeitlichen Erwärmung und der Sonneneinstrahlung steigt die Auslösebereitschaft von spontanen feuchten Lawinen an sehr steilen Sonnenhängen in tiefen und mittleren Lagen etwas an.