Giovedì 02.04.2026

Pubblicato il 01.04.2026 alle ore 17:00

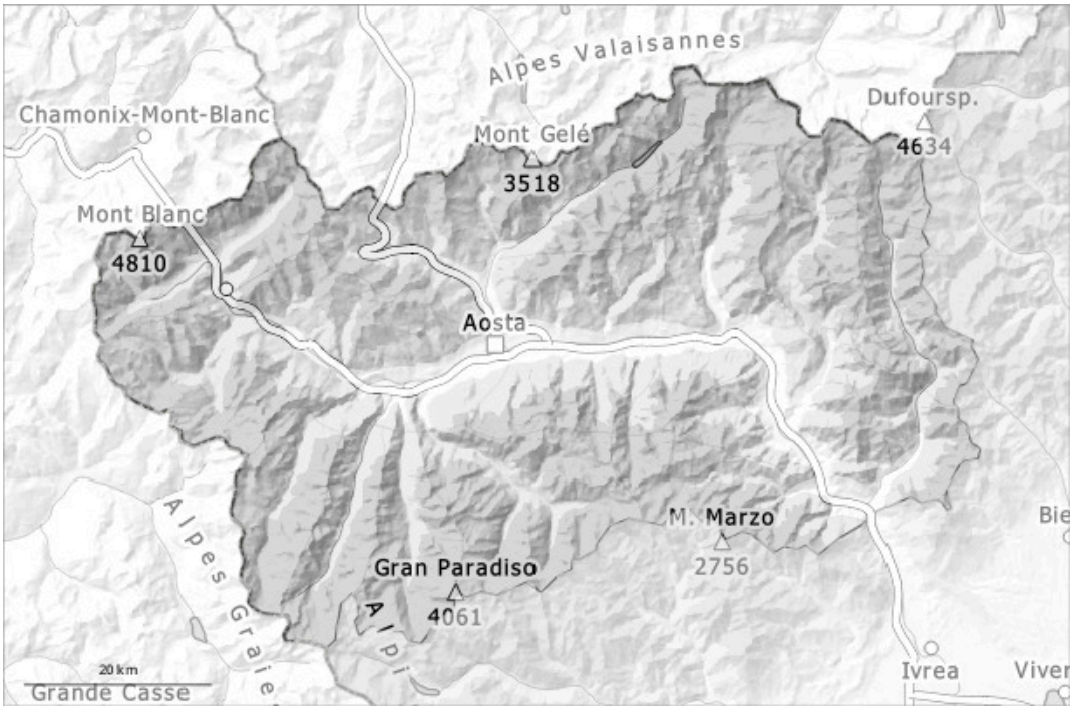

1	2	3	4	5
debole	moderato	marcato	forte	molto forte

Grado di pericolo 2 - Moderato

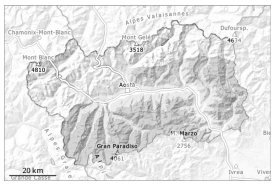

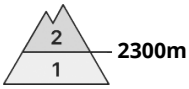

Tendenza: pericolo valanghe stabile
per Venerdì il 03.04.2026

Lastrone da vento

2300m

La neve ventata recente è la principale fonte di pericolo.

Con il vento a tratti forte, gli accumuli di neve ventata sono leggermente cresciuti. Questi possono in alcuni punti distaccarsi in seguito al passaggio di un singolo appassionato di sport invernali, attenzione sui pendii molto ripidi nelle zone di passaggio da poca a molta neve come p.es. all'ingresso di conche e canaloni. Gli accumuli di neve ventata sono ben individuabili dall'escursionista esperto.
Principalmente sui pendii carichi di neve ventata le valanghe asciutte possono coinvolgere i vari strati di neve ventata e, a livello isolato raggiungere dimensioni medie.
Sulla crosta dura sussiste un pericolo di caduta nelle zone ripide, principalmente sui pendii soleggiati molto ripidi.

Manto nevoso

Situazione tipo st.6: neve a debole coesione e vento

Ieri sono caduti da 5 a 10 cm di neve al di sopra dei 2000 m circa, localmente anche meno. Fino a mercoledì il vento sarà forte.
A livello locale da domenica sono caduti da 2 a 10 cm di neve al di sopra dei 2000 m circa, localmente anche meno.
In molte regioni, il vento è stato da forte a tempestoso. In molti punti l'innevamento è estremamente variabile a seconda dell'azione del vento. Ad alta quota e in alta montagna: Salendo di quota l'innevamento si riduce e diventa disomogeneo. Risulta spesso migliore alle quote intermedie meno interessate dal vento.
Il manto nevoso in superficie cambia rapidamente in base all'esposizione e pendenza: croste di varia natura e spessore spesso si alternano.
Sulla crosta dura sussiste un pericolo di caduta nelle zone ripide, soprattutto nelle zone in prossimità delle creste e dei passi.
L'irradiazione solare ha causato un assestamento del manto nevoso.
Specialmente sui pendii ombreggiati ripidi, all'interno del manto nevoso si trovano strati fragili.

Tendenza

Le condizioni meteo consentiranno un consolidamento degli accumuli di neve ventata. I punti pericolosi si trovano sui pendii carichi di neve ventata in quota.

Grado di pericolo 2 - Moderato

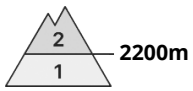

Tendenza: pericolo valanghe stabile
per Venerdì il 03.04.2026

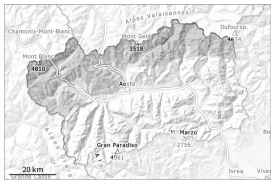

Lastrone da vento

Lastrone da vento

La neve ventata recente è la principale fonte di pericolo.

Con neve fresca e vento forte proveniente dai quadranti settentrionali anche nelle zone lontano dalle creste si sono formati accumuli di neve ventata visibili. Questi ultimi possono in parte subire un distacco in seguito al passaggio di un singolo appassionato di sport invernali. Soprattutto lungo il confine con la Francia e lungo il confine con la Svizzera e alle quote medie e alte, questi punti pericolosi sono più diffusi e il pericolo superiore, attenzione sui pendii molto ripidi nelle zone di passaggio da poca a molta neve come p.es. all'ingresso di conche e canaloni. Principalmente qui le valanghe asciutte possono coinvolgere i vari strati di neve ventata e raggiungere dimensioni medie.
Dove il vento è stato meno intenso, si sono formati lastroni soffici. Si stanno legando con il vecchio manto nevoso, però sono attualmente poco visibili. Le fessure che si formano quando si calpesta la coltre di neve sono possibili segnali di pericolo.

Le escursioni richiedono un'attenta scelta dell'itinerario.
Con il rialzo termico e l'irradiazione solare, l'attività di valanghe spontanee aumenterà lentamente, principalmente sui pendii soleggiati ripidi estremi. Nel corso della giornata saranno possibili isolate colate umide. Ciò anche alle basi di pareti rocciose.

Manto nevoso

Situazione tipo st.6: neve a debole coesione e vento

A livello locale ieri sono caduti da 10 a 20 cm di neve al di sopra dei 2000 m circa. Fino a mercoledì il vento sarà, nelle zone in prossimità delle creste, forte.
Da domenica sono caduti da 5 a 20 cm di neve al di sopra dei 2000 m circa.
In molte regioni, il vento è stato da forte a tempestoso. In molti punti l'innevamento è estremamente variabile a seconda dell'azione del vento.
Ad alta quota e in alta montagna: Salendo di quota l'innevamento si riduce e diventa disomogeneo. Risulta spesso migliore alle quote intermedie meno interessate dal vento.

Il manto nevoso in superficie cambia rapidamente in base all'esposizione e pendenza: croste di varia natura e spessore spesso si alternano. Esso è duro, con una crosta spesso portante in superficie.
Sulla crosta dura sussiste un pericolo di caduta nelle zone ripide, soprattutto nelle zone in prossimità delle creste e dei passi.
La parte superiore del manto nevoso è soffice, con una superficie a debole coesione, principalmente nelle zone al riparo dal vento.
L'irradiazione solare ha causato un assestamento del manto nevoso.
Specialmente sui pendii ombreggiati ripidi, all'interno del manto nevoso si trovano strati fragili.

Tendenza

Le condizioni meteo consentiranno un consolidamento degli accumuli di neve ventata. I punti pericolosi si trovano sui pendii carichi di neve ventata in quota.