Donnerstag 02.04.2026

Veröffentlicht am 01.04.2026 um 17:00

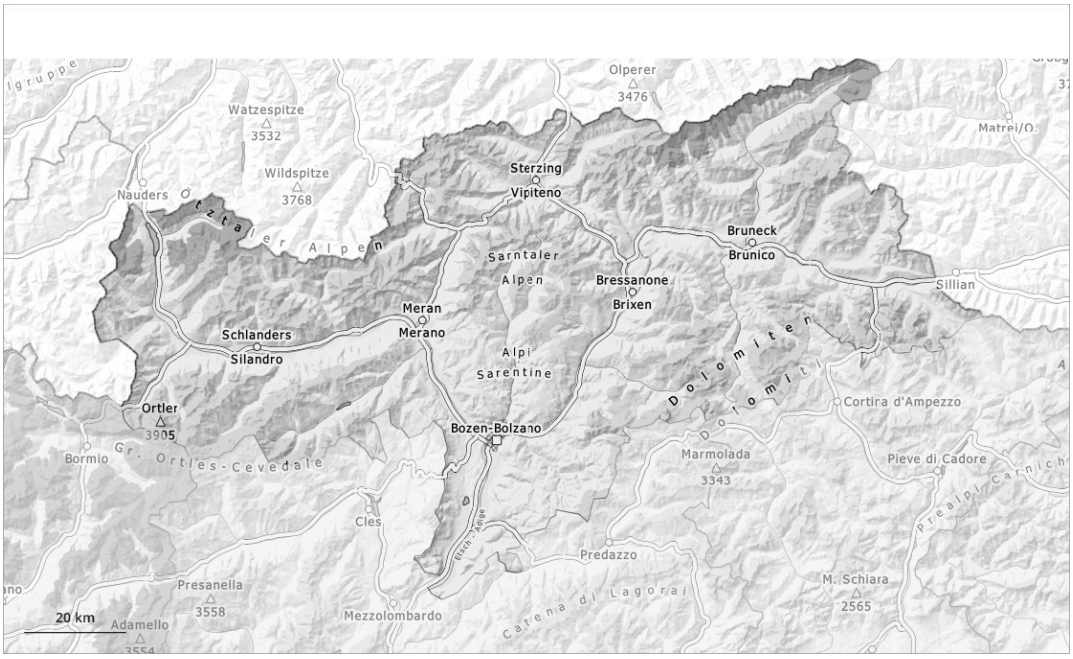

1	2	3	4	5
gering	mäßig	erheblich	groß	sehr groß

Gefahrenstufe 3 - Erheblich

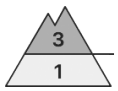

Waldgrenze

Tendenz: Lawinengefahr nimmt ab
am Freitag, den 03.04.2026

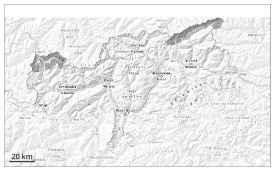

Triebschnee

Waldgrenze

Altschnee

2200m

Triebschnee ist die Hauptgefahr. Schwachen Altschnee vorsichtig beurteilen.

Mit Neuschnee und starkem bis stürmischem Wind entstanden an allen Expositionen gut sichtbare Triebschneeansammlungen. Mit teils starkem Nordostwind entstehen am Mittwoch weitere Triebschneeansammlungen. Diese können oberhalb der Waldgrenze leicht ausgelöst werden. Vorsicht vor allem an Felswandfüßen und hinter Geländekanten sowie in Kammlagen, Rinnen und Mulden. Lawinen sind meist mittelgroß. Risse beim Betreten der Schneedecke können auf die Gefahr hinweisen.

Zudem können vereinzelt Lawinen in bodennahe Schichten der Schneedecke durchreißen und groß werden, besonders an West-, Nord- und Osthängen oberhalb von rund 2200 m und an Südhängen in der Höhe.

Es sind Lockerschneelawinen möglich, aber meist nur kleine. Dies vor allem bei Sonneneinstrahlung, besonders an extrem steilen Hängen.

Schneedecke

Gefahrenmuster gm.6: lockerer schnee und wind | gm.1: bodennahe schwachschicht

In den letzten Tagen fielen 10 bis 20 cm Schnee, lokal auch mehr. Der teilweise stürmische Wind hat den Neuschnee verfrachtet. Die verschiedenen Triebschneeansammlungen sind teilweise schlecht miteinander verbunden.

Die Altschneedecke ist stellenweise schwach, besonders an West-, Nord- und Osthängen oberhalb von rund 2200 m und an Südhängen in der Höhe.

Tendenz

Triebschnee und schwacher Altschnee sind die Hauptgefahr.

Gefahrenstufe 2 - Mäßig

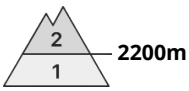

Tendenz: Lawinengefahr bleibt gleich
am Freitag, den 03.04.2026

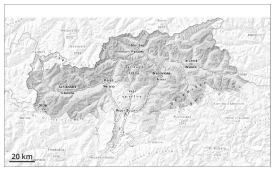

Triebschnee

Altschnee

Triebschnee ist die Hauptgefahr. Schwachen Altschnee beachten.

Mit stürmischem Wind aus nördlichen Richtungen entstanden an allen Expositionen gut sichtbare Triebschneeansammlungen. Diese können oberhalb von rund 2200 m schon von einzelnen Wintersportlern ausgelöst werden. Vorsicht vor allem an Felswandfüßen und hinter Geländekanten sowie in Kammlagen, Rinnen und Mulden. Lawinen sind meist mittelgroß. Risse beim Betreten der Schneedecke können auf die Gefahr hinweisen.

Zudem können vereinzelt Lawinen in bodennahe Schichten der Schneedecke durchreißen und groß werden, besonders an West-, Nord- und Osthängen oberhalb von rund 2200 m und an Südhängen in der Höhe.

Schneedecke

Gefahrenmuster gm.6: lockerer schnee und wind | gm.1: bodennahe schwachschicht

Der böige Wind hat Neu- und Altschnee intensiv verfrachtet. Die verschiedenen Triebschneeansammlungen sind teilweise noch schlecht miteinander verbunden.

Die Altschneedecke ist stellenweise schwach, besonders an West-, Nord- und Osthängen oberhalb von rund 2200 m und an Südhängen in der Höhe.

Tendenz

Triebschnee und schwachen Altschnee beachten.

Gefahrenstufe 1 - Gering

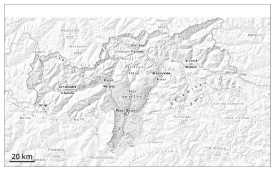

1

Tendenz: Lawinengefahr nimmt ab
am Freitag, den 03.04.2026

Frischen Triebschnee vorsichtig beurteilen.

Triebschneeansammlungen sind vor allem an den Expositionen West über Nord bis Ost oberhalb der Waldgrenze teils störanfällig. Lawinen können sehr vereinzelt in bodennahe Schichten der Schneedecke durchreißen und vereinzelt mittlere Größe erreichen.

Schneedecke

Gefahrenmuster gm.6: lockerer schnee und wind | gm.1: bodennahe schwachschicht

Der Wind bläst mäßig bis stark. Der Wind hat Schnee verfrachtet. Es entstanden teils störanfällige Triebschneeansammlungen.

Tendenz

Frischen Triebschnee vorsichtig beurteilen.