Donnerstag 02.04.2026

Veröffentlicht am 01.04.2026 um 17:00

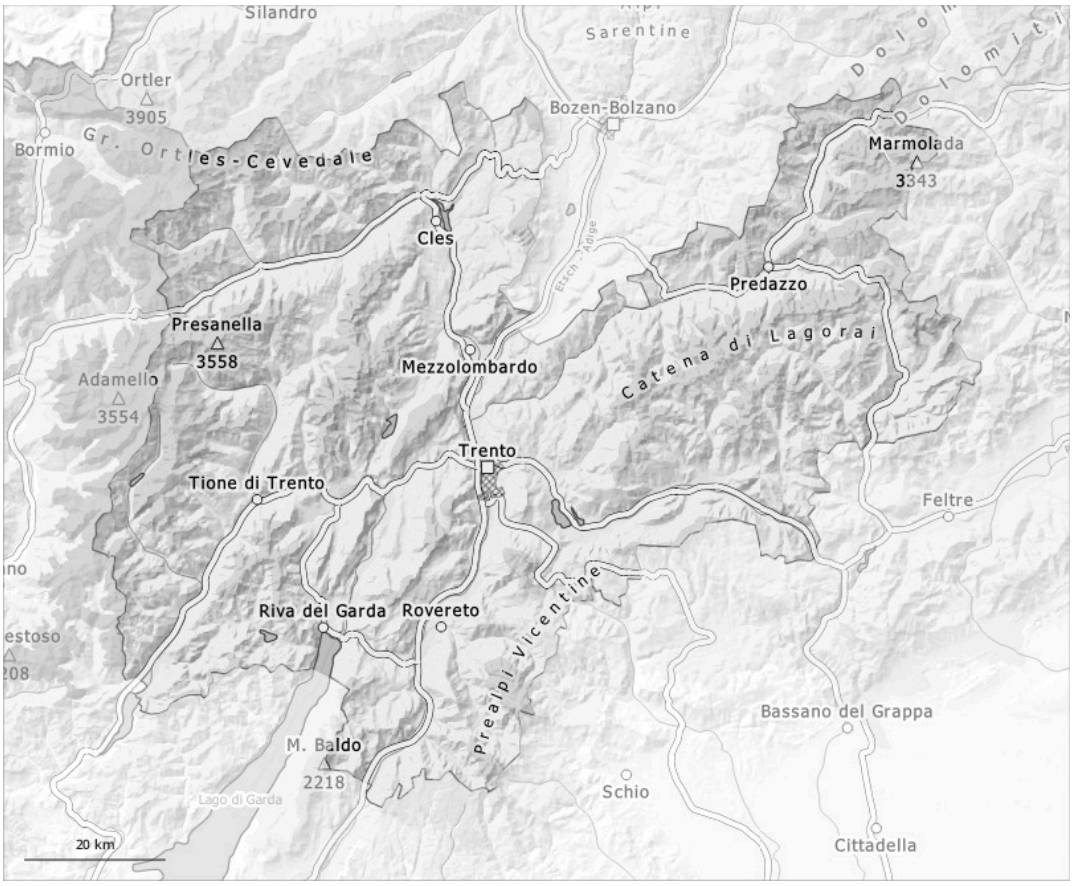

1	2	3	4	5
gering	mäßig	erheblich	groß	sehr groß

Gefahrenstufe 2 - Mäßig

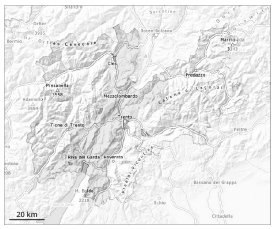

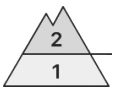

Waldgrenze

Tendenz: Lawinengefahr bleibt gleich
am Freitag, den 03.04.2026

Triebschnee

Waldgrenze

Triebschnee ist die Hauptgefahr.

Die Sonneneinstrahlung führt im Tagesverlauf unterhalb von rund 2000 m zu einer Aufweichung der Schneedecke. Die frischeren Triebschneeansammlungen bilden die Hauptgefahr. Lawinen können bis auf den Boden durchreißen und mittlere Größe erreichen.

Schneedecke

Gefahrenmuster gm.6: lockerer schnee und wind | gm.1: bodennahe schwachschicht

Mit starkem bis stürmischem Wind aus nördlichen Richtungen entstanden in den letzten Tagen v.a. in Rinnen, Mulden und hinter Geländekanten teils große Triebschneeansammlungen. Die frischen Triebschneeansammlungen liegen an allen Expositionen und allgemein oberhalb der Waldgrenze auf einer ungünstigen Altschneeoberfläche.
Die Sonneneinstrahlung führt im Tagesverlauf unterhalb von rund 2000 m zu einer Aufweichung der Schneedecke.

Tendenz

Freitag: Die Lawinengefahr bleibt bestehen.

Gefahrenstufe 2 - Mäßig

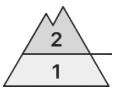

Waldgrenze

Tendenz: Lawinengefahr bleibt gleich
am Freitag, den 03.04.2026

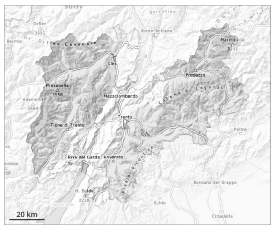

Triebschnee

Waldgrenze

Altschnee

Waldgrenze

Vorsicht vor Triebschnee und schwachem Altschnee.

Mit starkem bis stürmischem Nordwind entstanden in den letzten Tagen flächige Triebschneeansammlungen. In Kammlagen, Rinnen und Mulden und an steilen Hängen sind trockene Schneebrettlawinen möglich. Lawinen können vor allem mit großer Belastung ausgelöst werden. Dies vor allem oberhalb der Waldgrenze sowie an Übergängen von wenig zu viel Schnee wie z.B. bei der Einfahrt in Rinnen und Mulden.
In der Altschneedecke sind an sehr steilen Schattenhängen heikle Schwachschichten vorhanden. Diese Gefahrenstellen liegen vor allem an den Expositionen Ost über Nord bis West. Besonders in Kammlagen, Rinnen und Mulden sind mittlere und vereinzelt große Lawinen möglich.

Schneedecke

Gefahrenmuster gm.6: lockerer schnee und wind | gm.1: bodennahe schwachschicht

Der teilweise stürmische Wind hat Schnee verfrachtet. Mit starkem bis stürmischem Wind aus nördlichen Richtungen entstanden in den letzten Tagen v.a. in Rinnen, Mulden und hinter Geländekanten teils große Triebschneeansammlungen. Die frischen Triebschneeansammlungen liegen vor allem an den Expositionen Ost über Nord bis West und allgemein oberhalb der Waldgrenze auf einer ungünstigen Altschneeoberfläche.
Die Sonneneinstrahlung führt im Tagesverlauf unterhalb von rund 2000 m zu einer Aufweichung der Schneedecke.

Tendenz

Freitag: Die Lawinengefahr bleibt bestehen.