ICGC Institut Cartogràfic i Geològic de Catalunya

Servei Meteorològic de Catalunya meteo.cat

Boletín de peligro de aludes para el Pirineo de Catalunya
Del 01/04/2026 al 02/04/2026

(Válido fuera pistas de esquí y zonas no controladas)

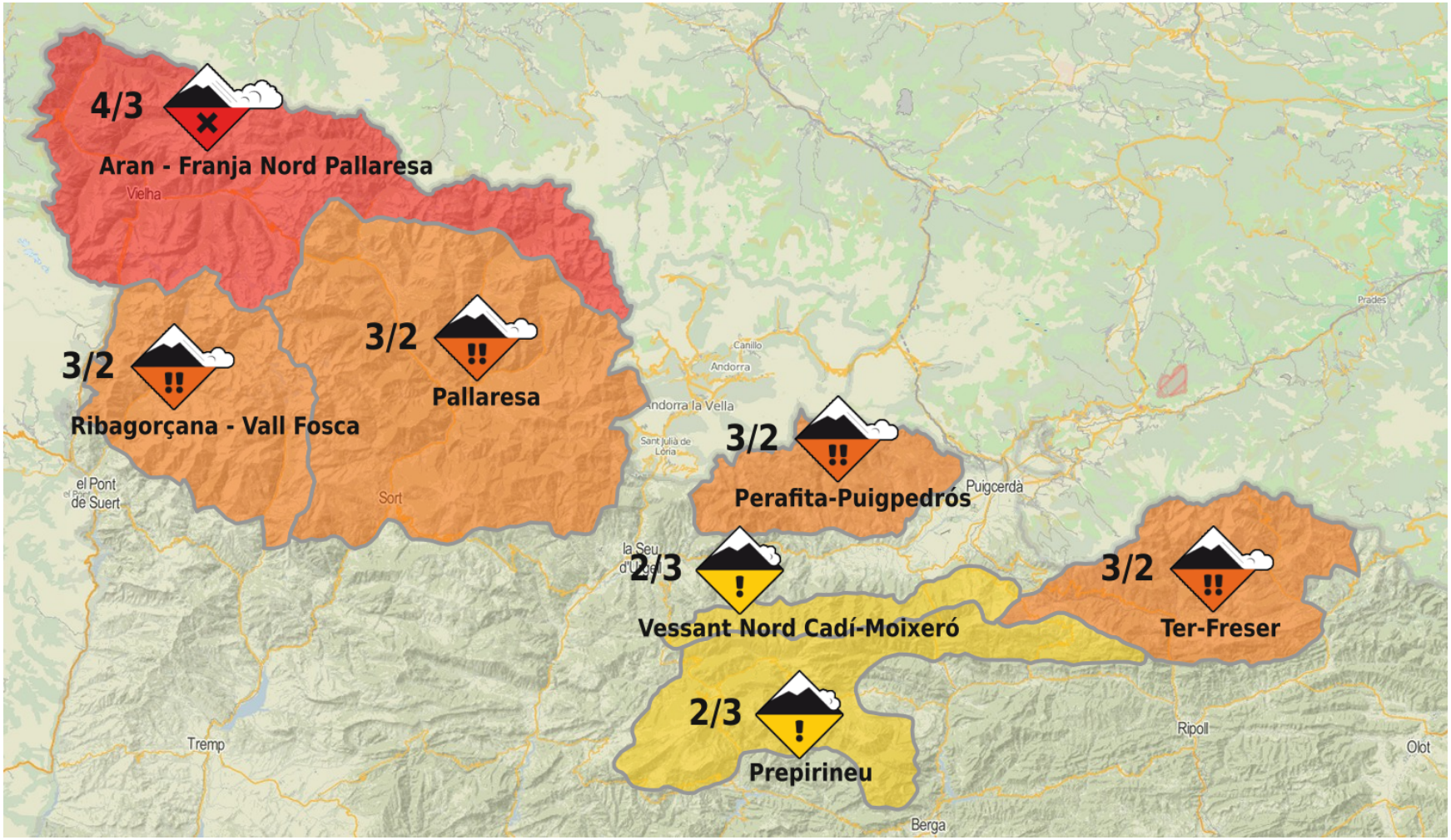

5 MUY FUERTE	4 FUERTE	3 NOTABLE	2 LIMITADO	1 DÉBIL

ICGC Institut Cartogràfic i Geològic de Catalunya

Servei Meteorològic de Catalunya

Boletín de peligro de aludes Aran - Franja Nord Pallaresa Del 01/04/2026 al 02/04/2026

(Válido fuera pistas de esquí y zonas no controladas)

FUERTE (4) por la mañana. NOTABLE (3) por la tarde.

Situación primaria

Nieve venteada | **Distribución** | **Tamaño** | **Origen** | **Tendencia**

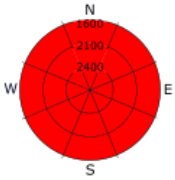

Situación secundaria

Nieve reciente | **Distribución** | **Tamaño** | **Origen** | **Tendencia**

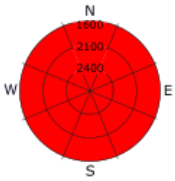

Estado del manto nivoso

La estabilidad del manto será muy pobre en el sector. Se esperan acumulaciones de nieve que podrían rodear los 50 cm entre el miércoles y el jueves, acompañadas de viento. Se formarán placas de viento en diferentes sotaventos, las más destacables en orientaciones sur de la Franja Norte de la Pallaresa. En estos lugares se podrían desprender de forma natural aludes de tamaño 4, suficiente para llegar a fondo de valle y recorrer más de 50 m en terreno llano. En el resto del sector, los aludes de placa serán en conjunto de tamaño 3, suficiente para enterrar a un grupo de personas. También se esperan aludes de nieve reciente, tanto en forma de placa como de salida puntual, en lugares de fuerte pendiente y poco afectados por la acción del viento. Localmente podrían alcanzar tamaño 3. Los aludes naturales serán menos frecuentes la tarde del jueves y el peligro bajará a MARCADO (3), pero los aludes accidentales seguirán siendo muy probables. Se recomienda no acceder a terreno alud el jueves.

Distribución del manto nivoso

El actual episodio de nevadas está blanqueando el suelo por encima de unos 1.400 m. Los espesores a unos 2.200 m son ligeramente superiores a los normales en la Franja Norte de la Pallaresa y en la mitad sur de Arán, donde rondan los 180-240 cm. En la mitad norte de Arán son los normales por estas fechas con unos 130-150 cm de espesor total.

Tendencia para las próximas 48-72h

Clara estabilización de la nieve por los problemas de placa de viento y nieve reciente, pero se prevé una elevada actividad de aludes de nieve húmeda. Peligro EN DESCENSO.

El próximo boletín será emitido el día 2026-04-02

5 MUY FUERTE	4 FUERTE	3 NOTABLE	2 LIMITADO	1 DÉBIL

EAWS EUROPEAN AVALANCHE WARNING SERVICES

ICGC Institut Cartogràfic i Geològic de Catalunya

Servei Meteorològic de Catalunya

Boletín de peligro de aludes Ribagorçana - Vall Fosca Del 01/04/2026 al 02/04/2026

(Válido fuera pistas de esquí y zonas no controladas)

NOTABLE (3) en la mitad norte por encima del nivel del bosque. LIMITADO (2) en el resto.

Situación primaria

Nieve venteada

Distribución

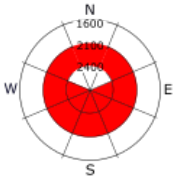

Tamaño

Origen

Tendencia

Situación secundaria

Nieve húmeda

Distribución

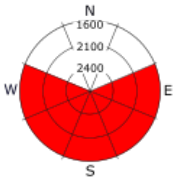

Tamaño

Origen

Tendencia

Estado del manto nivoso

La estabilidad del manto va empeorando a causa del episodio de viento y nieve que está teniendo lugar entre el miércoles y el jueves, de forma más destacada en el norte del sector. Se están formando placas de viento en diferentes sotaventos, principalmente los orientados a oeste, sur y este, por lo general duras pero que se podrán desprender al paso de una persona. En caso de caer, los aludes podrán alcanzar tamaño 2 o, de forma local, tamaño 3 (suficiente para enterrar a un grupo de personas) en sotaventos muy claros del norte del sector. Los aludes se podrán desprender de forma natural, sobre todo hasta mediodía. En momentos de ojeadas de sol también caerán purgas de nieve reciente húmeda o nieve húmeda, de forma natural y que afectarán principalmente a la nieve del último episodio; serán más frecuentes por la tarde. No se descarta algún alud de tamaño 2 en el norte del sector.

Distribución del manto nivoso

Aunque hay nieve desde unos 1.300 m por el actual episodio de nevadas, la nieve presenta cierta continuidad a partir de 1.700 m en terreno umbrío y de 1.900 m solanas. Los grosores alcanzan los 100-120 cm a unos 2.200 m. Estos valores se acercan a los normales para la época.

Tendencia para las próximas 48-72h

Las placas tenderán a estabilizar de forma progresiva. El manto irá humedeciendo superficialmente y se espera actividad de aludes de nieve húmeda. Peligro EN DESCENSO.

El próximo boletín será emitido el día 2026-04-02

5 MUY FUERTE	4 FUERTE	3 NOTABLE	2 LIMITADO	1 DÉBIL

EAWS EUROPEAN AVALANCHE WARNING SERVICES

ICGC Institut Cartogràfic i Geològic de Catalunya

Servei Meteorològic de Catalunya meteo.cat

Boletín de peligro de aludes Pallaresa
Del 01/04/2026 al 02/04/2026

(Válido fuera pistas de esquí y zonas no controladas)

NOTABLE (3) en la mitad norte por encima del nivel del bosque. LIMITADO (2) en el resto.

Situación primaria

Nieve venteada

Distribución

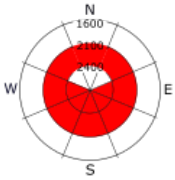

Tamaño

Origen

Tendencia

Situación secundaria

Nieve húmeda

Distribución

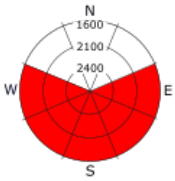

Tamaño

Origen

Tendencia

Estado del manto nivoso

La estabilidad del manto va empeorando a causa del episodio de viento y nieve que está teniendo lugar entre el miércoles y el jueves, de forma más destacada en el norte del sector. Se están formando placas de viento en diferentes sotaventos, principalmente los orientados a oeste, sur y este, por lo general duras pero que se podrán desprender al paso de una persona. En caso de caer, los aludes podrán alcanzar tamaño 2 o, de forma local, tamaño 3 (suficiente para enterrar a un grupo de personas) en sotaventos muy claros del norte del sector. Los aludes se podrán desprender de forma natural, sobre todo hasta mediodía. En momentos de ojeadas de sol también caerán purgas de nieve reciente húmeda o nieve húmeda, de forma natural y que afectarán principalmente a la nieve del último episodio; serán más frecuentes por la tarde. No se descarta algún alud de tamaño 2 en el norte del sector.

Distribución del manto nivoso

Aunque hay nieve desde unos 1.300 m por el actual episodio de nevadas, la nieve presenta cierta continuidad por encima de 1.700 ma terreno umbrío y de 1.900 ma solanas. Los espesores alcanzan los 110-150 cm en cotas medias, puntualmente más, variable según los efectos del viento.

Tendencia para las próximas 48-72h

Las placas tenderán a estabilizar de forma progresiva. El manto irá humedeciendo superficialmente y se espera actividad de aludes de nieve húmeda. Peligro EN DESCENSO.

El próximo boletín será emitido el día 2026-04-02

5 MUY FUERTE	4 FUERTE	3 NOTABLE	2 LIMITADO	1 DÉBIL

EAWS EUROPEAN AVALANCHE WARNING SERVICES

ICGC Institut Cartogràfic i Geològic de Catalunya

meteo.cat Servei Meteorològic de Catalunya

Boletín de peligro de aludes Perafita-Puigpedrós Del 01/04/2026 al 02/04/2026

(Válido fuera pistas de esquí y zonas no controladas)

NOTABLE (3) por encima del nivel del bosque. LIMITADO (2) por debajo.

Situación primaria

Nieve venteada

Distribución

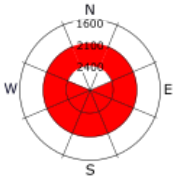

Tamaño

Origen

Tendencia

Situación secundaria

Nieve húmeda

Distribución

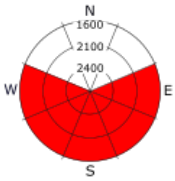

Tamaño

Origen

Tendencia

Estado del manto nivoso

La estabilidad empeora entre el miércoles y el jueves por el episodio de viento y nieve que está teniendo llco. Se acumularán unos 30 cm, muy afectados por el viento de norte y noroeste. En estas condiciones se formarán placas de viento a sotaventos orientados al sur, principalmente, que irán ganando grosor y siendo más inestables a lo largo del miércoles. Estas placas podrán caer al paso de una persona o, incluso, de forma natural, en especial la mañana del jueves. Se tratará de aludes de tamaño 2, suficiente para enterrar a una persona, aunque no se descartan mayores a sotaventos muy claros. En momentos de ojeadas de sol también caerán purgas de nieve reciente húmeda o nieve húmeda, de forma natural y que afectarán principalmente a la nieve del último episodio; serán más frecuentes por la tarde.

Distribución del manto nivoso

Hay nieve en el suelo por encima de 1.400 m por las nevadas actuales, con cierta continuidad por encima de unos 1.900 m, y de 2.200 m en solanas. Es esquiable a partir de unos 2.000 m en N. Los espesores, aunque irregulares, rondan los 70-100 cm en umbrías, a 2.300 m. Son grosores por encima de los habituales en esta época.

Tendencia para las próximas 48-72h

Tendencia a la estabilización de las placas. El manto tenderá a humedecer pero los aludes húmedos serán menos habituales que el jueves. Peligro EN DESCENSO.

El próximo boletín será emitido el día 2026-04-02

5 MUY FUERTE	4 FUERTE	3 NOTABLE	2 LIMITADO	1 DÉBIL

EAWS EUROPEAN AVALANCHE WARNING SERVICES

ICGC Institut Cartogràfic i Geològic de Catalunya

Servei Meteorològic de Catalunya meteo.cat

Boletín de peligro de aludes Vessant Nord Cadí-Moixeró Del 01/04/2026 al 02/04/2026

(Válido fuera pistas de esquí y zonas no controladas)

LIMITADO (2). NOTABLE (3) en el Moixeró por encima de 2.200 m.

Situación primaria

Nieve venteada

Distribución

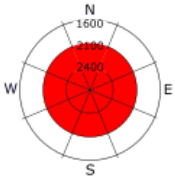

Tamaño

Origen

Tendencia

Situación secundaria

Nieve húmeda

Distribución

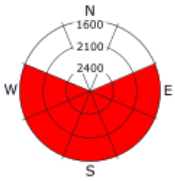

Tamaño

Origen

Tendencia

Estado del manto nivoso

El actual episodio de nevadas dejará cantidades inciertas de precipitación en el sector, que podrían llegar a los 30 cm en el Moixeró. El viento dará lugar a transporte y formará placas en diferentes sotaventos, prioritariamente los orientados a oeste, sur y este. Se tratará principalmente de placas duras pero suficientes delgadas para ser desencadenadas al paso de una sola persona o incluso de forma natural. Se encontrarán principalmente en sotaventos orientados a sur y este, pero también a zonas muy resguardadas del viento del resto de orientaciones como las canales más cerradas del Cadí. En caso de desprenderse se tratará de aludes de hasta tamaño 2, suficiente para enterrar a una persona. En momentos de ojeadas de sol también caerán purgas de nieve reciente húmeda o nieve húmeda, de forma natural y que afectarán principalmente a la nieve del último episodio; serán más frecuentes por la tarde. No se descarta algún alud de tamaño 2 en el norte del sector.

Distribución del manto nivoso

Aunque podemos encontrar nieve en cotas más bajas por el actual episodio de nevadas, en umbrías hay presencia discontinua de nieve por encima de unos 1.700 my es esquiable por encima de unos 1.900 m. Los grosores están alrededor de 160-180 cm a 2.200 m. Estos valores son muy excedentarios para la época del año.

Tendencia para las próximas 48-72h

Continuará el humedecimiento superficial de la nieve, con menor actividad de aludes de nieve húmeda ya que muchas vertientes habrán purgado. Menguará la actividad natural de aludes de placa. Peligro EN DESCENSO.

El próximo boletín será emitido el día 2026-04-02

5 MUY FUERTE	4 FUERTE	3 NOTABLE	2 LIMITADO	1 DÉBIL

EAWS EUROPEAN AVALANCHE WARNING SERVICES

ICGC Institut Cartogràfic i Geològic de Catalunya

Servei Meteorològic de Catalunya meteo.cat

Boletín de peligro de aludes Prepirineu
Del 01/04/2026 al 02/04/2026

(Válido fuera pistas de esquí y zonas no controladas)

LIMITADO (2). NOTABLE (3) en el Moixeró por encima de 2.200 m.

Situación primaria

Nieve venteada

Distribución

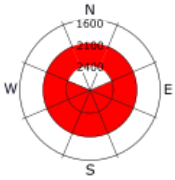

Tamaño

Origen

Tendencia

Situación secundaria

Nieve húmeda

Distribución

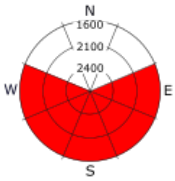

Tamaño

Origen

Tendencia

Estado del manto nivoso

El actual episodio de nevadas dejará cantidades inciertas de precipitación en el sector, que podrían llegar a los 30 cm en el Moixeró. El viento dará lugar a transporte y formará placas en diferentes sotaventos, prioritariamente los orientados a oeste, sur y este. Se tratará principalmente de placas duras pero suficientes delgadas para ser desencadenadas al paso de una sola persona o incluso de forma natural. Se encontrarán principalmente en sotaventos orientados a sur y este, pero también a zonas muy resguardadas del viento del resto de orientaciones como las canales más cerradas del Cadí. En caso de desprenderse se tratará de aludes de hasta tamaño 2, suficiente para enterrar a una persona. En momentos de ojeadas de sol también caerán purgas de nieve reciente húmeda o nieve húmeda, de forma natural y que afectarán principalmente a la nieve del último episodio; serán más frecuentes por la tarde. No se descarta algún alud de tamaño 2 en el norte del sector.

Distribución del manto nivoso

Aunque podemos encontrar nieve en cotas más bajas por el actual episodio de nevadas, el manto es continuo por encima de unos 1.700 ma terreno umbrío y de unos 1.900 ma solanas. Los espesores, aunque irregulares, rondan los 90-120 cm a 2.300 m.

Tendencia para las próximas 48-72h

Continuará el humedecimiento superficial de la nieve, con menor actividad de aludes de nieve húmeda ya que muchas vertientes habrán purgado. Menguará la actividad natural de aludes de placa. Peligro EN DESCENSO.

El próximo boletín será emitido el día 2026-04-02

5 MUY FUERTE	4 FUERTE	3 NOTABLE	2 LIMITADO	1 DÉBIL

EAWS EUROPEAN AVALANCHE WARNING SERVICES

ICGC Institut Cartogràfic i Geològic de Catalunya

Servei Meteorològic de Catalunya

Boletín de peligro de aludes Ter-Freser
Del 01/04/2026 al 02/04/2026

(Válido fuera pistas de esquí y zonas no controladas)

NOTABLE (3) por encima del nivel del bosque. LIMITADO (2) por debajo.

Situación primaria

Nieve venteada

Distribución

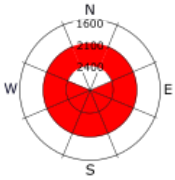

Tamaño

Origen

Tendencia

Situación secundaria

Nieve húmeda

Distribución

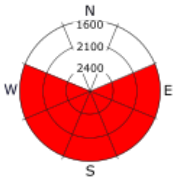

Tamaño

Origen

Tendencia

Estado del manto nivoso

La estabilidad empeora entre el miércoles y el jueves por el episodio de viento y nieve que está teniendo llco. Se acumularán unos 30 cm, muy afectados por el viento de norte y noroeste. En estas condiciones se formarán placas de viento a sotaventos orientados al sur, principalmente, que irán ganando grosor y siendo más inestables a lo largo del miércoles. Estas placas podrán caer al paso de una persona o, incluso, de forma natural, en especial la mañana del jueves. Se tratará de aludes de tamaño 2, suficiente para enterrar a una persona, aunque no se descartan mayores a sotaventos muy claros. En momentos de ojeadas de sol también caerán purgas de nieve reciente húmeda o nieve húmeda, de forma natural y que afectarán principalmente a la nieve del último episodio; serán más frecuentes por la tarde.

Distribución del manto nivoso

Hay algo de nieve en el suelo por encima de unos 1.400 m por el actual episodio de nevadas. El manto es esquiable a umbrías a partir de unos 1.800 m en umbrías. Los grosores son muy excedentarios para la época del año y en lugares no afectados por el viento oscilan entre 60-80 cm a unos 2.000 m, y más de 150 cm por encima de 2.400 m, muy variable por los efectos del viento.

Tendencia para las próximas 48-72h

Tendencia a la estabilización de las placas. El manto tenderá a humedecer pero los aludes húmedos serán menos habituales que el jueves. Peligro EN DESCENSO.

El próximo boletín será emitido el día 2026-04-02

5 MUY FUERTE	4 FUERTE	3 NOTABLE	2 LIMITADO	1 DÉBIL

EAWS EUROPEAN AVALANCHE WARNING SERVICES