BUTLLETÍ DEL PERILL D'ALLAUS DEL PRINCIPAT D'ANDORRA

Servei meteorològic nacional
Principat d'Andorra

Elaborat el 01/04/2026 16:00
Propera actualització 02/04/2026 a les 16h

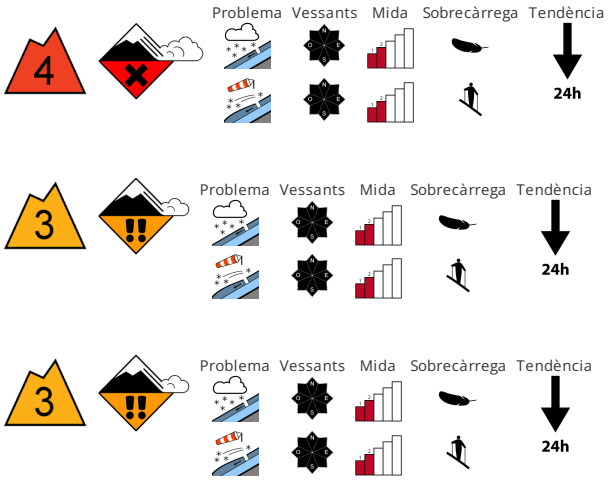

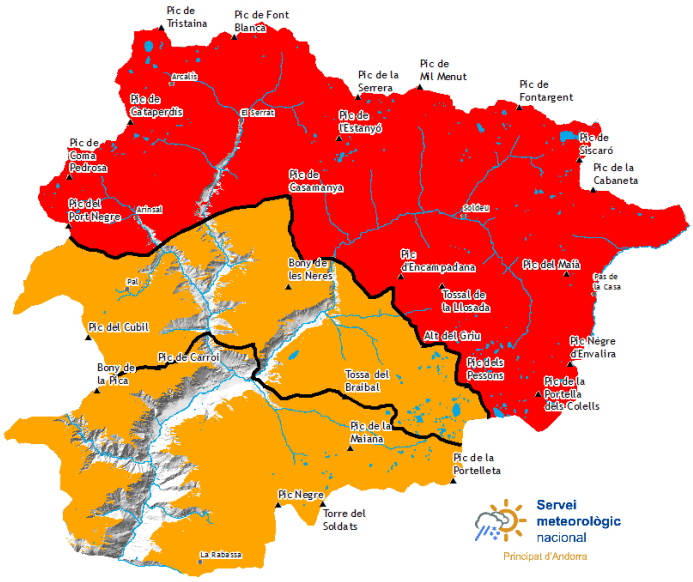

ESTABILITAT DEL MANTELL NIVAL

Les zones de sortida seran novament carregades a causa de la nevada i el vent. El vent amb ratxes fortes transportarà intensament la neu recent i la neu vella. La neu recent abundant i les plaques de vent poden desencadenar-se de manera natural en totes les orientacions. Aquestes són com a mínim de mida mitjana. Els indrets perillosos es troben en totes les orientacions prop del límit del bosc i també a l'entrada de canals i cubetes. Les condicions per les excursions són desfavorables. Els indrets perillosos són força freqüents i difícils de reconèixer amb mala visibilitat. Per ara, les activitats d'esports d'hivern fora de les pistes controlades són desaconsellables.

QUALITAT DE LA NEU

Fins al dijous caurà molta neu sobretot als al nord. El vent serà, prop de les carenes, fort. El mantell de neu roman extremadament variable en pocs metres de manera generalitzada. Prop de les carenes els gruixos de neu varien molt per la influència del vent.

GRUIXOS DEL MANTELL NIVAL FORA DE PISTA

Zona nord		Gruix neu		
Mantell Nival		1500m	2000m	2500m
N	1300 m	10 cm	150 cm	200 cm
S	1500 m	5 cm	100 cm	150 cm

Zona centre		Gruix neu		
Mantell Nival		1500m	2000m	2500m
N	1300 m	10 cm	150 cm	200 cm
S	1500 m	5 cm	100 cm	150 cm

Zona sud		Gruix neu		
Mantell Nival		1500m	2000m	2500m
N	1300 m	10 cm	120 cm	150 cm
S	1500 m	5 cm	60 cm	100 cm

Govern d'Andorra

EAWS EUROPEAN AVALANCHE WARNING SERVICES

Aquest butlletí ha estat elaborat seguint les normes i recomanacions de l'**European Avalanche Warning Services**, del qual el **Servei meteorològic Nacional** n'és membre

BUTLLETÍ DEL PERILL D'ALLAUS DEL PRINCIPAT D'ANDORRA

Servei meteorològic nacional
Principat d'Andorra

Informació detallada per espais naturals protegits

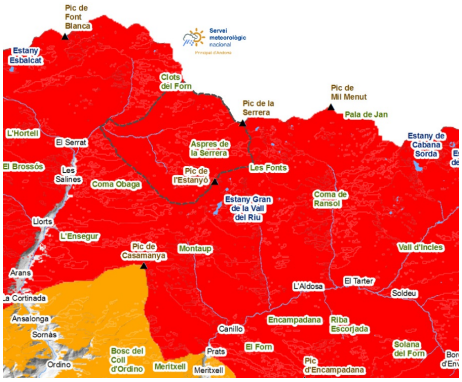

SORTENY

El vent ha modelat la neu recent i ho continuarà fent durant les properes hores. A causa de les nevades successives que sobretot afectaran el nord d´Andorra i del vent que encara bufarà fort en altura, es desaconsellen les activitats a la muntanya. A més, les condicions de vent i neu generaran torb i mala visibilitat.

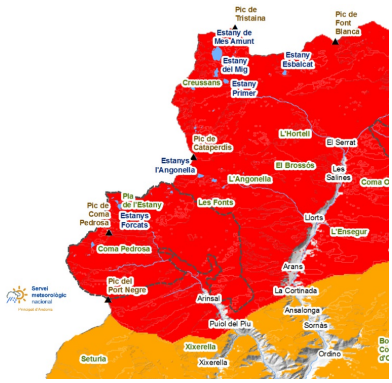

COMAPEDROSA

Es preveu que el vent encara sigui intens en altura durant els propers dies i es continuïn formant plaques de vent, ocultes sota la neu recent de dimecres i difícilment identificables. La situació és desfavorable per a les excursions.

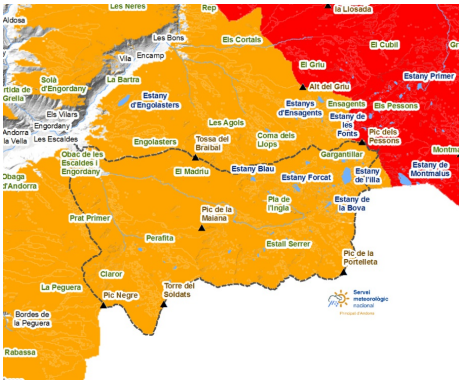

MADRIU-PERAFITA-CLAROR

La neu recent recula ràpid de les cotes baixes de la vall, però a cotes altes l´ambient encara és hivernal. El vent i la mala visibilitat ens han de fer renunciar a arribar a les collades més altes. Haurem de circular amb molta precaució, mantenint la distància de seguretat.

Govern d'Andorra

EAWS
EUROPEAN AVALANCHE WARNING SERVICES

Aquest butlletí ha estat elaborat seguint les normes i recomanacions de l'**European Avalanche Warning Services**, del qual el **Servei meteorològic Nacional** n'és membre

BUTLLETÍ DEL PERILL D'ALLAUS DEL PRINCIPAT D'ANDORRA

Servei meteorològic nacional
Principat d'Andorra

Gruixos de neu nova dels darrers dies (de les últimes 24h mesurat a les 06:00h UTC)

	28/03/2026	29/03/2026	30/03/2026	31/03/2026
FEDA (Central)	0 cm	0 cm	0 cm	0 cm
Engolasters - FEDA	7 cm	0 cm	0 cm	0 cm
Bony de les Neres	20 cm	0 cm	0 cm	3 cm
Les Fonts d'Arinsal	4 cm	0 cm	7 cm	1 cm
Perafita	0 cm	0 cm	0 cm	6 cm
Tossa Espiolets	34 cm	0 cm	4 cm	0 cm
Grau Roig - FEDA	16 cm	0 cm	1 cm	7 cm
Fontverd	17 cm	0 cm	0 cm	0 cm
Coll Ordino	25 cm	0 cm	0 cm	4 cm
Ransol - FEDA	18 cm	0 cm	3 cm	6 cm
Setúria	21 cm	0 cm	2 cm	95 cm
Caborreu	23 cm	0 cm	5 cm	1 cm
La Solana	30 cm	9 cm	6 cm	11 cm
Coll Pa	21 cm	0 cm	3 cm	7 cm
Envalira Antenes	27 cm	11 cm	2 cm	0 cm
Vall del Riu FEDA	10 cm	0 cm	1 cm	5 cm