MINISTERO DELLA DIFESA

meteomont
Servizio Nazionale di previsione neve e valanghe

EAWS EUROPEAN AVALANCHE WARNING SERVICES

CARABINIERI

AERONAUTICA MILITARE SERVIZIO METEOROLOGICO

# ALPI RETICHE

Bollettino Valanghe N. 392/2026 del 31/03/2026 ore 14.00
Validità 48 ore prossima emissione 01/04/2026

**A cura del Servizio METEOMONT dell'ARMA dei CARABINIERI**
**In collaborazione con Servizio Meteorologico dell'Aeronautica militare**

## SITUAZIONE alle 14:00 del 31/03/2026

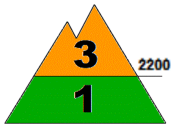


**SITUAZIONE TIPO: neve a debole coesione e vento.**




**SITUAZIONE TIPO: passaggio da poca a molta neve.**

| Quota neve (mslm) | Nord | Sud |
|---|---|---|
| | 1400 - 1800 | 1800 - 2500 |

| Altezza Neve (cm) | Neve al suolo | Neve Fresca | Quota (mslm) |
|---|---|---|---|
| | 68 | 0 | 2582 |
| | 55-65 | 0 | 2000 |

**VALANGHE OSSERVATE: Nessuna valanga.**

## PREVISIONI 01/04/2026

## GRADO DI PERICOLO: MODERATO 2

## SITUAZIONE TIPO: neve a debole coesione e vento.

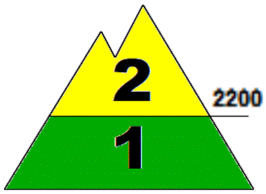


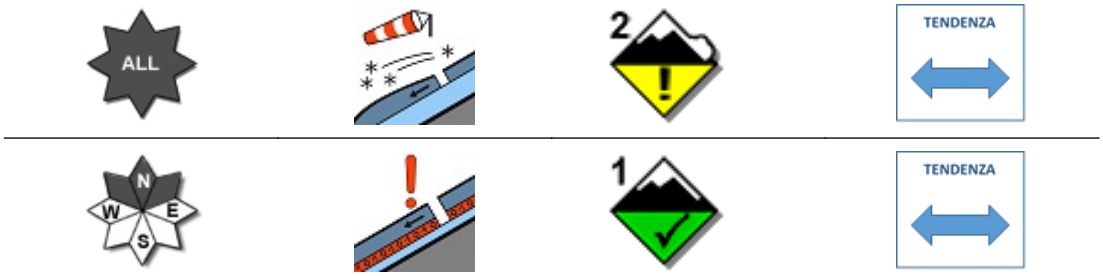


## SITUAZIONE TIPO: passaggio da poca a molta neve.

**MANTO NEVOSO: La stabilità del manto nevoso è scarsa su alcuni punti (aree) per tutte le esposizioni al di sopra di 2200 mslm, possibili valanghe di dimensioni medie.**
**La stabilità del manto nevoso è buona su alcuni punti (aree) per versanti settentrionali al di sotto di 2200 mslm, possibili valanghe di dimensioni piccole.**

## AVVERTENZE

A seguito dell'attività eolica registrata sono da evitare le zone di accumulo, conche, canaloni, cambi di pendenza e pendii sotto vento in genere.

## SCALA EUROPEA DEL GRADO DI PERICOLO VALANGHE

## LEGENDA PROBLEMA

**Bollettino realizzato su scala sinottica-regionale (standard EAWS). La sua valutazione non può escludere in alcun modo la necessità di una seria e capace valutazione locale del pericolo (singolo pendio) che può essere anche sensibilmente diverso. Le previsioni meteorologiche sono relative all'orario UTC (per l'Italia +1 in inverno e +2 in estate).**

**Bollettino sottoposto a processi di: Acquisizione e controllo del C-Sifa e della rete di Osservatori e Esperti - Validazione del Previsore di turno - Certificazione della Sezione Meteomont.**

MINISTERO DELLA DIFESA

meteomont
Servizio Nazionale di previsione neve e valanghe

EAWS EUROPEAN AVALANCHE WARNING SERVICES

CARABINIERI

# ALPI RETICHE

## PREVISIONE METEO

| Quota | | 01/04/2026 h6:00 | 01/04/2026 h12:00 | 01/04/2026 h18:00 |
|---|---|---|---|---|
| 1000 | Venti | 02 Nodi da Nord | 01 Nodi da Nord | 01 Nodi da Nord |
| | Temperature | -07 °C | -03 °C | -02 °C |
| | Temp.percepita | -7 °C | -3 °C | -2 °C |
| 2000 | Venti | 02 Nodi da Nord | 01 Nodi da Nord | 01 Nodi da Nord |
| | Temperature | -07 °C | -03 °C | -02 °C |
| | Temp.percepita | -7 °C | -3 °C | -2 °C |
| 3000 | Venti | 06 Nodi da N-Est | 05 Nodi da N-Est | 04 Nodi da Est |
| | Temperature | -13 °C | -10 °C | -08 °C |
| | Temp.percepita | -19 °C | -15 °C | -12 °C |
| Zero termico | | 0900-1100 m. | 1400-1600 m. | 1500-1700 m. |
| Fenomeno | | — | — | — |
| Stato del cielo | | | | |

## LEGENDA FENOMENI

— Assenza Fenomeni · Nebbia · Foschia · Pioggia debole · Pioggia moderata · Pioggia forte · Temporali

Nevicata debole · Nevicata moderata · Nevicata forte

## STATO DEL CIELO

Sereno · Poco nuvoloso · Nuvoloso · Molto nuvoloso · Coperto

## Parametri meteonivometrici registrati presso i campi di rilevamento il 31/03/2026.

| Località | Comune | Quota (m.s.l.m.) | Altezza neve (cm) | Neve caduta nelle 24 ore (cm) | Temp. Min (°C) | Temp. Max (°C) | Condizioni del tempo |
|---|---|---|---|---|---|---|---|
| SPONDA | Livigno (SO) | 2150 | 59 | 4 | -13 | -2 | Assenza di precipitazioni |
| VALAR | Valdidentro (SO) | 1930 | 66 | Tracce di neve | -6 | +1 | Assenza di precipitazioni |
| DOSSO DEL VALLONE | Valfurva (SO) | 2582 | 68 | 0 | -12 | -2 | Nevicata debole continua |
| ALPE PALU' | Chiesa in Valmalenco (SO) | 2010 | 62 | 1 | -8 | +2 | Assenza di precipitazioni |
| COLONIA VIGILI | Ponte di Legno (BS) | 1640 | 20 | 0 | -6 | +9 | Assenza di precipitazioni |
| MONTICELLI DEL TONALE * | Vermiglio (TN) | 2406 | 76 | 0 | N.P. | N.P. | Assenza di precipitazioni |

(*) Rilievi fuori campo

**L'INFORMAZIONE E' PREVENZIONE - LEGGI L'ATTUALE GRADO DI PERICOLO VALANGHE!**

IL CAPO DEL CENTRO NAZIONALE METEOMONT
(Ten. Col. RFI Emanuela Gini)
FIRMA AUTOGRAFA OMESSA AI SENSI
DELL'ART.3 DEL D.LGS N.39/1993

Bollettino realizzato su scala sinottica-regionale (standard EAWS). La sua valutazione non può escludere in alcun modo la necessità di una seria e capace valutazione locale del pericolo (singolo pendio) che può essere anche sensibilmente diverso. Le previsioni meteorologiche sono relative all'orario UTC (per l'Italia +1 in inverno e +2 in estate).