MINISTERO DELLA DIFESA

meteomont
Servizio Nazionale di previsione neve e valanghe

EAWS EUROPEAN AVALANCHE WARNING SERVICES

CARABINIERI

ALPI OROBICHE

Bollettino Valanghe N. 391/2026 del 01/04/2026 ore 14.00
Validità 48 ore prossima emissione 02/04/2026

A cura del Servizio METEOMONT dell'ARMA dei CARABINIERI
In collaborazione con Servizio Meteorologico dell'Aeronautica militare

SITUAZIONE alle 14:00 del 01/04/2026

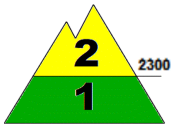

SITUAZIONE TIPO: neve a debole coesione e vento.

SITUAZIONE TIPO: nessuna situazione tipo evidente.

Quota neve (mslm)	Nord	Sud
	1600 - 1800	2100 - 2200

Altezza Neve (cm)	Neve al suolo	Neve Fresca	Quota (mslm)
	150	0	2080
	58	0	1760

VALANGHE OSSERVATE: Nessuna valanga.

PREVISIONI 02/04/2026

GRADO DI PERICOLO: MODERATO 2

SITUAZIONE TIPO: passaggio da poca a molta neve.

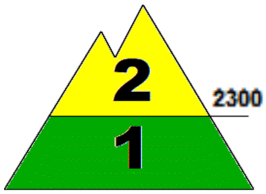

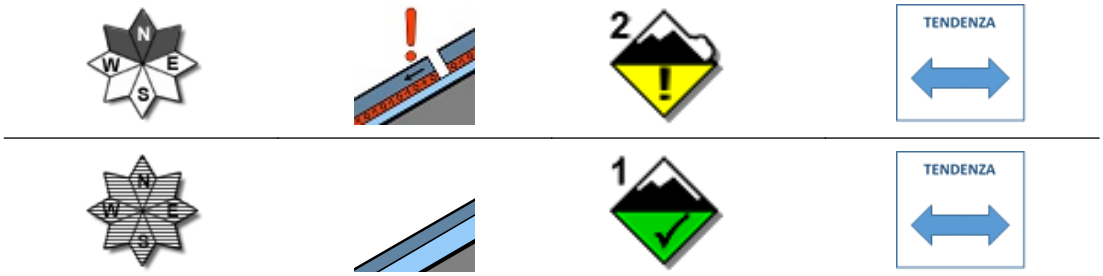

SITUAZIONE TIPO: nessuna situazione tipo evidente.

MANTO NEVOSO: La stabilità del manto nevoso è scarsa su alcuni punti (aree) per versanti settentrionali al di sopra di 2300 mslm, possibili valanghe di dimensioni medie.
La stabilità del manto nevoso è buona su alcuni punti (aree) per isolati pendii al di sotto di 2300 mslm, possibili valanghe di dimensioni piccole.

AVVERTENZE

A seguito dell'attività eolica registrata sono da evitare le zone di accumulo, conche, canaloni, cambi di pendenza e pendii sotto vento in genere.

SCALA EUROPEA DEL GRADO DI PERICOLO VALANGHE

5 - MOLTO FORTE *4 - FORTE* *3 - MARCATO* *2 - MODERATO* *1 - DEBOLE* *NO NEVE* *NO INFO*

LEGENDA PROBLEMA

NEVE FRESCA *LASTRONI DA VENTO* *STRATI DEBOLI PERSISTENTI* *NEVE BAGNATA* *SLITTAMENTO* *CORNICI* *NESSUN PROBLEMA VALANGHIVO EVIDENTE* *NO_INFO*

Bollettino realizzato su scala sinottica-regionale (standard EAWS). La sua valutazione non può escludere in alcun modo la necessità di una seria e capace valutazione locale del pericolo (singolo pendio) che può essere anche sensibilmente diverso. Le previsioni meteorologiche sono relative all'orario UTC (per l'Italia +1 in inverno e +2 in estate).

MINISTERO DELLA DIFESA

meteomont
Servizio Nazionale di previsione neve e valanghe

EAWS EUROPEAN AVALANCHE WARNING SERVICES

CARABINIERI

ALPI OROBICHE

PREVISIONE METEO

Quota		02/04/2026 h6:00	02/04/2026 h12:00	02/04/2026 h18:00
1000	Venti	03 Nodi da Nord	01 Nodi da N-Est	04 Nodi da Nord
	Temperature	-02 °C	+03 °C	+00 °C
	Temp.percepita	-4 °C	3 °C	-3 °C
2000	Venti	03 Nodi da Nord	03 Nodi da Nord	07 Nodi da Nord
	Temperature	-01 °C	+02 °C	+00 °C
	Temp.percepita	-3 °C	0 °C	-4 °C
3000	Venti	04 Nodi da Nord	07 Nodi da N-Est	07 Nodi da N-Est
	Temperature	-07 °C	-06 °C	-06 °C
	Temp.percepita	-11 °C	-11 °C	-11 °C
Zero termico		1400-1600 m.	2100-2300 m.	1500-1700 m.
Fenomeno		—	—	—
Stato del cielo				

LEGENDA FENOMENI

— Assenza Fenomeni · Nebbia · Foschia · Pioggia debole · Pioggia moderata · Pioggia forte · Temporali

Nevicata debole · Nevicata moderata · Nevicata forte

STATO DEL CIELO

Sereno · Poco nuvoloso · Nuvoloso · Molto nuvoloso · Coperto

Parametri meteonivometrici registrati presso i campi di rilevamento il 01/04/2026.

Località	Comune	Quota (m.s.l.m.)	Altezza neve (cm)	Neve caduta nelle 24 ore (cm)	Temp. Min (°C)	Temp. Max (°C)	Condizioni del tempo
QUARTA BAITA	Foppolo (BG)	1760	58	0	-4	-3	Assenza di precipitazioni
CIMA BIANCA	Colere (BG)	2080	150	0	-8	-6	Assenza di precipitazioni

(*) Rilievi fuori campo

L'INFORMAZIONE E' PREVENZIONE - LEGGI L'ATTUALE GRADO DI PERICOLO VALANGHE!

IL CAPO DEL CENTRO NAZIONALE METEOMONT
(Ten. Col. RFI Emanuela Gini)
FIRMA AUTOGRAFA OMESSA AI SENSI
DELL'ART.3 DEL D.LGS N.39/1993