MINISTERO DELLA DIFESA

meteomont
Servizio Nazionale di previsione neve e valanghe

EAWS EUROPEAN AVALANCHE WARNING SERVICES

CARABINIERI

AERONAUTICA MILITARE SERVIZIO METEOROLOGICO

TERMINILLO MONTI REATINI E LAGA OVEST

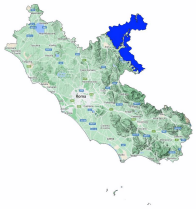

Bollettino Valanghe N. 332/2026 del 31/03/2026 ore 14.00
Validità 48 ore prossima emissione 01/04/2026

A cura del Servizio METEOMONT dell'ARMA dei CARABINIERI
In collaborazione con Servizio Meteorologico dell'Aeronautica militare

SITUAZIONE alle 14:00 del 31/03/2026

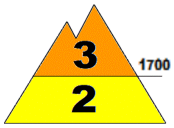

SITUAZIONE TIPO: neve a debole coesione e vento.

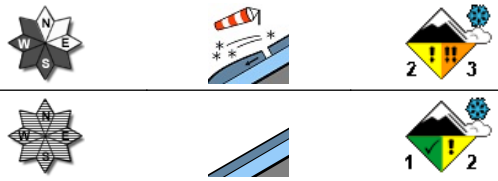

SITUAZIONE TIPO: nessuna situazione tipo evidente.

Quota neve (mslm)	Nord	Sud
	1000	1000

Altezza Neve (cm)	Neve al suolo	Neve Fresca	Quota (mslm)
	110	013	1760
	024	015	1350

VALANGHE OSSERVATE: Nessuna valanga.

PREVISIONI 01/04/2026

GRADO DI PERICOLO: MARCATO 3

SITUAZIONE TIPO: neve a debole coesione e vento.

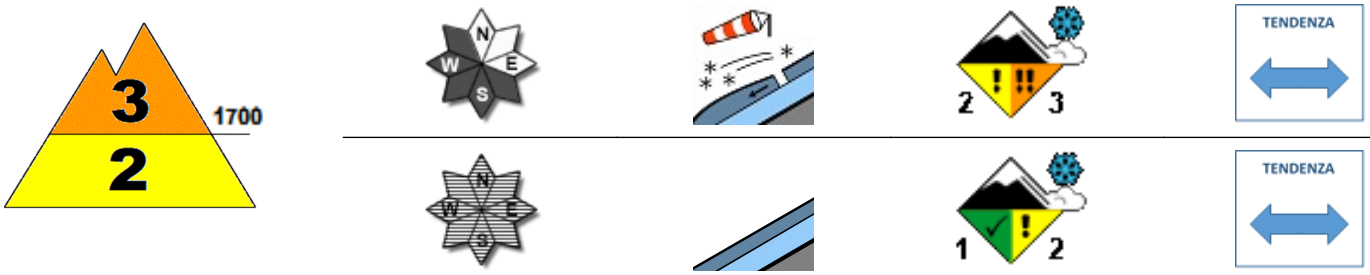

SITUAZIONE TIPO: nessuna situazione tipo evidente.

MANTO NEVOSO: La stabilità del manto nevoso è scarsa su alcuni punti (aree) per versanti da sud est a nord ovest al di sopra di 1700 mslm, possibili valanghe di dimensioni grandi.
La stabilità del manto nevoso è discreta su alcuni punti (aree) per isolati pendii al di sotto di 1700 mslm, possibili valanghe di dimensioni medie.

AVVERTENZE

A seguito dell'attività eolica registrata sono da evitare le zone di accumulo, conche, canaloni, cambi di pendenza e pendii sotto vento in genere.

SCALA EUROPEA DEL GRADO DI PERICOLO VALANGHE

LEGENDA PROBLEMA

Bollettino realizzato su scala sinottica-regionale (standard EAWS). La sua valutazione non può escludere in alcun modo la necessità di una seria e capace valutazione locale del pericolo (singolo pendio) che può essere anche sensibilmente diverso. Le previsioni meteorologiche sono relative all'orario UTC (per l'Italia +1 in inverno e +2 in estate).

MINISTERO DELLA DIFESA

meteomont
Servizio Nazionale di previsione neve e valanghe

EAWS EUROPEAN AVALANCHE WARNING SERVICES

CARABINIERI

TERMINILLO MONTI REATINI E LAGA OVEST

PREVISIONE METEO

Quota		01/04/2026 h6:00	01/04/2026 h12:00	01/04/2026 h18:00
1000	Venti	*14 Nodi da N-Est*	*11 Nodi da N-Est*	*08 Nodi da N-Est*
	Temperature	*-03 °C*	*-01 °C*	*-01 °C*
	Temp.percepita	*-10 °C*	*-7 °C*	*-6 °C*
2000	Venti	*29 Nodi da N-Est*	*24 Nodi da N-Est*	*22 Nodi da N-Est*
	Temperature	*-06 °C*	*-04 °C*	*-04 °C*
	Temp.percepita	*-17 °C*	*-13 °C*	*-13 °C*
3000	Venti	*27 Nodi da Est*	*26 Nodi da Est*	*22 Nodi da Est*
	Temperature	*-08 °C*	*-06 °C*	*-07 °C*
	Temp.percepita	*-19 °C*	*-16 °C*	*-17 °C*
Zero termico		*1000-1200 m.*	*1300-1500 m.*	*1200-1400 m.*
Fenomeno				
Stato del cielo				

LEGENDA FENOMENI

Assenza Fenomeni — *Nebbia* — *Foschia* — *Pioggia debole* — *Pioggia moderata* — *Pioggia forte* — *Temporali*

Nevicata debole — *Nevicata moderata* — *Nevicata forte*

STATO DEL CIELO

Sereno — *Poco nuvoloso* — *Nuvoloso* — *Molto nuvoloso* — *Coperto*

Parametri meteonivometrici registrati presso i campi di rilevamento il 31/03/2026.

Località	*Comune*	*Quota (m.s.l.m.)*	*Altezza neve (cm)*	*Neve caduta nelle 24 ore (cm)*	*Temp. Min (°C)*	*Temp. Max (°C)*	*Condizioni del tempo*
PESCHIERE	Amatrice (RI)	1270	9	1	+1	+12	Nevicata debole continua
M. CAIDURO	Cittareale (RI)	1300	8	3	-1	+9	Assenza di precipitazioni
VALLONINA	Leonessa (RI)	1350	24	15	-2	+14	Nevicata moderata
GIRO DELL'ANELLO - VILLA CHIGI *	Rieti (RI)	1760	110	13	-4	-2	Rovescio a grandine o neve arrotondata
PRATO DEI SASSI *	Leonessa (RI)	1872	205	19	N.P.	N.P.	Scaccianeve (tormenta) sulla stazione

(*) Rilievi fuori campo

L'INFORMAZIONE E' PREVENZIONE - LEGGI L'ATTUALE GRADO DI PERICOLO VALANGHE!

IL CAPO DEL CENTRO NAZIONALE METEOMONT
(Ten. Col. RFI Emanuela Gini)
FIRMA AUTOGRAFA OMESSA AI SENSI
DELL'ART.3 DEL D.LGS N.39/1993

Bollettino realizzato su scala sinottica-regionale (standard EAWS). La sua valutazione non può escludere in alcun modo la necessità di una seria e capace valutazione locale del pericolo (singolo pendio) che può essere anche sensibilmente diverso. Le previsioni meteorologiche sono relative all'orario UTC (per l'Italia +1 in inverno e +2 in estate).