Bulletin d'estimation du risque d'avalanche
(valable en dehors des pistes balisées et ouvertes)

MASSIF : Haut-Var Haut-Verdon

Rédigé le mercredi 1 avril 2026 à 15h

Estimation des risques pour le : JEUDI 02 AVRIL

MANTEAU NEIGEUX BIEN STABILISÉ

1

1

N O E S

Indice de risque faible.

Départs spontanés : peu probables

Déclenchements provoqués : très rares

Indices de risque : 5 très fort - 4 fort - 3 marqué - 2 limité - 1 faible -- En noir : les pentes les plus dangereuses

Stabilité du manteau neigeux

Situation avalancheuse typique : pas de situation prédominante

Déclenchements provoqués : le manteau neigeux est bien stable. Les instabilités ne concernent éventuellement que de rares pentes de haute altitude, elles sont bien identifiables et restent de petite taille.

Départs spontanés : peu probables. Le vent faible et la masse d'air frais en altitude limitent l'activité naturelle.

Qualité de la neige

Enneigement plutôt excédentaire pour une fin mars.
Hauteurs de neige observées : vers 2000 m, 175 cm dans le vallon de Valdemars, 114 cm à la Sanguinière dans le Haut Var.

Enneigement skiable : vers 1500 m en terrain favorable en ubacs, 1900/2000 m en adrets peu pentus.

État de la neige en surface : manteau neigeux printanier bien regelé en adrets, fortement durci par le vent en altitude. Humidification superficielle au soleil en journée.

Aperçu météo pour le jeudi 02 avril

	nuit	matin	après-midi	soir

Ensoleillé, vent faible, hausse des température, 6°C à 2000 m l'après-midi

Pluie-Neige				
Iso 0 °C	1 700 m	2 300 m	2 400 m	2 300 m
Vent 2000 m	35 km/h	20 km/h	20 km/h	20 km/h
Vent 3000 m	50 km/h	25 km/h	25 km/h	20 km/h

Épaisseur de neige hors-piste

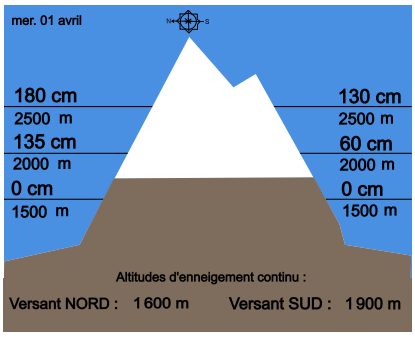

Précipitations à 1800 m

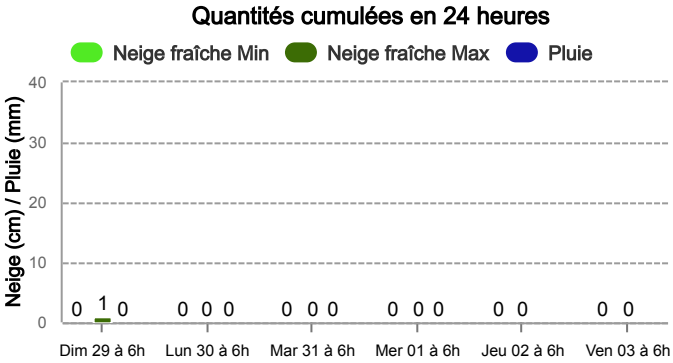

Tendance du vendredi 03 avril

1

Indice de risque faible

Peu d'évolution de la situation nivologique.
Maintien d'un risque faible

Pour consulter la vigilance en cours, veuillez vous rendre sur le site https://vigilance.meteofrance.fr/fr

Météo-France - 73 avenue de Paris, 94165 Saint-Mandé cedex - Contact : contact@meteo.fr

Rédigé par Météo-France avec la contribution des observateurs du réseau nivo-météorologiques. Partenariat : ANMSM (Maires de Stations de Montagne), DSF (Domaines Skiables de France), ADSP (Directeurs de Pistes et de la Sécurité des Stations de Sports d'Hiver) et autres acteurs de la montagne.

Bulletin neige & avalanches par téléphone au
0 892 68 10 20 Service 0,35 € / min + prix appel

RÉPUBLIQUE FRANÇAISE
Liberté Égalité Fraternité

METEO FRANCE
À VOS CÔTÉS, DANS UN CLIMAT QUI CHANGE

Bulletin d'estimation du risque d'avalanche

(valable en dehors des pistes balisées et ouvertes)

MASSIF : Haut-Var Haut-Verdon

Rédigé le mercredi 1 avril 2026 à 15h

Conditions nivo-météo des 7 derniers jours

	jeu. 26/03				ven. 27/03				sam. 28/03				dim. 29/03				lun. 30/03				mar. 31/03				mer. 01/04			
	03h	09h	15h	21h	03h	09h	15h	21h	03h	09h	15h	21h	03h	09h	15h	21h	03h	09h	15h	21h	03h	09h	15h	21h	03h	09h	15h	21h
Météo																												
Vent (km/h)	100	80	70	60	65	50	40	30	25	25	25	20	45	50	35	25	30	55	75	120	80	40	40	75	80	60	50	45
à 3000m																												
Vent (km/h)	85	65	60	50	45	40	25	15	10	10	20	15	20	45	25	15	15	20	20	80	45	30	35	65	70	45	40	35
à 2000m																												

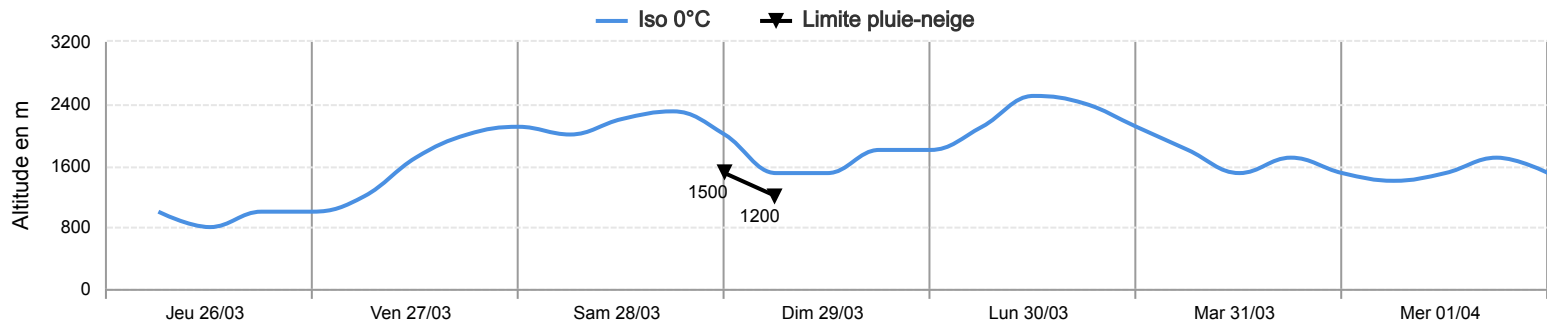

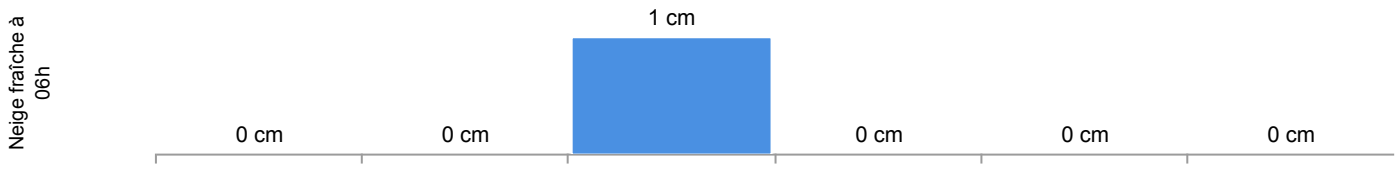

Risque d'avalanche	jeu. 26/03	ven. 27/03	sam. 28/03	dim. 29/03	lun. 30/03	mar. 31/03	mer. 01/04
	3	2	2	2	2	2	2

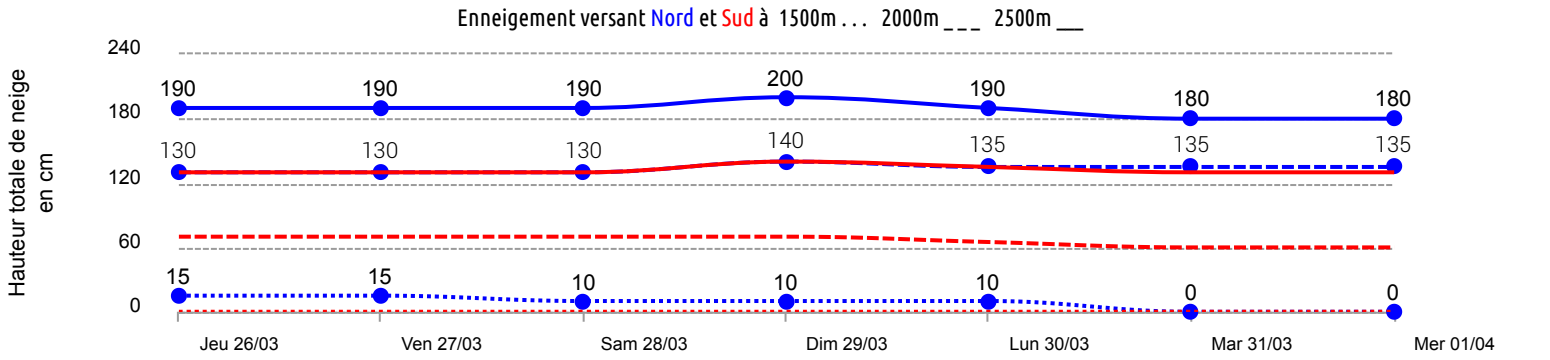

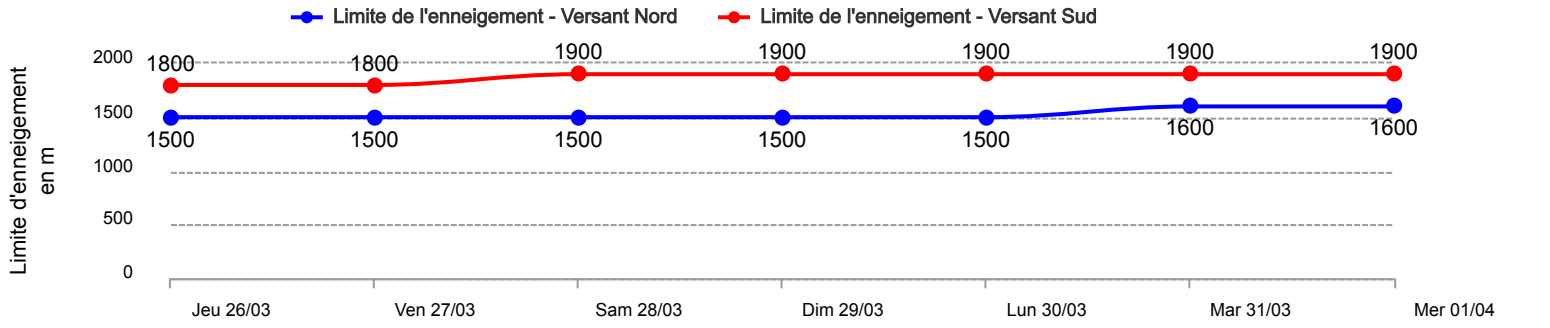

Pour consulter la vigilance en cours, veuillez vous rendre sur le site https://vigilance.meteofrance.fr/fr

Météo-France - 73 avenue de Paris, 94165 Saint-Mandé cedex - Contact : contact@meteo.fr

Rédigé par Météo-France avec la contribution des observateurs du réseau nivo-météorologiques. Partenariat : ANMSM (Maires de Stations de Montagne), DSF (Domaines Skiables de France), ADSP (Directeurs de Pistes et de la Sécurité des Stations de Sports d'Hiver) et autres acteurs de la montagne.

Bulletin neige & avalanches par téléphone au
0 892 68 10 20
Service 0,35 € / min + prix appel