Bulletin d'estimation du risque d'avalanche
(valable en dehors des pistes balisées et ouvertes)

MASSIF : Ubaye

Rédigé le mercredi 1 avril 2026 à 15h

Estimation des risques pour le : JEUDI 02 AVRIL

RARES INSTABILITÉS EN ALTITUDE DANS LA NEIGE VENTÉE, NOTAMMENT PRÈS DE L'ITALIE

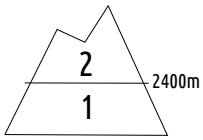

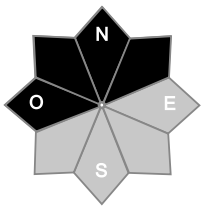

Au-dessus de 2400m indice de risque limité, plus bas indice faible.

Départs spontanés : peu probables

Déclenchements provoqués : rares et peu volumineux dans la neige ventée

Indices de risque : 5 très fort - 4 fort - 3 marqué - 2 limité - 1 faible -- En noir : les pentes les plus dangereuses

Stabilité du manteau neigeux

Situation avalancheuse typique : neige ventée

Déclenchements provoqués : instabilités limitées à de rares pentes d'altitude. Possibles surtout en versants de nord et ouest au-dessus de 2400 m environ, parfois loin des crêtes, ces instabilités sont un peu plus fréquentes en Haute Ubaye, près de l'Italie. Un seul skieur peut encore les déclencher, à l'origine de départs d'avalanches de petite taille. Elles sont généralement bien identifiables depuis la surface.

Départs spontanés : peu probables. Le vent faible et la masse d'air frais en altitude limitent l'activité naturelle.

Qualité de la neige

Enneigement proche des normales pour un début avril.
Hauteurs de neige observées : 73 cm à la Nivôse de Restefond à 2550 m dans un secteur relativement peu enneigé et hiver, encore 90 cm en fond de vallée vers Maljasset à 2000 m.

Enneigement skiable : vers 1600 m en terrain favorable en ubacs, 2000/2100 m en adrets peu pentus.

État de la neige en surface : manteau neigeux printanier bien regelé en adrets, fortement durci par le vent en altitude. Humidification superficielle au soleil en journée.

Aperçu météo pour le jeudi 02 avril

	nuit	matin	après-midi	soir
Ensoleillé, vent faible, hausse des température, 6°C à 2000 m l'après-midi				
Pluie-Neige				
Iso 0 °C	1 800 m	2 200 m	2 400 m	2 200 m
Vent 2000 m	25 km/h	15 km/h	20 km/h	15 km/h
Vent 3000 m	45 km/h	25 km/h	20 km/h	20 km/h

Épaisseur de neige hors-piste

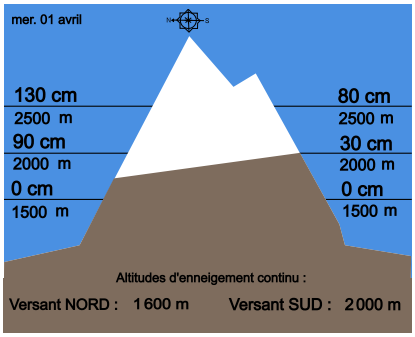

Précipitations à 1800 m

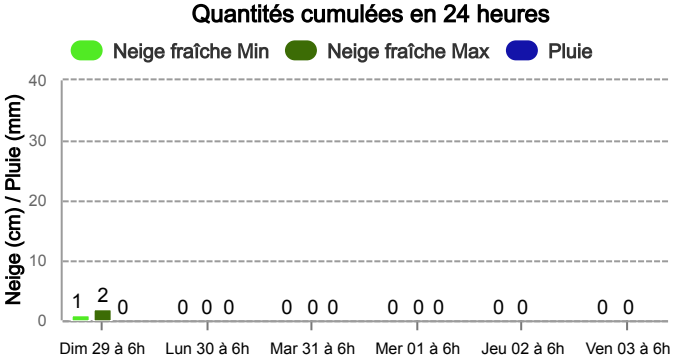

Tendance du vendredi 03 avril

Indice de risque faible

Poursuite de la stabilisation du manteau neigeux. Instabilités devenant très résiduelles dans la neige ventée. Risque faible

Pour consulter la vigilance en cours, veuillez vous rendre sur le site https://vigilance.meteofrance.fr/fr

Météo-France - 73 avenue de Paris, 94165 Saint-Mandé cedex - Contact : contact@meteo.fr

Rédigé par Météo-France avec la contribution des observateurs du réseau nivo-météorologiques. Partenariat : ANMSM (Maires de Stations de Montagne), DSF (Domaines Skiables de France), ADSP (Directeurs de Pistes et de la Sécurité des Stations de Sports d'Hiver) et autres acteurs de la montagne.

Bulletin neige & avalanches par téléphone au
0 892 68 10 20 Service 0,35 € / min + prix appel

RÉPUBLIQUE FRANÇAISE
Liberté Égalité Fraternité

METEO FRANCE
À VOS CÔTÉS, DANS UN CLIMAT QUI CHANGE

Bulletin d'estimation du risque d'avalanche

(valable en dehors des pistes balisées et ouvertes)

MASSIF : Ubaye

Rédigé le mercredi 1 avril 2026 à 15h

Conditions nivo-météo des 7 derniers jours

	jeu. 26/03				ven. 27/03				sam. 28/03				dim. 29/03				lun. 30/03				mar. 31/03				mer. 01/04			
	03h	09h	15h	21h	03h	09h	15h	21h	03h	09h	15h	21h	03h	09h	15h	21h	03h	09h	15h	21h	03h	09h	15h	21h	03h	09h	15h	21h
Météo																												
Vent (km/h)	100	80	70	60	60	50	40	30	25	25	25	25	30	40	30	15	30	50	75	120	65	50	50	40	45	45	55	55
à 3000m																												
Vent (km/h)	80	60	50	50	45	35	20	10	10	10	20	15	20	40	25	15	10	25	45	80	50	35	35	40	45	45	40	30
à 2000m																												

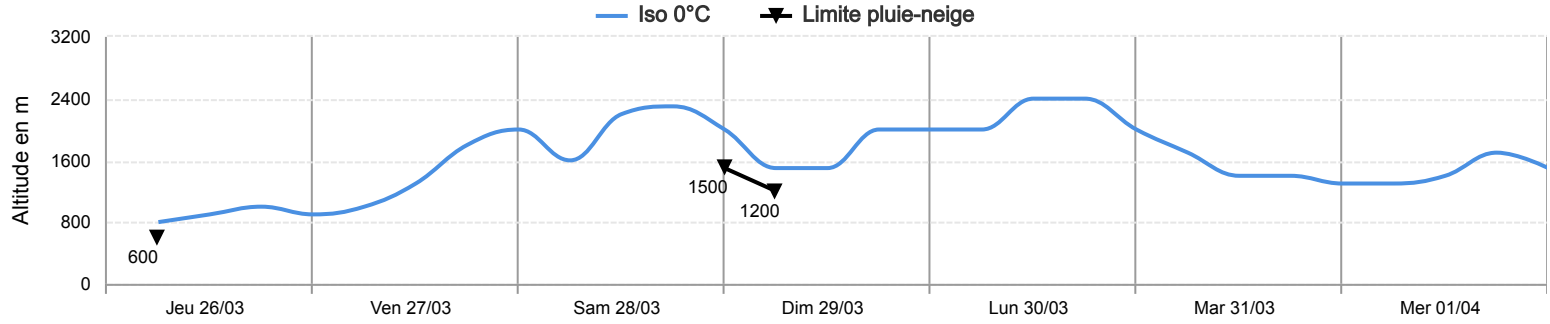

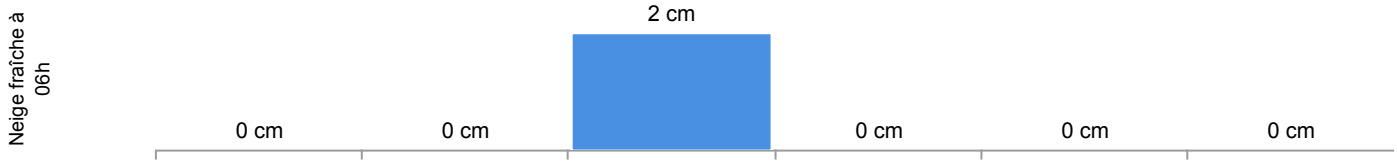

Risque d'avalanche	jeu. 26/03	ven. 27/03	sam. 28/03	dim. 29/03	lun. 30/03	mar. 31/03	mer. 01/04
	3	2	2	2	2	2	2

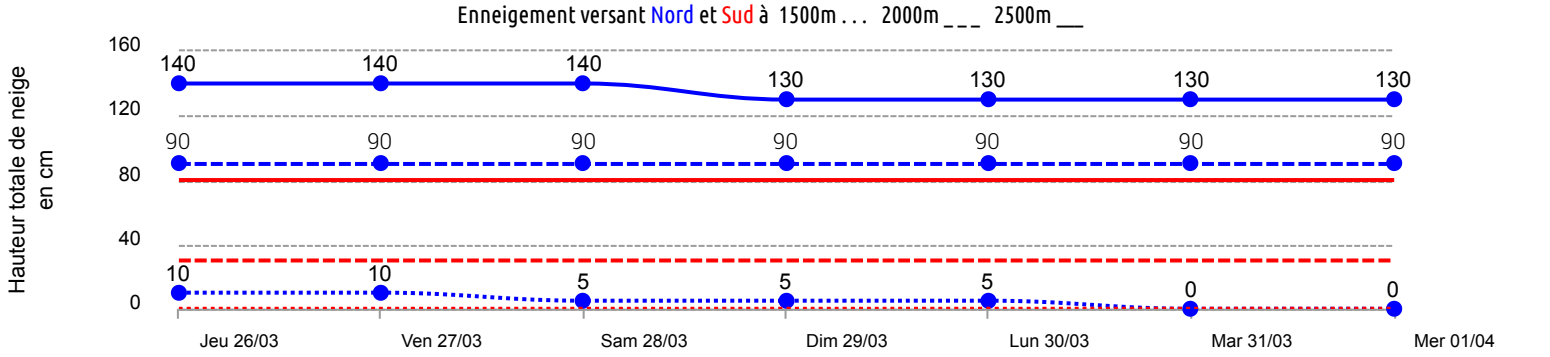

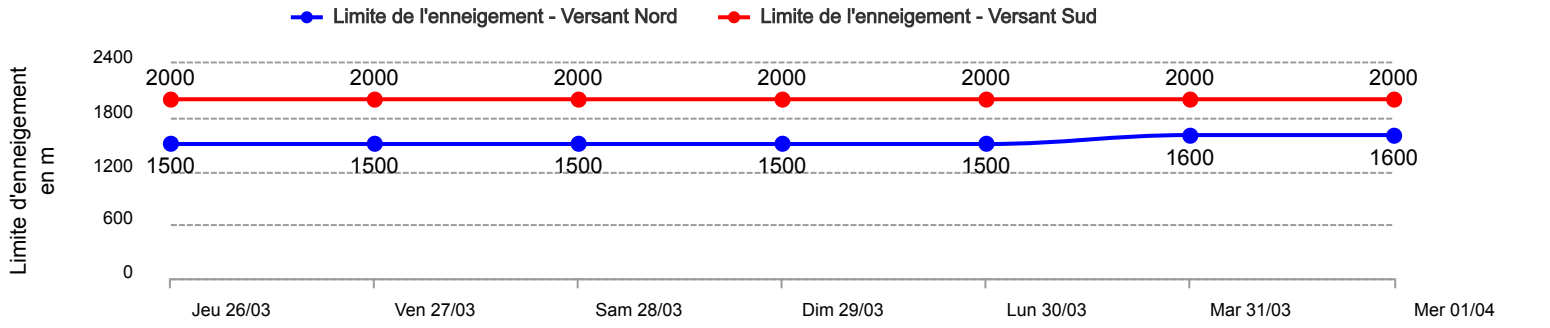

Pour consulter la vigilance en cours, veuillez vous rendre sur le site https://vigilance.meteofrance.fr/fr

Météo-France - 73 avenue de Paris, 94165 Saint-Mandé cedex - Contact : contact@meteo.fr

Bulletin neige & avalanches par téléphone au

0 892 68 10 20 Service 0,35 € / min + prix appel

Rédigé par Météo-France avec la contribution des observateurs du réseau nivo-météorologiques. Partenariat : ANMSM (Maires de Stations de Montagne), DSF (Domaines Skiables de France), ADSP (Directeurs de Pistes et de la Sécurité des Stations de Sports d'Hiver) et autres acteurs de la montagne.