RÉPUBLIQUE FRANÇAISE
Liberté Égalité Fraternité

METEO FRANCE
À VOS CÔTÉS, DANS UN CLIMAT QUI CHANGE

Bulletin d'estimation du risque d'avalanche
(valable en dehors des pistes balisées et ouvertes)
MASSIF : Capcir Puymorens

Rédigé le mercredi 1 avril 2026 à 16h

Estimation des risques pour le : JEUDI 02 AVRIL

ÉPISODE NEIGEUX CONSÉQUENT ET RISQUE DE DÉCLENCHEMENT SKIEUR EN NETTE HAUSSE.

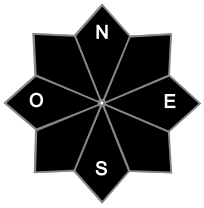

Indice de risque fort.

Départs spontanés : Avalanches de neige récente dans les couloirs chargés par le vent, dans la nuit et en matinée surtout, cumuls à surveiller.

Déclenchements provoqués : Dans toutes les pentes raides, plaques à vent avec neige roulée en sous couche fragile potentielle.

Indices de risque : 5 très fort - 4 fort - 3 marqué - 2 limité - 1 faible -- En noir : les pentes les plus dangereuses

Stabilité du manteau neigeux

Situation avalancheuse typique : neige fraîche couche fragile persistante

Départs spontanés :
Sur les crêtes frontières avec l'ariège : Des départs ponctuels ou linéaires d'avalanches de neige fraiche sont attendus dans les pentes très raides en toutes orientations. Avalanches moyenne à grande, voire très grande en cas de cumuls dépassant les 60/70 cm.
Danger moindre secteur pic de Madres ou sur les secteurs plus proches de la Cerdagne.
Justification : Le vent de nord/nord ouest soutenu continue de former de grosses accumulations parfois loin des crêtes, et les chutes de neige conséquentes perdurent tout au long de la journée. Le danger concerne tous les versants (pas de stabilisation) et en particulier les pentes Est à Sud-Est.

Déclenchements provoqués :
De nombreuses structures de plaques facilement déclenchables sont présentes dans la neige récente et continuent de se former avec les nouvelles chutes et le vent turbulent.
Justification : manteau neigeux provisoirement très instable avec des sous-couches en neige roulée très répandues, notamment dans les versants froids.
Les accumulations les plus épaisses sont situées préférentiellement dans un large versant sud, mais pas uniquement. Elles sont difficilement détectables et en neige poudreuse tassée. Avalanches de taille moyenne ou grande en cas de déclenchements.
Observables : Quantité de neige fraiche, surface hétérogène travaillée par le vent, fissures devant les skis, "woomfs".

Autre :
Toujours une faible visibilité avec le mauvais temps qui perdure, froid sensible avec le vent, corniches très imposantes pour la saison sous les crêtes.

Qualité de la neige

Enneigement :
L'enneigement est excellent pour la saison. En altitude, les cumuls sont conséquents, mais les crêtes et sommets exposés au vent d'ouest à nord-ouest sont un peu plus dégarnis.
La tramontane qui souffle fort depuis déjà plusieurs jours a formé de grosses accumulations dans les versants Est.
Il est envisageable de chausser les skis vers 1400/1500 m mais on retrouvera une sous-couche permettant de progresser plus sereinement plutôt à partir de 1700/1800 m.

Qualité de la neige :
Jeudi matin, on devrait retrouver 20/30 cm de neige récente sur les secteurs du Puymorens ou vers le fond de la vallée du galbe, au-delà de 1800 m, 30/50 cm au-delà de 2000 m, et parfois 50/70 cm dans les quelques vallons d'altitude les plus exposés de haute montagne. Apport de 10/15 cm en journée jeudi.
En altitude, l'enneigement et la qualité de la neige seront hétérogènes sous l'action du vent soufflant depuis samedi, avec des zones d'accumulations où la neige fraîche et/ou récente reste localement légère et des zones proches des crêtes Ouest à Nord-Ouest pelées ou en neige dure, voire glacée.

Aperçu météo pour le jeudi 02 avril

	nuit	matin	après-midi	soir

Neige significative dans la nuit et en matinée, perdurant dans l'après-midi et au cours de la nuit suivante en faiblissant nettement.

Pluie-Neige	1 500 m	1 300 m	1 400 m	1 400 m
Iso 0 °C	1 800 m	1 900 m	2 100 m	1 900 m
Vent 2000 m	↘ 75 km/h	↘ 75 km/h	→ 80 km/h	↓ 80 km/h
Vent 3000 m	↘ 90 km/h	↘ 90 km/h	↘ 95 km/h	↘ 85 km/h

Pour consulter la vigilance en cours, veuillez vous rendre sur le site https://vigilance.meteofrance.fr/fr

Météo-France - 73 avenue de Paris, 94165 Saint-Mandé cedex - Contact : contact@meteo.fr

Rédigé par Météo-France avec la contribution des observateurs du réseau nivo-météorologiques. Partenariat : ANMSM (Maires de Stations de Montagne), DSF (Domaines Skiables de France), ADSP (Directeurs de Pistes et de la Sécurité des Stations de Sports d'Hiver) et autres acteurs de la montagne.

Bulletin neige & avalanches par téléphone au
0 892 68 10 20 Service 0,35 € / min + prix appel

Bulletin d'estimation du risque d'avalanche

(valable en dehors des pistes balisées et ouvertes)

MASSIF : Capcir Puymorens

Rédigé le mercredi 1 avril 2026 à 16h

Épaisseur de neige hors-piste

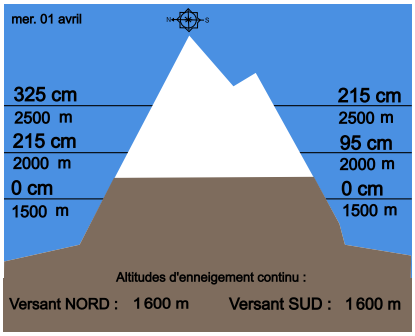

Précipitations à 1800 m

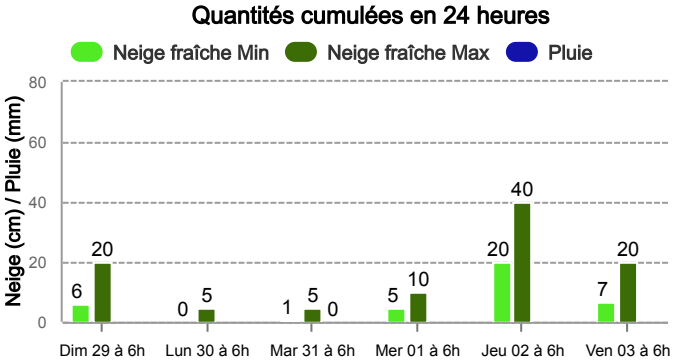

Tendance du vendredi 03 avril

Indice de risque fort

Maintien probable d'un risque fort (accident en matinée) avec éventuellement des départs en neige humide en fin de période.

Pour consulter la vigilance en cours, veuillez vous rendre sur le site https://vigilance.meteofrance.fr/fr

Météo-France - 73 avenue de Paris, 94165 Saint-Mandé cedex - Contact : contact@meteo.fr

Rédigé par Météo-France avec la contribution des observateurs du réseau nivo-météorologiques. Partenariat : ANMSM (Maires de Stations de Montagne), DSF (Domaines Skiables de France), ADSP (Directeurs de Pistes et de la Sécurité des Stations de Sports d'Hiver) et autres acteurs de la montagne.

Bulletin neige & avalanches par téléphone au

0 892 68 10 20 Service 0,35 € / min + prix appel

RÉPUBLIQUE FRANÇAISE
Liberté Égalité Fraternité

METEO FRANCE
À VOS CÔTÉS, DANS UN CLIMAT QUI CHANGE

Bulletin d'estimation du risque d'avalanche

(valable en dehors des pistes balisées et ouvertes)

MASSIF : Capcir Puymorens

Rédigé le mercredi 1 avril 2026 à 16h

Conditions nivo-météo des 7 derniers jours

	jeu. 26/03				ven. 27/03				sam. 28/03				dim. 29/03				lun. 30/03				mar. 31/03				mer. 01/04			
	03h	09h	15h	21h	03h	09h	15h	21h	03h	09h	15h	21h	03h	09h	15h	21h	03h	09h	15h	21h	03h	09h	15h	21h	03h	09h	15h	21h
Météo																												
Vent (km/h)	90	100	95	105	95	95	85	70	60	70	85	105	115	110	95	85	80	80	95	100	95	85	95	95	90	85	90	95
à 3000m																												
Vent (km/h)	75	80	80	85	75	75	65	60	45	60	60	80	90	90	80	65	70	70	80	85	80	80	80	80	80	75	85	85
à 2000m																												

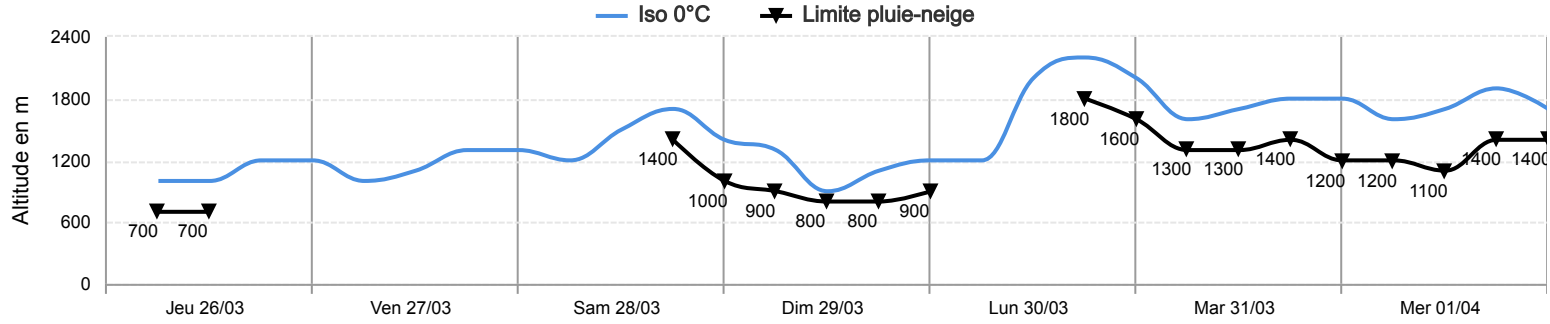

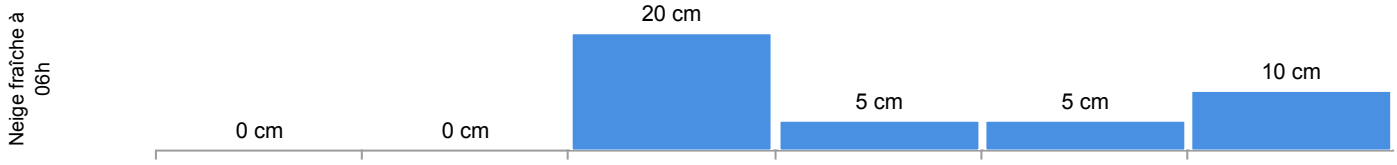

Risque d'avalanche	jeu. 26/03	ven. 27/03	sam. 28/03	dim. 29/03	lun. 30/03	mar. 31/03	mer. 01/04
	2	2	2	3	3	3	3

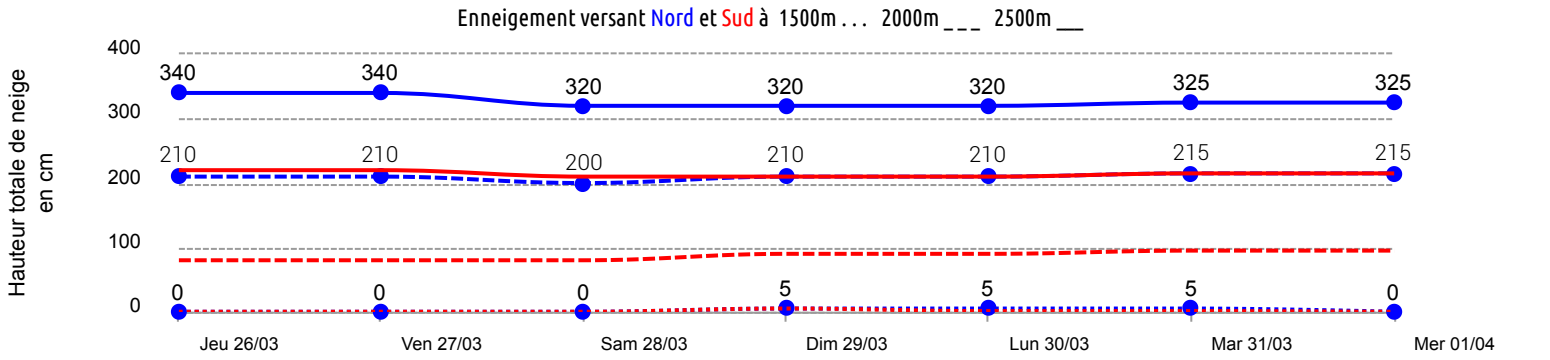

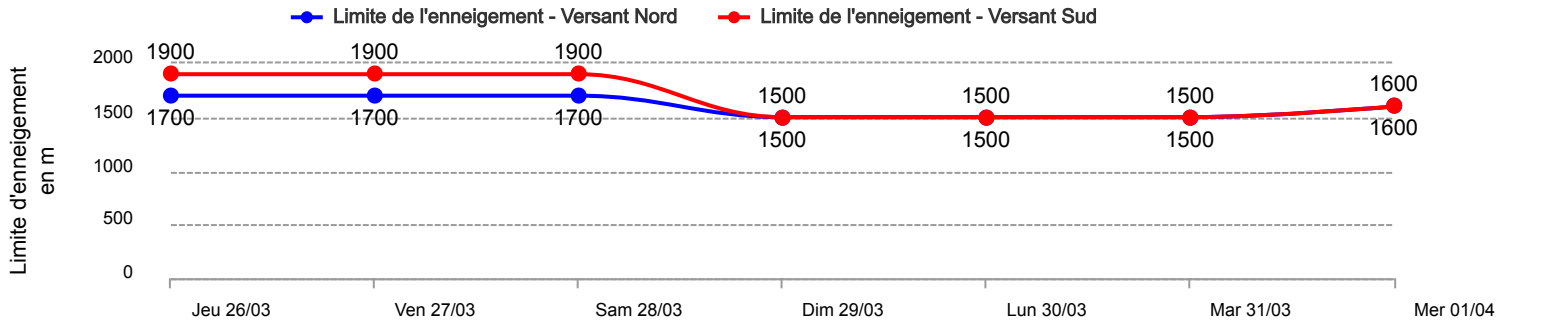

Pour consulter la vigilance en cours, veuillez vous rendre sur le site https://vigilance.meteofrance.fr/fr

Météo-France - 73 avenue de Paris, 94165 Saint-Mandé cedex - Contact : contact@meteo.fr

Rédigé par Météo-France avec la contribution des observateurs du réseau nivo-météorologiques. Partenariat : ANMSM (Maires de Stations de Montagne), DSF (Domaines Skiables de France), ADSP (Directeurs de Pistes et de la Sécurité des Stations de Sports d'Hiver) et autres acteurs de la montagne.

Bulletin neige & avalanches par téléphone au
0 892 68 10 20 Service 0,35 € / min + prix appel