Bulletin d'estimation du risque d'avalanche
(valable en dehors des pistes balisées et ouvertes)

MASSIF : Cerdagne Canigou

Rédigé le mercredi 1 avril 2026 à 16h

Estimation des risques pour le : JEUDI 02 AVRIL

STRUCTURES DE PLAQUES FORMÉES SUROUT PAR LE TRANSPORT DE NEIGE PAR LE VENT

2

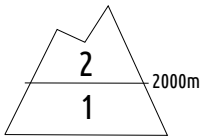

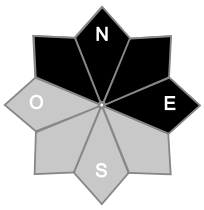

Au-dessus de 2000m indice de risque limité, plus bas indice faible.

Départs spontanés : Petits départs ponctuels en neige récente dans des couloirs raides

Déclenchements provoqués : Anciennes plaques en versants nord; nouvelles plaques à vent localisés avec les petites chutes de neige et le transport par le vent.

Indices de risque : 5 très fort - 4 fort - 3 marqué - 2 limité - 1 faible -- En noir : les pentes les plus dangereuses

Stabilité du manteau neigeux

Situation avalancheuse typique : neige ventée

(A partir d'informations réduites)

Déclenchements provoqués :

De structures de plaques, plutôt dures proches des crêtes, parfois encore d'aspect friable loin des crêtes et dans des combes plus abritées, sont en place ou encore en formation sous l'action du vent qui souffle depuis plusieurs jours. Leurs déclenchements devraient se limiter à des avalanches de petites tailles toutefois suffisantes pour déséquilibrer ou faire chuter un pratiquant. Elles pourront localement être de taille moyenne dans les accumulations les plus importantes situées préférentiellement dans un large secteur est au-dessus de 2000m.

Le danger sera majoré en cas de chutes de neige dépassant les 15/20 cm, avec davantage d'instabilité alors dans cette neige récente.

Observables : neige en surface travaillée par le vent, fissures devant les skis ou "woomfs" éventuels.

Départs spontanés :

Quelques départs en neige sèche dans les couloirs raides.

Qualité de la neige

Enneigement :

L'enneigement est excellent et compte parmi les meilleurs de ces 20 dernières années. En altitude, les cumuls sont encore conséquents, mais les crêtes et sommets exposés au vent d'ouest à nord-ouest sont souvent complètement déneigés. Avec les nouvelles chutes de neige datant samedi et dimanche matin, on retrouve un peu de neige au mieux vers 1500 m mais on peut seulement chausser vers 1600/1700 m en Nord pour trouver une réelle sous-couche permettant de progresser à ski.

Qualité de la neige :

On pourrait retrouver 15/20 cm de neige récente jeudi matin sur les secteurs du Cambre, 10/15 cm sur le Puigmal ou le Canigou.

Aperçu météo pour le jeudi 02 avril

	nuit	matin	après-midi	soir

Neigeux dans la nuit et en matinée, du mieux l'après-midi.

Pluie-Neige	1 500 m	1 300 m		
Iso 0 °C	1 800 m	2 100 m	2 300 m	2 100 m
Vent 2000 m	↓ 70 km/h	↘ 65 km/h	↘ 70 km/h	↘ 70 km/h
Vent 3000 m	↘ 100 km/h	↓ 95 km/h	↓ 95 km/h	↓ 105 km/h

Épaisseur de neige hors-piste

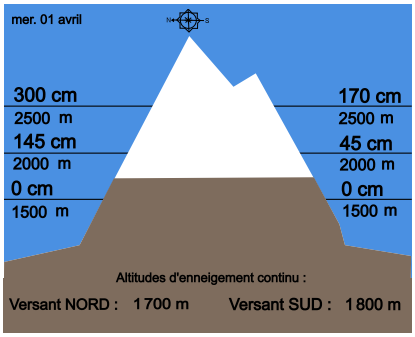

Précipitations à 1800 m

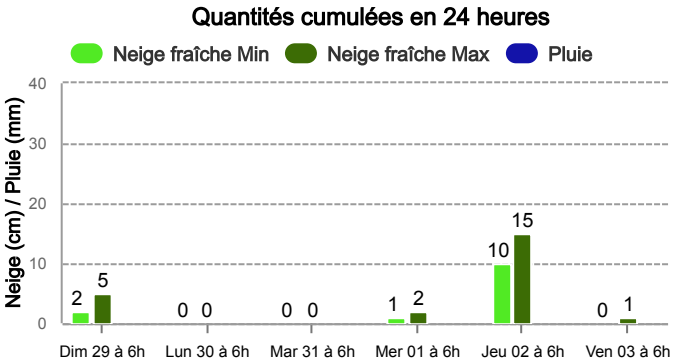

Tendance du vendredi 03 avril

2 **Indice de risque limité**

Stationnaire avec encore un peu de transport de neige sèche par le vent sur les crêtes.

Pour consulter la vigilance en cours, veuillez vous rendre sur le site https://vigilance.meteofrance.fr/fr

Météo-France - 73 avenue de Paris, 94165 Saint-Mandé cedex - Contact : contact@meteo.fr

Rédigé par Météo-France avec la contribution des observateurs du réseau nivo-météorologiques. Partenariat : ANMSM (Maires de Stations de Montagne), DSF (Domaines Skiables de France), ADSP (Directeurs de Pistes et de la Sécurité des Stations de Sports d'Hiver) et autres acteurs de la montagne.

Bulletin neige & avalanches par téléphone au **0 892 68 10 20** Service 0,35 € / min + prix appel

RÉPUBLIQUE FRANÇAISE
Liberté Égalité Fraternité

METEO FRANCE
À VOS CÔTÉS, DANS UN CLIMAT QUI CHANGE

Bulletin d'estimation du risque d'avalanche
(valable en dehors des pistes balisées et ouvertes)
MASSIF : Cerdagne Canigou

Rédigé le mercredi 1 avril 2026 à 16h

Conditions nivo-météo des 7 derniers jours

	jeu. 26/03				ven. 27/03				sam. 28/03				dim. 29/03				lun. 30/03				mar. 31/03				mer. 01/04			
	03h	09h	15h	21h	03h	09h	15h	21h	03h	09h	15h	21h	03h	09h	15h	21h	03h	09h	15h	21h	03h	09h	15h	21h	03h	09h	15h	21h
Météo																												
Vent (km/h)	90	100	95	105	95	95	85	70	75	70	80	105	120	110	90	90	90	85	90	100	105	90	100	105	100	90	95	100
à 3000m																												
Vent (km/h)	75	80	80	85	75	75	65	55	60	50	60	80	95	85	65	70	60	60	70	75	65	65	70	75	70	70	75	80
à 2000m																												

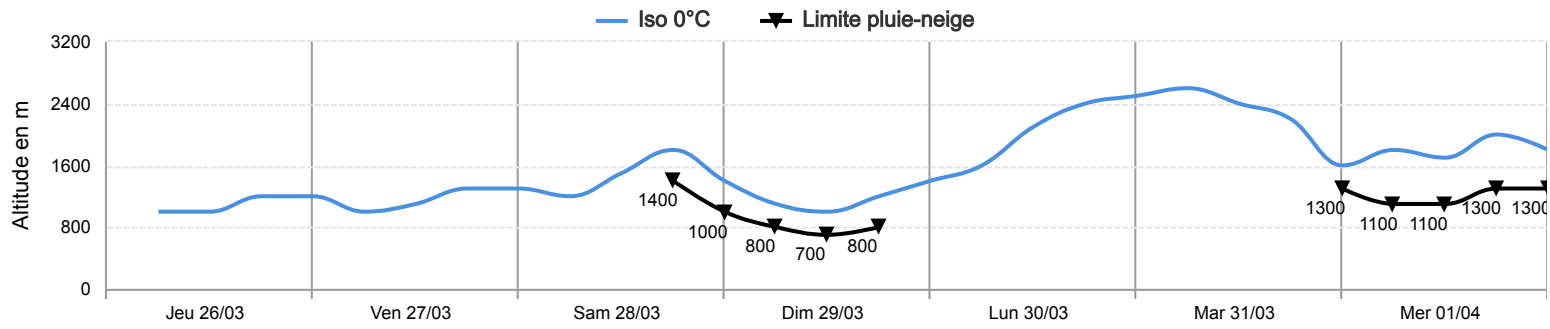

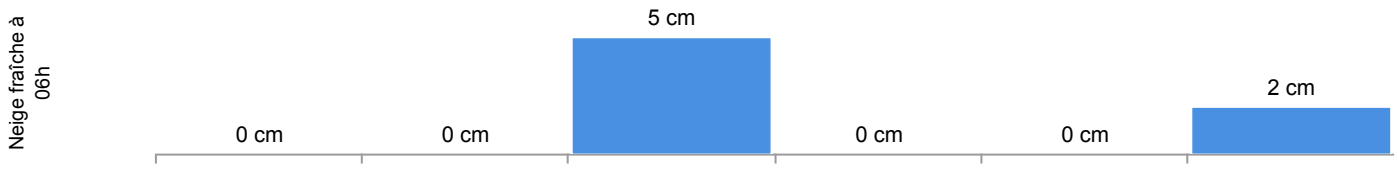

Risque d'avalanche	jeu. 26/03	ven. 27/03	sam. 28/03	dim. 29/03	lun. 30/03	mar. 31/03	mer. 01/04
	2	2	2	2	2	2	2

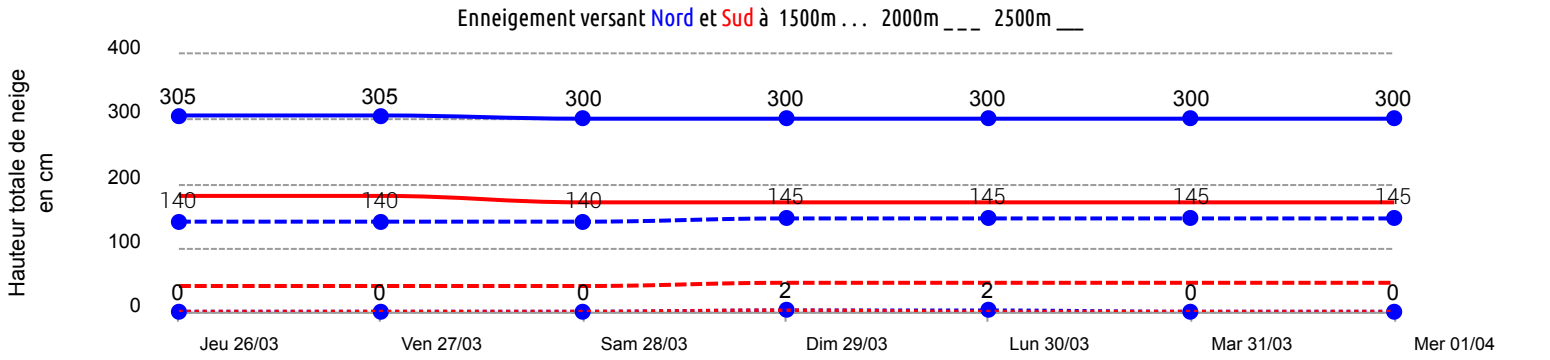

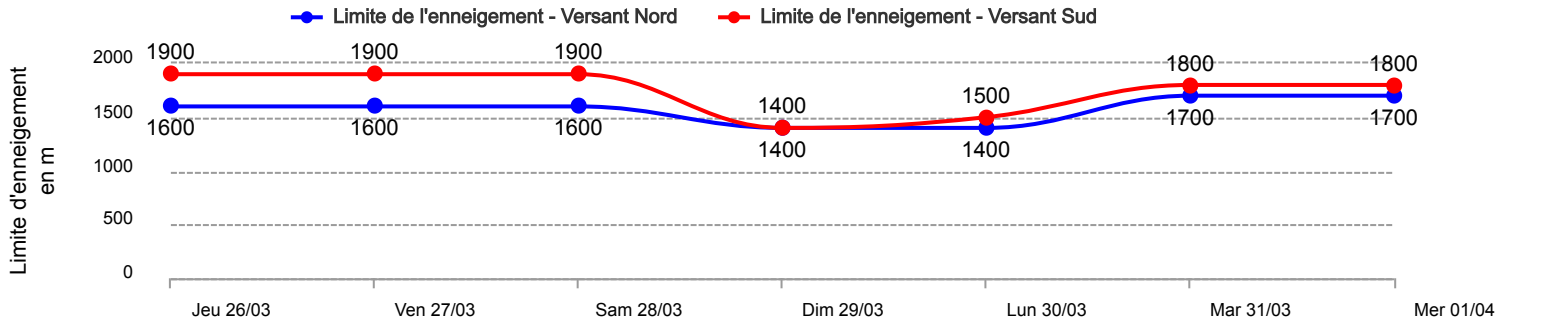

Pour consulter la vigilance en cours, veuillez vous rendre sur le site https://vigilance.meteofrance.fr/fr

Météo-France - 73 avenue de Paris, 94165 Saint-Mandé cedex - Contact : contact@meteo.fr

Bulletin neige & avalanches par téléphone au
0 892 68 10 20 Service 0,35 € / min + prix appel

Rédigé par Météo-France avec la contribution des observateurs du réseau nivo-météorologiques. Partenariat : ANMSM (Maires de Stations de Montagne), DSF (Domaines Skiables de France), ADSP (Directeurs de Pistes et de la Sécurité des Stations de Sports d'Hiver) et autres acteurs de la montagne.