Bulletin d'estimation du risque d'avalanche
(valable en dehors des pistes balisées et ouvertes)

MASSIF : Embrunais Parpaillon

Rédigé le mercredi 1 avril 2026 à 16h

Estimation des risques pour le : JEUDI 02 AVRIL

QUELQUES PLAQUES EN ALTITUDE DANS LA NEIGE VENTÉE

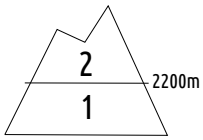

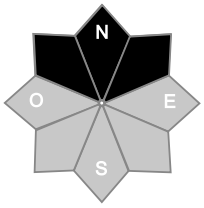

Au-dessus de 2200m indice de risque limité, plus bas indice faible.

Départs spontanés : peu probables.

Déclenchements provoqués : quelques instabilités dans la neige ventée.

Indices de risque : 5 très fort - 4 fort - 3 marqué - 2 limité - 1 faible -- En noir : les pentes les plus dangereuses

Stabilité du manteau neigeux

Situation avalancheuse typique : neige ventée

Déclenchements provoqués : des plaques sont encore présentes dans quelques pentes d'altitude, formées par transport de neige récente par le vent de nord de ces derniers jours. Elles se situent au dessus de 2200 m, possibles en tous versants mais plutôt en un large secteur nord, généralement loin des crêtes. Elles sont le plus souvent d'aspect durci par le vent, et bien identifiables. En cas de déclenchement par un skieur, elles provoquent des avalanches de taille petite à parfois moyenne.

Départs spontanés : peu probables. De rares départs superficiels de neige humide sont possibles l'après-midi, par départ ponctuel à proximité des rochers en pentes raides ensoleillées.

Qualité de la neige

L'enneigement est proche des normales pour un début avril.
Hauteurs de neige observées : 103 cm à la nivôse du Parpaillon à 2500 m.

Limite d'enneigement skiable : au plus bas à 1500 m en ubacs bien protégés ou sur pistes forestières, plutôt 2000/2100 m en adrets.

État de la neige de surface : neige souvent durcie et travaillée par le vent, encore localement légère dans les secteurs bien abrités en versants nord. En versants sud, manteau neigeux souvent regelé sous 2500 m, s'humidifiant superficiellement en journée. Sur les crêtes, d'épaisses corniches côtoient des zones pelées par le vent.

Aperçu météo pour le jeudi 02 avril

nuit	matin	après-midi	soir

Temps ensoleillé, sec, et un peu plus doux.

Pluie-Neige				
Iso 0 °C	1 700 m	1 800 m	2 000 m	2 200 m
Vent 2000 m	25 km/h	15 km/h	25 km/h	15 km/h
Vent 3000 m	50 km/h	30 km/h	25 km/h	15 km/h

Épaisseur de neige hors-piste

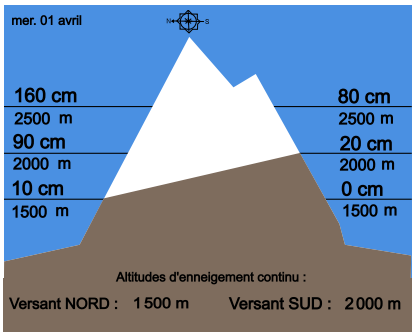

Précipitations à 1800 m

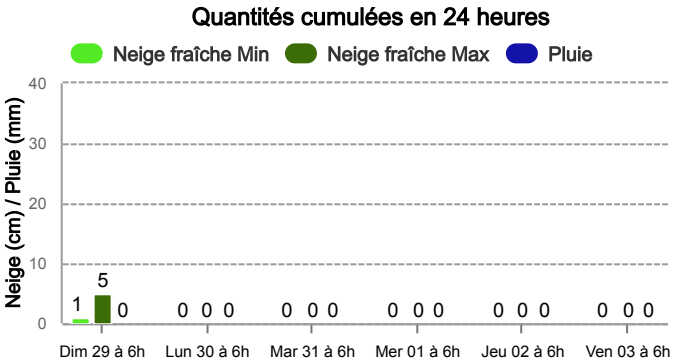

Tendance du vendredi 03 avril

Indice de risque limité

Maintient d'un risque limité, avec de possibles rares plaques encore présentes.

Pour consulter la vigilance en cours, veuillez vous rendre sur le site https://vigilance.meteofrance.fr/fr

Météo-France - 73 avenue de Paris, 94165 Saint-Mandé cedex - Contact : contact@meteo.fr

Rédigé par Météo-France avec la contribution des observateurs du réseau nivo-météorologiques. Partenariat : ANMSM (Maires de Stations de Montagne), DSF (Domaines Skiables de France), ADSP (Directeurs de Pistes et de la Sécurité des Stations de Sports d'Hiver) et autres acteurs de la montagne.

Bulletin neige & avalanches par téléphone au
0 892 68 10 20 Service 0,35 € / min + prix appel

RÉPUBLIQUE FRANÇAISE
Liberté Égalité Fraternité

METEO FRANCE
À VOS CÔTÉS, DANS UN CLIMAT QUI CHANGE

Bulletin d'estimation du risque d'avalanche

(valable en dehors des pistes balisées et ouvertes)

MASSIF : Embrunais Parpaillon

Rédigé le mercredi 1 avril 2026 à 16h

Conditions nivo-météo des 7 derniers jours

	jeu. 26/03				ven. 27/03				sam. 28/03				dim. 29/03				lun. 30/03				mar. 31/03				mer. 01/04			
	03h	09h	15h	21h	03h	09h	15h	21h	03h	09h	15h	21h	03h	09h	15h	21h	03h	09h	15h	21h	03h	09h	15h	21h	03h	09h	15h	21h
Météo																												
Vent (km/h)	30	60	70	70	50	40	30	10	30	25	30	25	25	40	25	20	30	50	80	90	80	70	60	45	40	40	50	50
à 3000m																												
Vent (km/h)	20	50	60	50	45	40	20	10	10	10	20	20	20	30	25	15	10	20	50	70	70	60	45	30	25	25	35	35
à 2000m																												

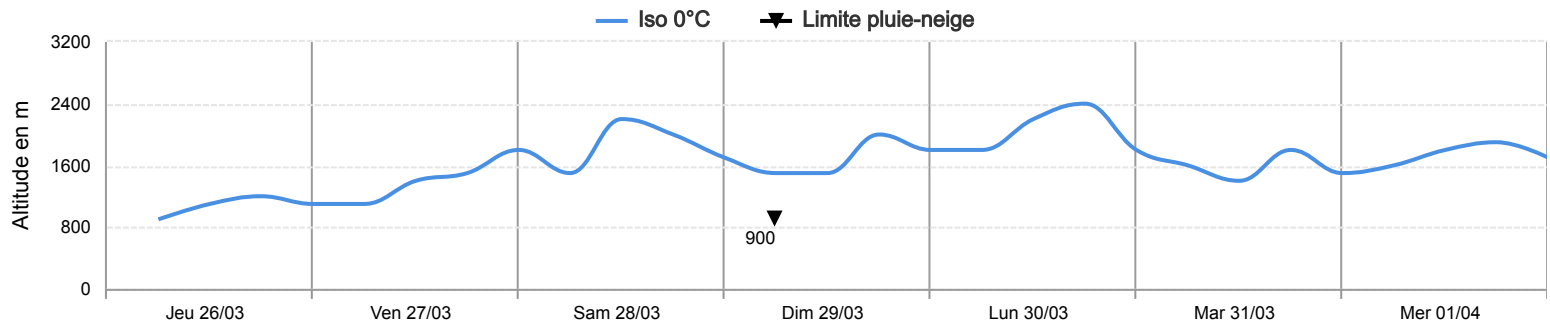

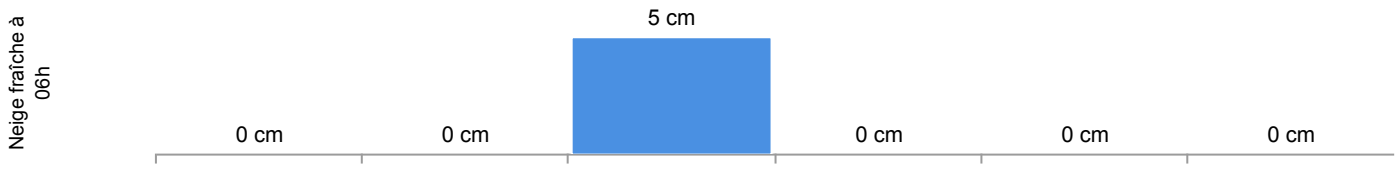

Risque d'avalanche	jeu. 26/03	ven. 27/03	sam. 28/03	dim. 29/03	lun. 30/03	mar. 31/03	mer. 01/04
	3	2	2	2	2	2	2

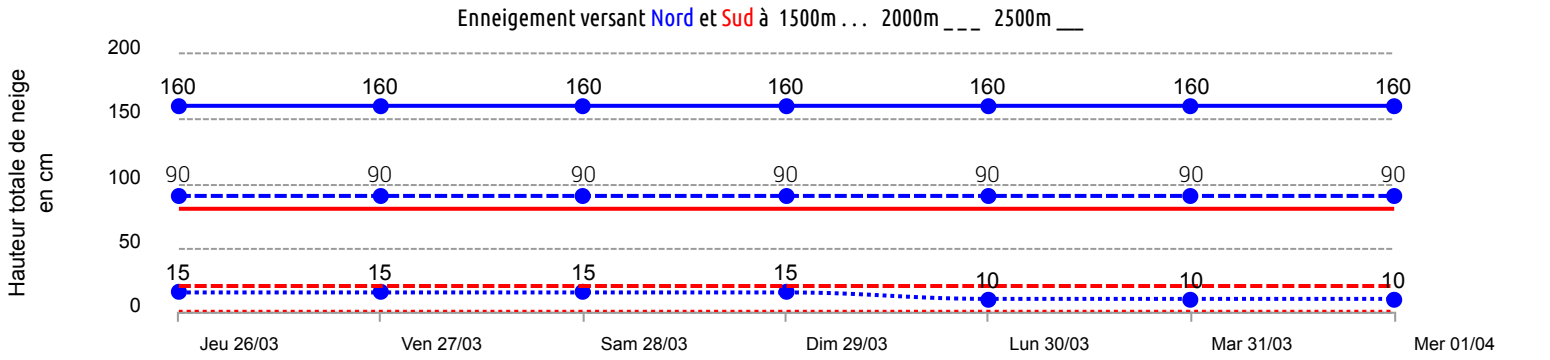

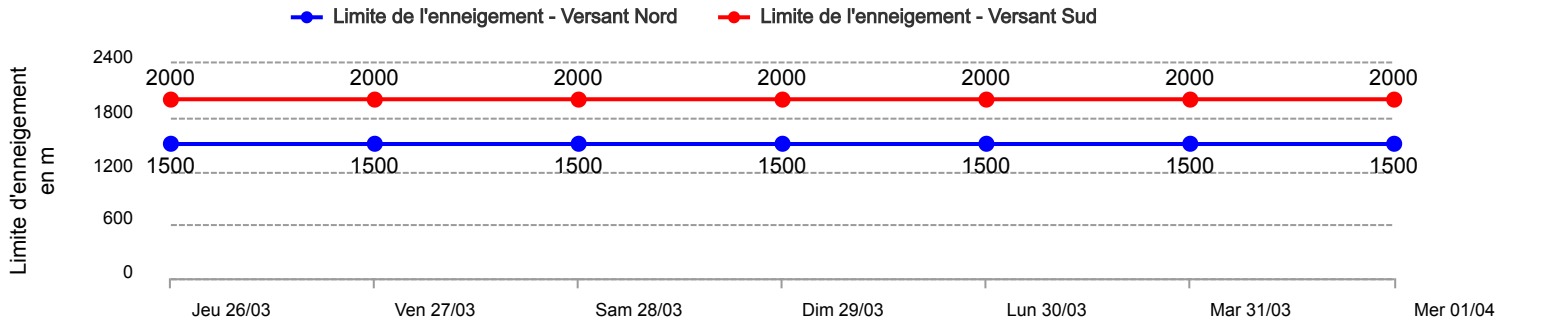

Pour consulter la vigilance en cours, veuillez vous rendre sur le site https://vigilance.meteofrance.fr/fr

Météo-France - 73 avenue de Paris, 94165 Saint-Mandé cedex - Contact : contact@meteo.fr

Bulletin neige & avalanches par téléphone au

0 892 68 10 20 Service 0,35 € / min + prix appel

Rédigé par Météo-France avec la contribution des observateurs du réseau nivo-météorologiques. Partenariat : ANMSM (Maires de Stations de Montagne), DSF (Domaines Skiables de France), ADSP (Directeurs de Pistes et de la Sécurité des Stations de Sports d'Hiver) et autres acteurs de la montagne.