Bulletin d'estimation du risque d'avalanche

(valable en dehors des pistes balisées et ouvertes)

MASSIF : Haute-Ariege

Rédigé le mercredi 1 avril 2026 à 16h

Estimation des risques pour le : JEUDI 02 AVRIL

ÉPISODE NEIGEUX CONSÉQUENT ET RISQUE DE DÉCLENCHEMENT SKIEUR EN NETTE HAUSSE.

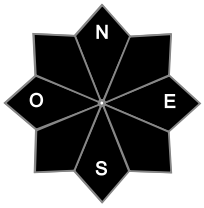

Indice de risque fort.

Départs spontanés : Avalanches de neige récente dans les couloirs chargés par le vent, dans la nuit et en matinée surtout, cumuls à surveiller.

Déclenchements provoqués : Dans toutes les pentes raides, plaques à vent avec neige roulée en sous couche fragile potentielle.

Indices de risque : 5 très fort - 4 fort - 3 marqué - 2 limité - 1 faible -- En noir : les pentes les plus dangereuses

Stabilité du manteau neigeux

Situation avalancheuse typique : neige fraîche couche fragile persistante

Départs spontanés :
Des départs ponctuels ou linéaires d'avalanches de neige fraiche sont attendus dans les pentes très raides en toutes orientations. Avalanches moyenne à grande, voire très grande en cas de cumuls dépassant les 60/70 cm, au cœur des massifs au-delà de 2000 m.
Justification : Le vent de nord/nord ouest soutenu continue de former de grosses accumulations parfois loin des crêtes, et les chutes de neige conséquentes perdurent tout au long de la journée. Le danger concerne tous les versants (pas de stabilisation) et en particulier les pentes Sud-Est.

Déclenchements provoqués :
De nombreuses structures de plaques facilement déclenchables sont présentes dans la neige récente et continuent de se former avec les nouvelles chutes et le vent turbulent.
Justification : manteau neigeux provisoirement très instable avec des sous-couches en neige roulée très répandues, notamment dans les versants froids.
Les accumulations les plus épaisses sont situées préférentiellement dans un large versant sud, mais pas uniquement. Elles sont difficilement détectables et en neige poudreuse tassée. Avalanches de taille moyenne ou grande en cas de déclenchements.
Observables : Quantité de neige fraiche, surface hétérogène travaillée par le vent, fissures devant les skis, "woomfs".

Autre :
Toujours une faible visibilité avec le mauvais temps qui perdure, froid sensible avec le vent, corniches volumineuses sous les crêtes.

Qualité de la neige

Enneigement :
L'enneigement est très bon pour la saison. En altitude, les cumuls sont conséquents, mais les crêtes et sommets exposés au vent d'ouest à nord-ouest sont un peu plus dégarnis.
Il est envisageable de chausser les skis vers 1200/1300 m, mais on retrouvera une sous-couche permettant de progresser plus sereinement plutôt à partir de 1500 m.

Qualité de la neige :
Jeudi matin, on devrait retrouver 20/30 cm de neige récente au-delà de 1500/1600 m, 30/50 cm au-delà de 2000 m, et parfois 50/70 cm dans les quelques vallons d'altitude les plus exposés de haute montagne. Apport de 10/15 cm en journée jeudi.
En altitude, l'enneigement et la qualité de la neige seront hétérogènes sous l'action du vent soufflant depuis samedi, avec des zones d'accumulations où la neige fraîche et/ou récente reste localement légère et des zones proches des crêtes Ouest à Nord-Ouest pelées ou en neige dure, voire glacée.

Aperçu météo pour le jeudi 02 avril

Neige significative dans la nuit et en matinée, perdurant dans l'après-midi et au cours de la nuit suivante en faiblissant nettement.

	nuit	matin	après-midi	soir
Pluie-Neige	1 500 m	1 200 m	1 400 m	1 400 m
Iso 0 °C	1 700 m	1 600 m	1 800 m	1 700 m
Vent 2000 m	↓ 65 km/h	↓ 50 km/h	↓ 55 km/h	↓ 55 km/h
Vent 3000 m	↓ 90 km/h	↻ 75 km/h	↻ 80 km/h	↓ 80 km/h

Épaisseur de neige hors-piste

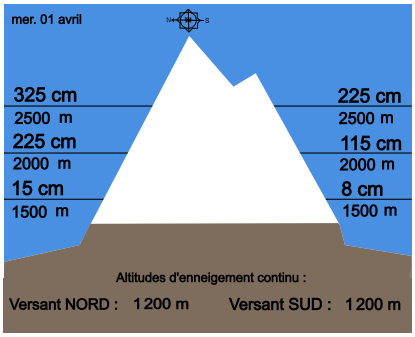

Précipitations à 1800 m

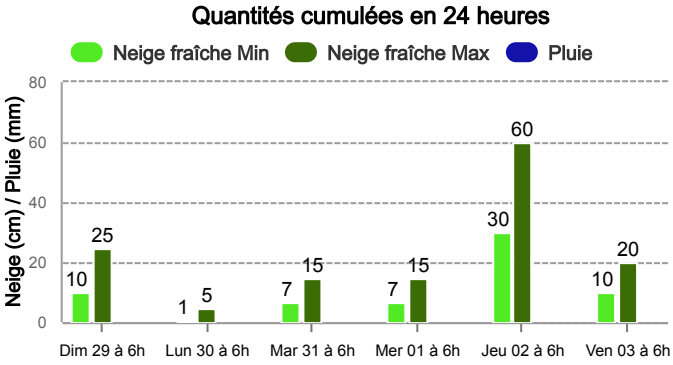

Tendance du vendredi 03 avril

Indice de risque fort

Maintien probable d'un risque fort (accident en matinée) avec éventuellement des départs en neige humide en fin de période.

Pour consulter la vigilance en cours, veuillez vous rendre sur le site https://vigilance.meteofrance.fr/fr

Météo-France - 73 avenue de Paris, 94165 Saint-Mandé cedex - Contact : contact@meteo.fr

Rédigé par Météo-France avec la contribution des observateurs du réseau nivo-météorologiques. Partenariat : ANMSM (Maires de Stations de Montagne), DSF (Domaines Skiables de France), ADSP (Directeurs de Pistes et de la Sécurité des Stations de Sports d'Hiver) et autres acteurs de la montagne.

Bulletin neige & avalanches par téléphone au
0 892 68 10 20 Service 0,35 € / min + prix appel

RÉPUBLIQUE FRANÇAISE
Liberté Égalité Fraternité

METEO FRANCE
À VOS CÔTÉS, DANS UN CLIMAT QUI CHANGE

Bulletin d'estimation du risque d'avalanche

(valable en dehors des pistes balisées et ouvertes)

MASSIF : Haute-Ariege

Rédigé le mercredi 1 avril 2026 à 16h

Conditions nivo-météo des 7 derniers jours

	jeu. 26/03				ven. 27/03				sam. 28/03				dim. 29/03				lun. 30/03				mar. 31/03				mer. 01/04			
	03h	09h	15h	21h	03h	09h	15h	21h	03h	09h	15h	21h	03h	09h	15h	21h	03h	09h	15h	21h	03h	09h	15h	21h	03h	09h	15h	21h
Météo																												
Vent (km/h)	85	85	80	75	80	80	65	45	40	45	70	90	100	100	85	65	60	60	65	70	70	65	70	75	75	75	85	85
à 3000m																												
Vent (km/h)	55	50	50	45	50	50	40	20	20	20	30	60	80	80	50	45	35	30	45	50	45	40	50	55	50	50	60	70
à 2000m																												

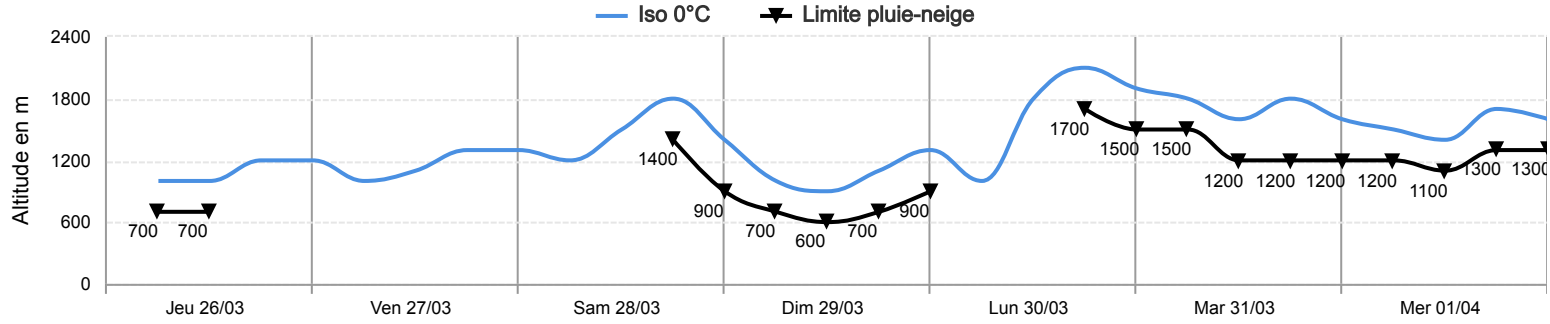

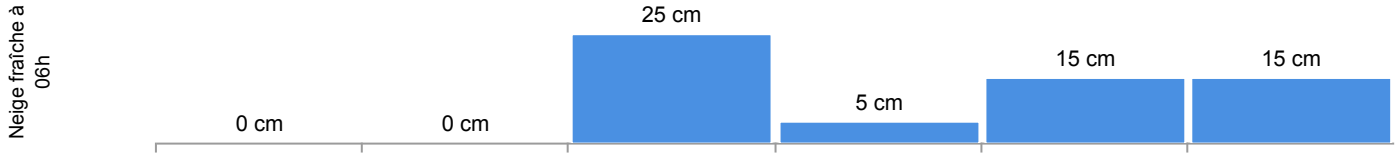

Risque d'avalanche	jeu. 26/03	ven. 27/03	sam. 28/03	dim. 29/03	lun. 30/03	mar. 31/03	mer. 01/04
	2	2	2	3	3	3	4

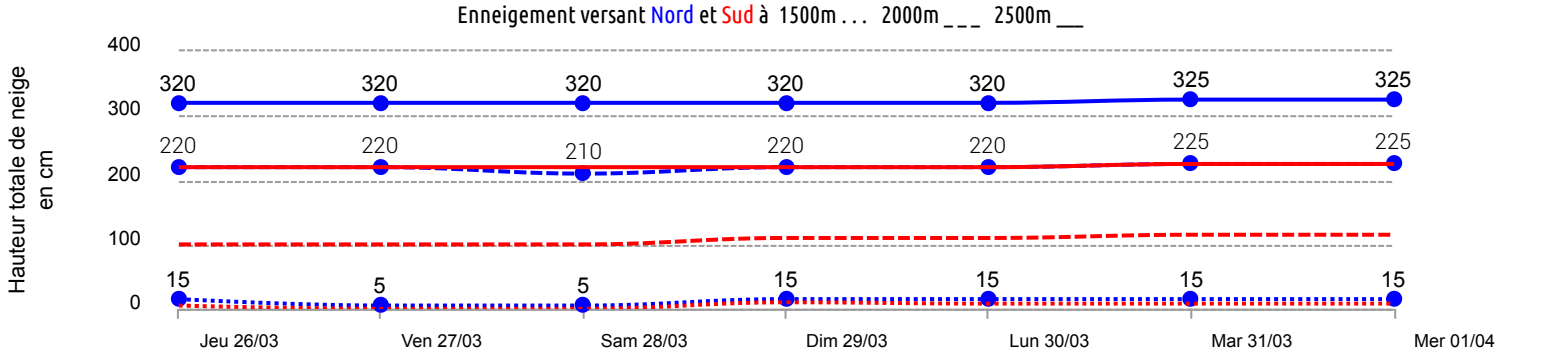

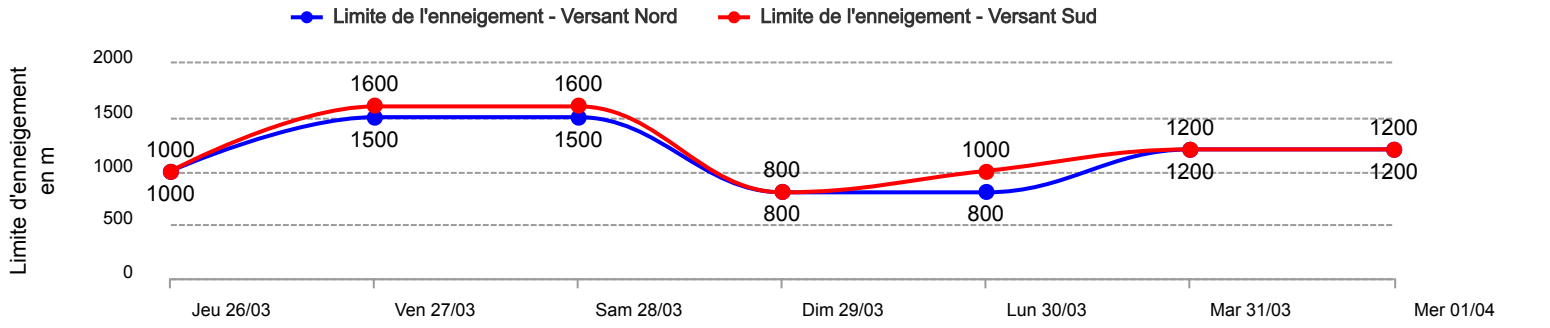

Pour consulter la vigilance en cours, veuillez vous rendre sur le site https://vigilance.meteofrance.fr/fr

Météo-France - 73 avenue de Paris, 94165 Saint-Mandé cedex - Contact : contact@meteo.fr

Rédigé par Météo-France avec la contribution des observateurs du réseau nivo-météorologiques. Partenariat : ANMSM (Maires de Stations de Montagne), DSF (Domaines Skiables de France), ADSP (Directeurs de Pistes et de la Sécurité des Stations de Sports d'Hiver) et autres acteurs de la montagne.

Bulletin neige & avalanches par téléphone au

0 892 68 10 20 Service 0,35 € / min + prix appel