Bulletin d'estimation du risque d'avalanche

(valable en dehors des pistes balisées et ouvertes)

MASSIF : Luchonnais

Rédigé le mercredi 1 avril 2026 à 16h

Estimation des risques pour le : JEUDI 02 AVRIL

NOUVELLES CHUTES DE NEIGE, FORMATION DE PLAQUES ÉPAISSES SUPPLÉMENTAIRES EN ALTITUDE, MANTEAU NEIGEUX INSTABLE.

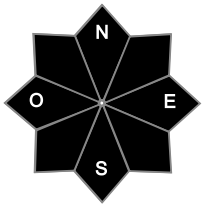

Indice de risque fort.

Départs spontanés : Nombreux départs ponctuels en pentes raides et en tous versants.

Déclenchements provoqués : Formations de plaques épaisses supplémentaires, reposant sur un manteau neigeux instable au-dessus de 2100 à 2200m.

Indices de risque : 5 très fort - 4 fort - 3 marqué - 2 limité - 1 faible -- En noir : les pentes les plus dangereuses

Stabilité du manteau neigeux

Situation avalancheuse typique : neige fraîche

Déclenchements provoqués :
Au-dessus de 2100 à 2200m, des plaques à vent continuent de se former dès la matinée au fil des chutes de neige de ce jeudi, dans les pentes raides, préférentiellement dans les versants à l'abri du vent de Nord à Nord-Ouest (large secteur Sud, en y ajoutant l'Ouest, l'Est ainsi que le Nord-Est). On peut aussi les trouver dans les autres versants sous l'effet du vent fort de Nord à Nord-Ouest. Elles viennent se former sur des plaques épaisses et en place, issues des chutes de neige de la veille et de la nuit, venant elles-mêmes reposer sur des plaques plus fines datant des chutes de neige de mardi et sur un manteau instable. Un simple skieur peut ainsi facilement solliciter ces plaques, et engendrer des avalanches moyennes à grandes (taille 2 à 3) dès la matinée, parfois même de très grandes avalanches (taille 4), même si cela reste moins récurrent, ce qui est rendu possible dans les zones d'accumulation les plus importantes.
Sous 2100 à 2200m, les plaques en formation viennent aussi reposer sur des plaques épaisses de la veille déjà en place le matin, elles-mêmes reposant sur de fines plaques datant de mardi. Le manteau est ensuite dur à regelé plus en profondeur. Le déclenchement de ces plaques reste aisé , des avalanches moyennes à grandes (taille 2 à 3) sont possibles dès la matinée et en tous versants.

Départs spontanés :
Avec les chutes de neige de la veille ainsi que celles en cours et celles à venir sur la journée, de nombreuses avalanches sont attendues en tous versants dès la matinée, moyennes à grandes (taille 2 à 3). De très grandes avalanches (taille 4) sont plus rares mais restent tout de même possibles, en partant notamment de couloirs très chargés ou de zones d'accumulation raides à l'abri du vent de Nord à Nord-Ouest. Il n'est cependant pas exclu de trouver ces avalanches dans les autres versants.
Il est aussi possible d'avoir des départs ponctuels de plaques décrites ci-dessus, **au-dessus de 2100 à 2200m**, par surcharge par le vent, engendrant ainsi des avalanches moyennes à grandes (taille 2 à 3) dès la matinée, et moins souvent des très grandes avalanches (taille 4) dans les zones d'accumulation les plus importantes.

Qualité de la neige

Enneigement : Correct pour la saison au-dessus de 1800m, mais restant assez maigre en versants exposés aux vents de nord à ouest. Poursuite des chutes de neige ce jeudi. Quelques centimètres de neige possibles et supplémentaires dès 1300m. Il est plutôt possible de chausser les skis vers 1500m, où une sous-couche est présente afin de progresser plus rapidement.
État de la neige : Jeudi matin, plusieurs centimètres de neige fraîche dès 1500m environ, la couche s'est considérablement épaissie avec les chutes de neige de la veille. Nouvelles chutes de neige en cours et à venir sur la journée, Les chutes de neige en cours et précédentes recouvrent en profondeur un manteau neigeux printanier à bien regelé sous 2100m environ. Plus haut, la neige est fraîche, et de plus en plus travaillée par le vent de Nord.

Aperçu météo pour le jeudi 02 avril

	nuit	matin	après-midi	soir
	Poursuite des averses de neige en journée, chutes régulières, toujours du vent fort de Nord en altitude, neige dès 1400m environ.			
Pluie-Neige	1 300 m	1 400 m	1 400 m	1 400 m
Iso 0 °C	1 600 m	1 600 m	1 600 m	1 600 m
Vent 2000 m	↓ 50 km/h	↓ 45 km/h	↓ 50 km/h	↓ 40 km/h
Vent 3000 m	↓ 85 km/h	↓ 80 km/h	↓ 70 km/h	↓ 70 km/h

Épaisseur de neige hors-piste

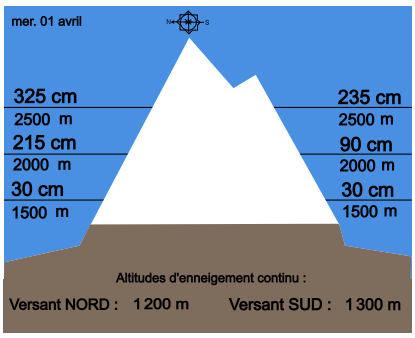

Précipitations à 1800 m

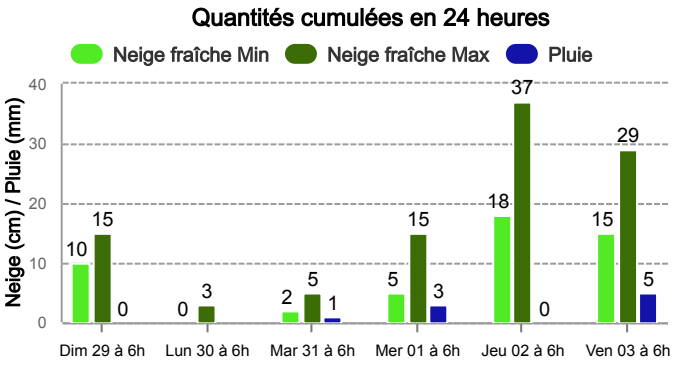

Tendance du vendredi 03 avril

Indice de risque fort

Baisse progressive du risque. Le risque avalancheux devrait rester important en altitude avec les chutes de neige passées et celles de jeudi. Humidification progressive du manteau neigeux sous 2200m vendredi.

Pour consulter la vigilance en cours, veuillez vous rendre sur le site https://vigilance.meteofrance.fr/fr

Météo-France - 73 avenue de Paris, 94165 Saint-Mandé cedex - Contact : contact@meteo.fr

Rédigé par Météo-France avec la contribution des observateurs du réseau nivo-météorologiques. Partenariat : ANMSM (Maires de Stations de Montagne), DSF (Domaines Skiables de France), ADSP (Directeurs de Pistes et de la Sécurité des Stations de Sports d'Hiver) et autres acteurs de la montagne.

Bulletin neige & avalanches par téléphone au **0 892 68 10 20** Service 0,35 € / min + prix appel

RÉPUBLIQUE FRANÇAISE
Liberté Égalité Fraternité

METEO FRANCE
À VOS CÔTÉS, DANS UN CLIMAT QUI CHANGE

Bulletin d'estimation du risque d'avalanche

(valable en dehors des pistes balisées et ouvertes)

MASSIF : Luchonnais

Rédigé le mercredi 1 avril 2026 à 16h

Conditions nivo-météo des 7 derniers jours

	jeu. 26/03				ven. 27/03				sam. 28/03				dim. 29/03				lun. 30/03				mar. 31/03				mer. 01/04			
	03h	09h	15h	21h	03h	09h	15h	21h	03h	09h	15h	21h	03h	09h	15h	21h	03h	09h	15h	21h	03h	09h	15h	21h	03h	09h	15h	21h
Météo																												
Vent (km/h)	90	80	75	80	85	80	70	60	55	35	45	65	95	100	80	80	80	60	65	60	90	90	85	80	85	85	80	80
à 3000m																												
Vent (km/h)	35	30	20	30	20	15	25	10	10	15	30	50	60	70	55	35	20	15	30	35	30	30	30	40	35	40	45	55
à 2000m																												

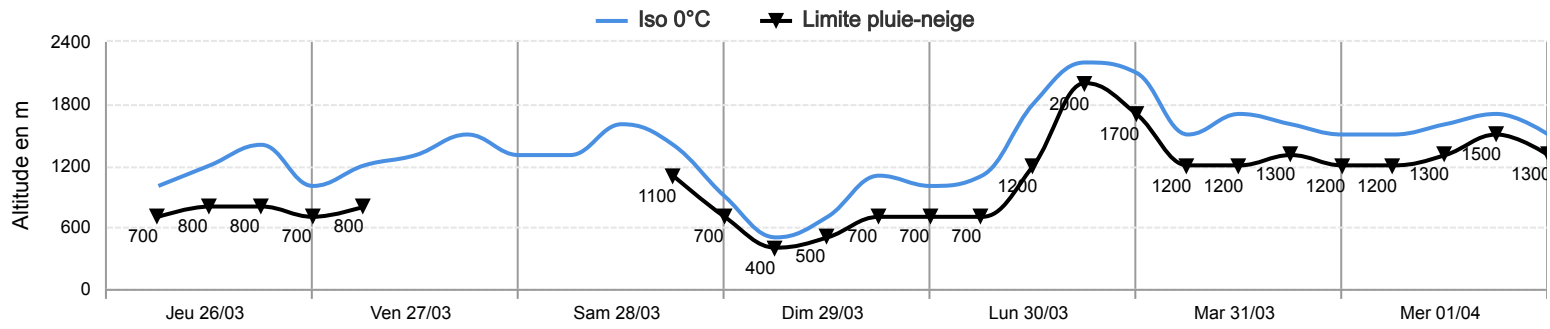

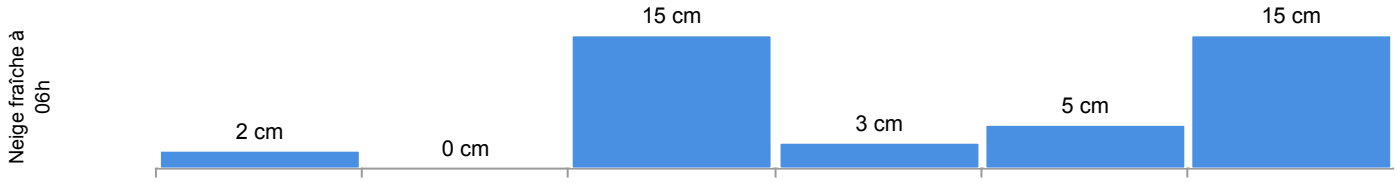

Risque d'avalanche	jeu. 26/03	ven. 27/03	sam. 28/03	dim. 29/03	lun. 30/03	mar. 31/03	mer. 01/04
	2	2	2	3	3	3	4

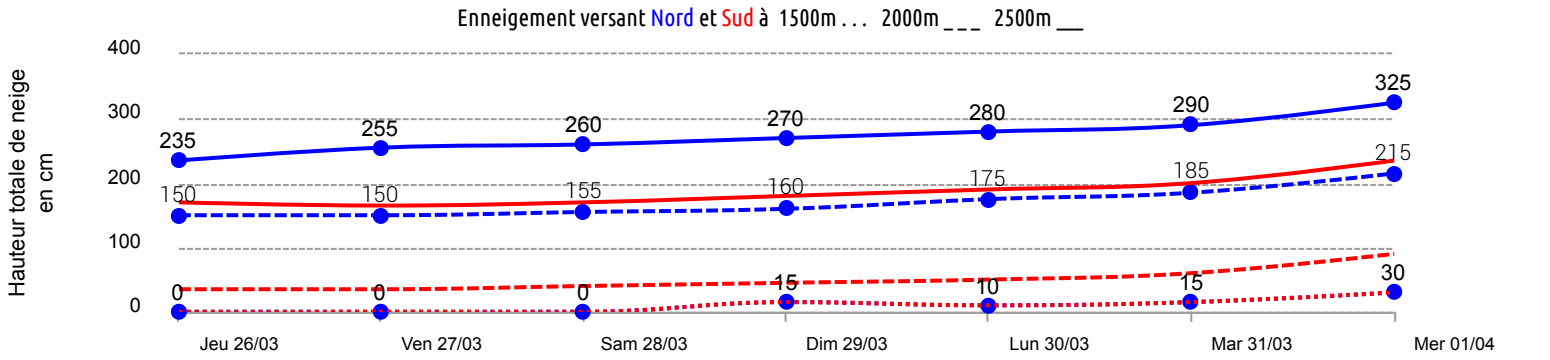

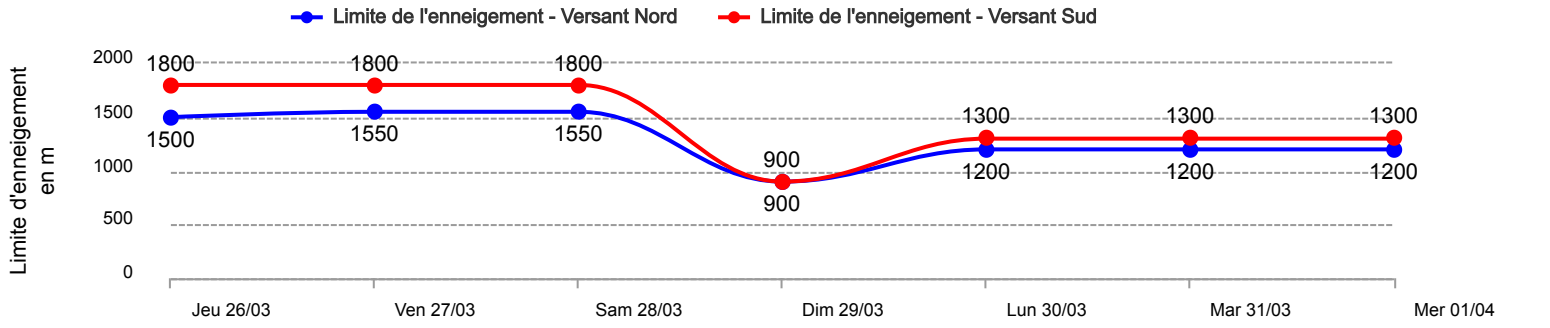

Pour consulter la vigilance en cours, veuillez vous rendre sur le site https://vigilance.meteofrance.fr/fr

Météo-France - 73 avenue de Paris, 94165 Saint-Mandé cedex - Contact : contact@meteo.fr

Rédigé par Météo-France avec la contribution des observateurs du réseau nivo-météorologiques. Partenariat : ANMSM (Maires de Stations de Montagne), DSF (Domaines Skiables de France), ADSP (Directeurs de Pistes et de la Sécurité des Stations de Sports d'Hiver) et autres acteurs de la montagne.

Bulletin neige & avalanches par téléphone au
0 892 68 10 20 Service 0,35 € / min + prix appel