Bulletin d'estimation du risque d'avalanche

(valable en dehors des pistes balisées et ouvertes)

MASSIF : Pays-Basque

Rédigé le mercredi 1 avril 2026 à 16h

Estimation des risques pour le : JEUDI 02 AVRIL

NOUVELLES CHUTES DE NEIGE, FORMATION DE PLAQUES ÉPAISSES SUPPLÉMENTAIRES EN ALTITUDE.

3

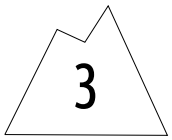

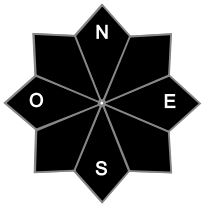

Indice de risque marqué.

Départs spontanés : Départs ponctuels en pentes raides au fil des chutes de neige et dans la neige en place.

Déclenchements provoqués : Formation de plaques épaisses supplémentaires.

Indices de risque : 5 très fort - 4 fort - 3 marqué - 2 limité - 1 faible -- En noir : les pentes les plus dangereuses

Stabilité du manteau neigeux

Situation avalancheuse typique : neige fraîche

Déclenchements provoqués :
Des plaques à vent continuent de se former dès la matinée au fil des chutes de neige de ce jeudi, dans les pentes raides, préférentiellement dans les versants à l'abri du vent de Nord à Nord-Ouest (large secteur Sud, en y ajoutant l'Ouest, l'Est ainsi que le Nord-Est). On peut tout de même les trouver dans les autres versants sous l'effet du vent fort de Nord à Nord-Ouest. Elles viennent se former sur des plaques épaisses et en place, issues des chutes de neige de la veille et de la nuit, venant elles-mêmes reposer sur des plaques plus fines datant des chutes de neige de mardi. Le manteau est ensuite dur à regelé plus en profondeur. Un simple skieur peut ainsi facilement solliciter ces plaques, et engendrer des avalanches moyennes à grandes (taille 2 à 3) dès la matinée.

Départs spontanés :
Avec les chutes de neige de la veille ainsi que celles en cours et celles à venir sur la journée, de nombreuses avalanches sont attendues en tous versants dès la matinée, moyennes à grandes (taille 2 à 3). Les grandes avalanches se trouvent notamment en partant de couloirs très chargés ou de zones d'accumulation raides à l'abri du vent de Nord à Nord-Ouest, donc plutôt des secteurs Nord-Est à Ouest, en passant par le Sud. Il n'est cependant pas exclu de trouver ces avalanches dans les autres versants.
Il est aussi possible d'avoir des départs ponctuels de plaques décrites ci-dessus, par surcharge par le vent, engendrant ainsi des avalanches moyennes à grandes (taille 2 à 3), dès la matinée.

Qualité de la neige

Enneigement : Correct pour la saison au-dessus de 1800m, mais restant assez maigre en versants exposés au vent d'ouest. Poursuite des chutes de neige ce jeudi, après les cumuls conséquents de la veille. Quelques centimètres de neige possibles et supplémentaires dès 1300m. Il est plutôt possible de chausser les skis vers 1500m, où une sous-couche est présente afin de progresser plus rapidement.
État de la neige : Jeudi matin, plusieurs centimètres de neige fraîche dès 1500m environ, la couche s'est considérablement épaissie avec les chutes de neige de la veille. Nouvelles chutes de neige en cours et à venir sur la journée, recouvrant la neige de la veille, elle-même recouvrant celle de mardi moins conséquente. Le manteau neigeux est printanier à bien regelé sous cette fine couche datant de mardi. La neige est fraîche, et de plus en plus travaillée par le vent de Nord. L'enneigement et la qualité de la neige seront hétérogènes sous l'action du vent, alternant surface dures pelées par le vent et accumulations plus meubles.

Aperçu météo pour le jeudi 02 avril

	nuit	matin	après-midi	soir
	Poursuite des averses de neige en journée, chutes régulières, toujours du vent fort de Nord en altitude, neige dès 1400m environ.			
Pluie-Neige	1 400 m	1 400 m	1 400 m	1 400 m
Iso 0 °C	1 600 m	1 600 m	1 600 m	1 600 m
Vent 1000 m	↓ 45 km/h	↓ 40 km/h	↓ 45 km/h	↓ 35 km/h
Vent 2000 m	↘ 70 km/h	↓ 65 km/h	↓ 65 km/h	↘ 55 km/h

Épaisseur de neige hors-piste

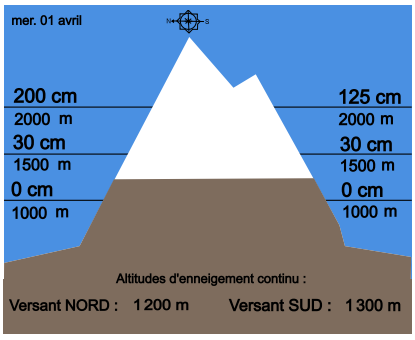

Précipitations à 1800 m

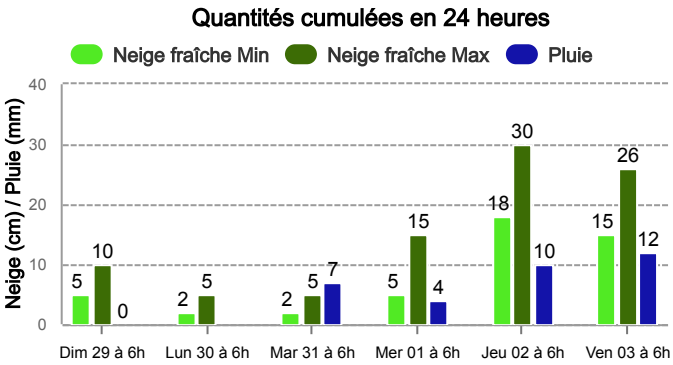

Tendance du vendredi 03 avril

3 **Indice de risque marqué**

Maintien d'un risque marqué mais en baisse progressive. Le risque avalancheux devrait rester important en altitude avec les chutes de neige passées et celles de jeudi. Humidification progressive du manteau neigeux vendredi.

Pour consulter la vigilance en cours, veuillez vous rendre sur le site https://vigilance.meteofrance.fr/fr

Météo-France - 73 avenue de Paris, 94165 Saint-Mandé cedex - Contact : contact@meteo.fr

Bulletin neige & avalanches par téléphone au 0 892 68 10 20 Service 0,35 € / min + prix appel

Rédigé par Météo-France avec la contribution des observateurs du réseau nivo-météorologiques. Partenariat : ANMSM (Maires de Stations de Montagne), DSF (Domaines Skiables de France), ADSP (Directeurs de Pistes et de la Sécurité des Stations de Sports d'Hiver) et autres acteurs de la montagne.

RÉPUBLIQUE FRANÇAISE
Liberté Égalité Fraternité

METEO FRANCE
À VOS CÔTÉS, DANS UN CLIMAT QUI CHANGE

Bulletin d'estimation du risque d'avalanche
(valable en dehors des pistes balisées et ouvertes)
MASSIF : Pays-Basque

Rédigé le mercredi 1 avril 2026 à 16h

Conditions nivo-météo des 7 derniers jours

	jeu. 26/03				ven. 27/03				sam. 28/03				dim. 29/03				lun. 30/03				mar. 31/03				mer. 01/04			
	03h	09h	15h	21h	03h	09h	15h	21h	03h	09h	15h	21h	03h	09h	15h	21h	03h	09h	15h	21h	03h	09h	15h	21h	03h	09h	15h	21h
Météo																												
Vent (km/h)	75	80	85	85	75	65	55	55	55	55	65	75	80	85	75	75	60	45	50	50	55	50	50	55	60	65	80	65
à 2000m																												
Vent (km/h)	35	40	50	50	35	35	35	25	20	25	40	45	45	40	50	40	35	25	35	40	40	30	35	40	35	35	45	45
à 1000m																												

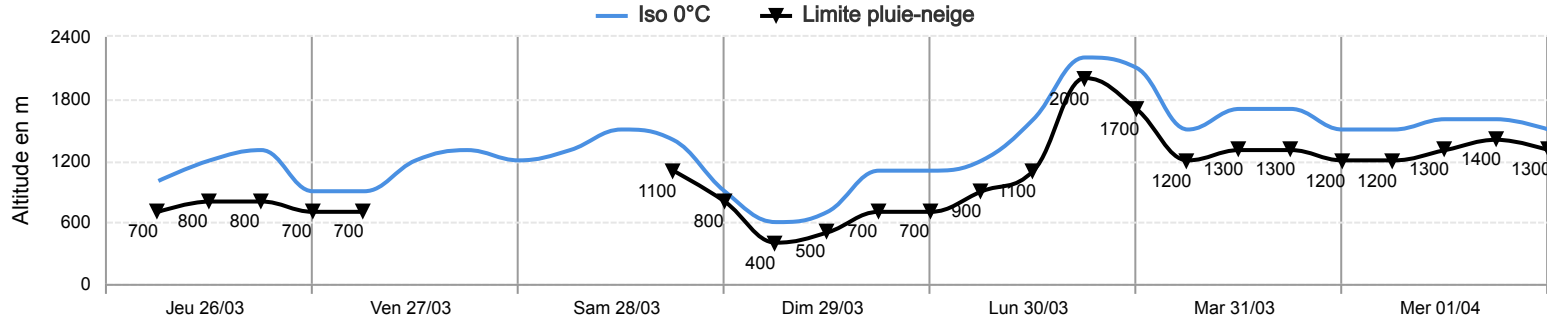

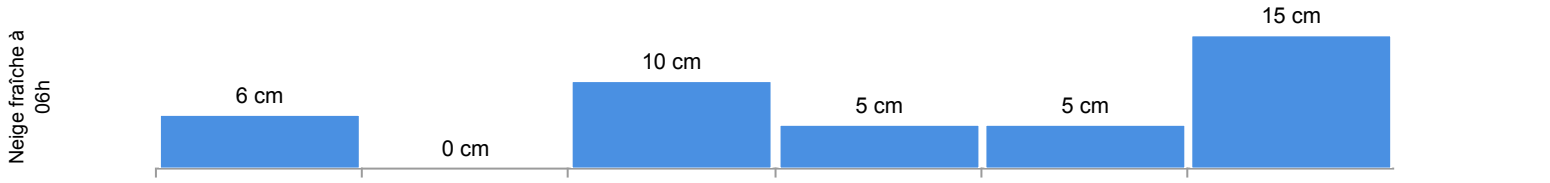

Risque d'avalanche	jeu. 26/03	ven. 27/03	sam. 28/03	dim. 29/03	lun. 30/03	mar. 31/03	mer. 01/04
	2	2	2	3	3	2	3

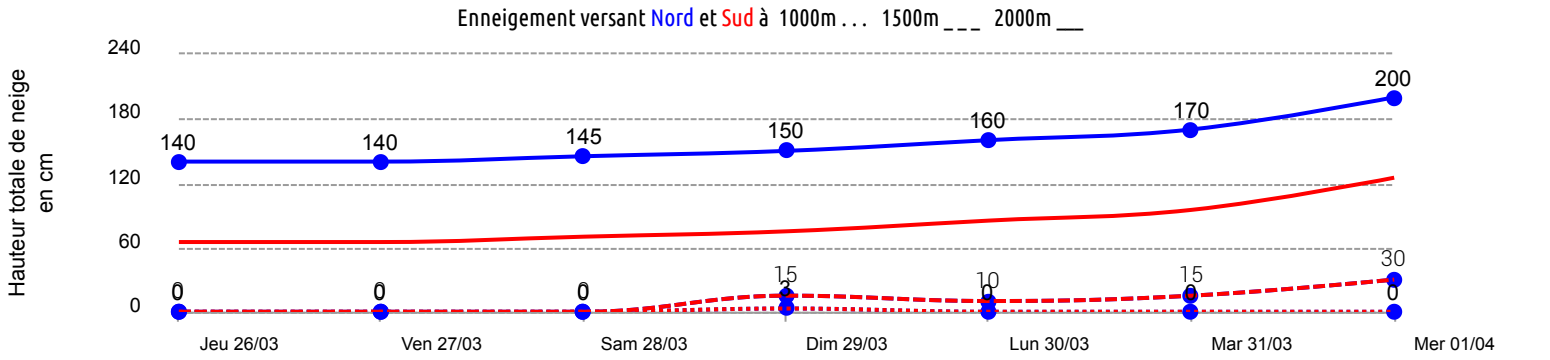

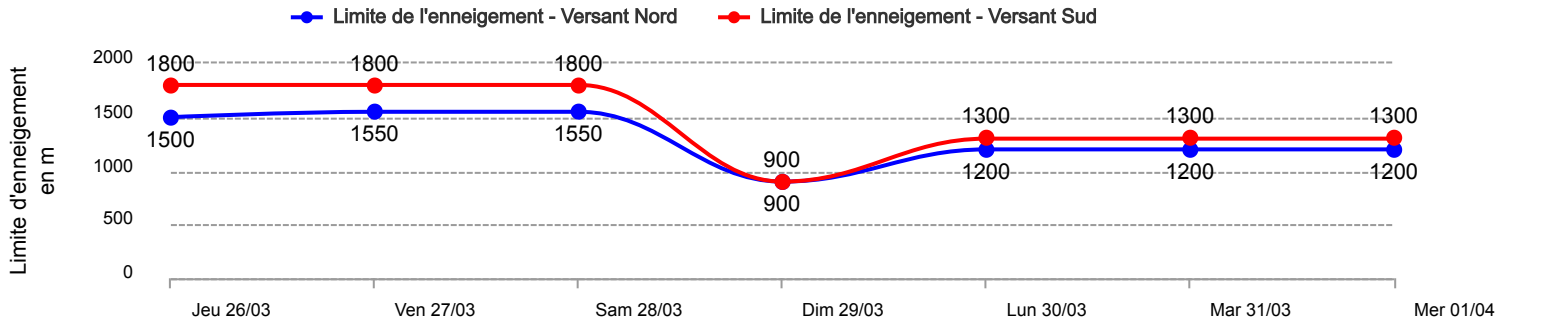

Pour consulter la vigilance en cours, veuillez vous rendre sur le site https://vigilance.meteofrance.fr/fr

Météo-France - 73 avenue de Paris, 94165 Saint-Mandé cedex - Contact : contact@meteo.fr

Rédigé par Météo-France avec la contribution des observateurs du réseau nivo-météorologiques. Partenariat : ANMSM (Maires de Stations de Montagne), DSF (Domaines Skiables de France), ADSP (Directeurs de Pistes et de la Sécurité des Stations de Sports d'Hiver) et autres acteurs de la montagne.

Bulletin neige & avalanches par téléphone au
0 892 68 10 20 Service 0,35 € / min + prix appel