Bulletin d'estimation du risque d'avalanche

(valable en dehors des pistes balisées et ouvertes)

MASSIF : Vercors

Rédigé le mercredi 1 avril 2026 à 17h

Estimation des risques pour le : JEUDI 02 AVRIL

QUELQUES INSTABILITES DUES AU VENT

2

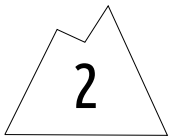

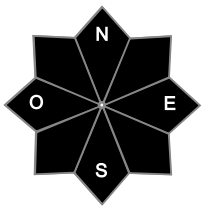

neige ventée

Indice de risque limité.

Départs spontanés : Possibles petites plaques dans les pentes chargées par le vent.

Déclenchements provoqués : Quelques plaques à vent dans les secteurs exposés d'altitude.

Indices de risque : 5 très fort - 4 fort - 3 marqué - 2 limité - 1 faible -- En noir : les pentes les plus dangereuses

Stabilité du manteau neigeux

Situation avalancheuse typique : neige ventée

Déclenchements provoqués : Quelques nouvelles plaques se forment encore ce jeudi sous le vent de Nord à Nord-Est qui reste fort. Ces instabilités se retrouvent même loin des crêtes/cols et en tous versants mais plutôt au-dessus de 1800/2000m. Les plaques restent localisées et peu nombreuses, la plupart du temps peu épaisses, mais peuvent être réactives au passage d'un unique skieur. Quelques coulées de petites tailles possibles sous les skis l'après-midi en versants ensoleillés sous 1800m.

Observables : Encore du transport en cours, accumulations et congères nombreuses, neige sculptée par le vent.

Départs spontanés : Dans les pentes chargées par le vent (généralement en large Sud) de rares ruptures de plaques de tailles petites à moyennes restent possible en altitude au-dessus de 2000/2200m. L'après-midi, de petites coulées sont possibles sous les rochers qui prennent le soleil à l a faveur de quelques éclaircies.

Qualité de la neige

Qualification de l'enneigement : L'enneigement est bon à basse altitude, et même très bon dés 1800 / 2000m mais avec des répartitions assez hétérogènes à cause du vent. Peu de sous couche sous 1700m en plein Sud.

Limites skiables : Vers 1000 / 1200m selon le versant, avec prudence en Sud / sous les sapins

Qualité de la neige jeudi : Neige souvent travaillée voire cartonnée par le vent. Les crêtes et versants Nord exposés au vent sont souvent pelés, faisant ressortir une vieille neige dure / croûtée. On peut encore retrouver quelques combes en poudreuse, à priori plutôt celles abritées du vent de Nord (où la neige aura été soufflée, ou parfois croûtée par la pluie).

Aperçu météo pour le jeudi 02 avril

nuit	matin	après-midi	soir

Plutot belle journée en montagne avec souvent des nuages sur les reliefs. Possibles averses faibles l'après-midi.

Pluie-Neige				
Iso 0 °C	1 300 m	1 500 m	1 700 m	1 700 m
Vent 1500 m	↙ 25 km/h	↓ 30 km/h	↓ 40 km/h	↙ 35 km/h
Vent 2000 m	↙ 35 km/h	↙ 50 km/h	↙ 50 km/h	↙ 50 km/h

Épaisseur de neige hors-piste

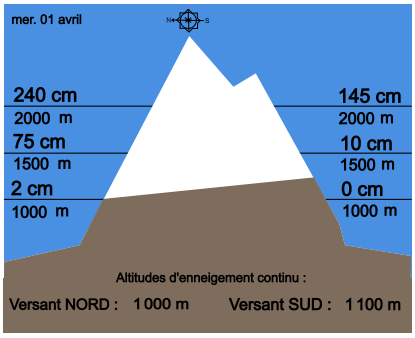

Précipitations à 1800 m

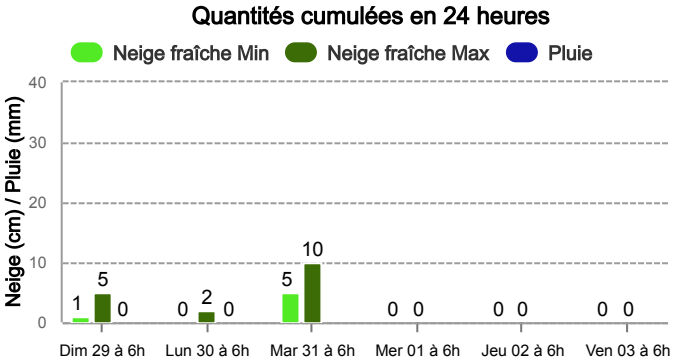

Tendance du vendredi 03 avril

2

Indice de risque limité

Risque stable sans évolution.

Pour consulter la vigilance en cours, veuillez vous rendre sur le site https://vigilance.meteofrance.fr/fr

Météo-France - 73 avenue de Paris, 94165 Saint-Mandé cedex - Contact : contact@meteo.fr

Rédigé par Météo-France avec la contribution des observateurs du réseau nivo-météorologiques. Partenariat : ANMSM (Maires de Stations de Montagne), DSF (Domaines Skiables de France), ADSP (Directeurs de Pistes et de la Sécurité des Stations de Sports d'Hiver) et autres acteurs de la montagne.

Bulletin neige & avalanches par téléphone au

0 892 68 10 20 Service 0,35 € / min + prix appel

RÉPUBLIQUE FRANÇAISE
Liberté Égalité Fraternité

METEO FRANCE
À VOS CÔTÉS, DANS UN CLIMAT QUI CHANGE

Bulletin d'estimation du risque d'avalanche

(valable en dehors des pistes balisées et ouvertes)

MASSIF : Vercors

Rédigé le mercredi 1 avril 2026 à 17h

Conditions nivo-météo des 7 derniers jours

	jeu. 26/03				ven. 27/03				sam. 28/03				dim. 29/03				lun. 30/03				mar. 31/03				mer. 01/04			
	03h	09h	15h	21h	03h	09h	15h	21h	03h	09h	15h	21h	03h	09h	15h	21h	03h	09h	15h	21h	03h	09h	15h	21h	03h	09h	15h	21h
Météo																												
Vent (km/h)	65	70	75	70	70	75	70	55	70	80	70	85	90	70	60	65	70	70	85	95	90	90	90	65	60	45	50	30
à 2000m																												
Vent (km/h)	60	65	70	60	60	70	65	50	60	75	65	80	85	65	55	60	60	65	70	75	80	70	70	45	45	30	40	25
à 1500m																												

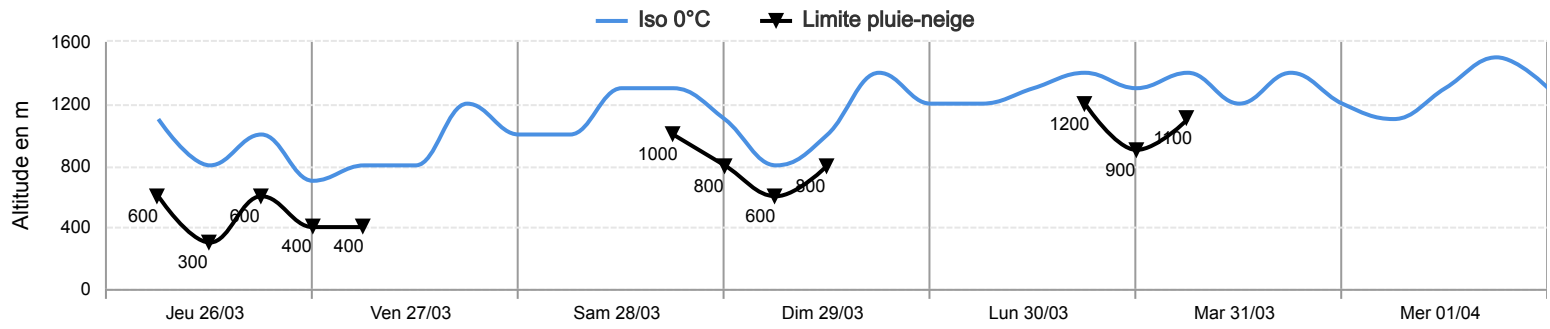

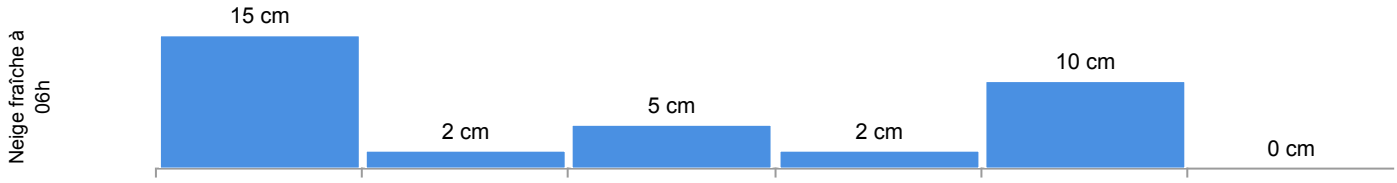

Risque d'avalanche	jeu. 26/03	ven. 27/03	sam. 28/03	dim. 29/03	lun. 30/03	mar. 31/03	mer. 01/04
	4	3	2	2	2	2	2

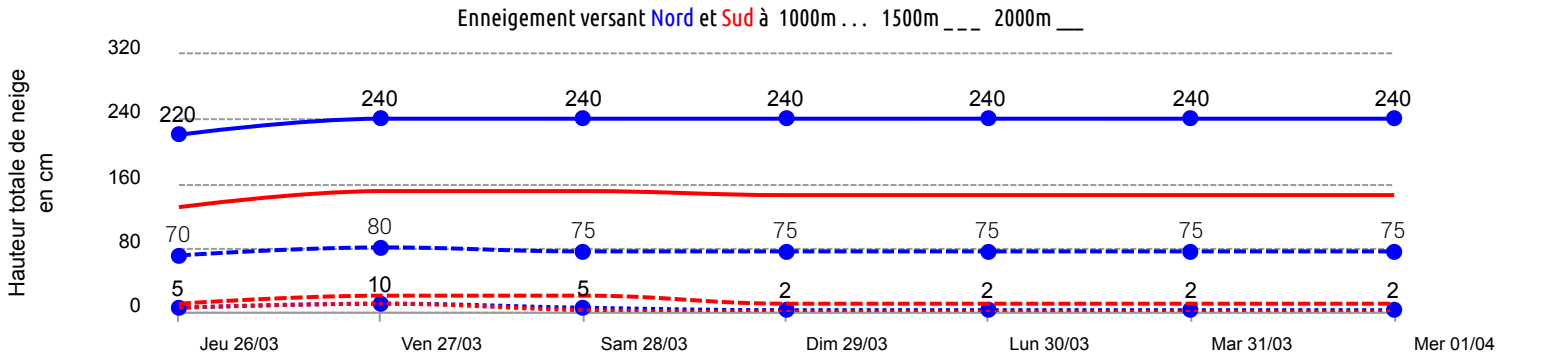

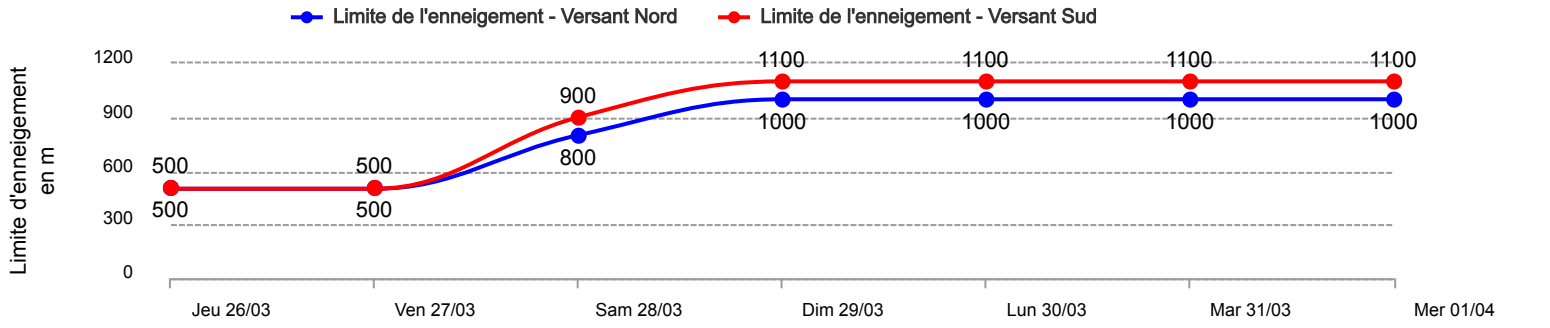

Pour consulter la vigilance en cours, veuillez vous rendre sur le site https://vigilance.meteofrance.fr/fr

Météo-France - 73 avenue de Paris, 94165 Saint-Mandé cedex - Contact : contact@meteo.fr

Rédigé par Météo-France avec la contribution des observateurs du réseau nivo-météorologiques. Partenariat : ANMSM (Maires de Stations de Montagne), DSF (Domaines Skiables de France), ADSP (Directeurs de Pistes et de la Sécurité des Stations de Sports d'Hiver) et autres acteurs de la montagne.

Bulletin neige & avalanches par téléphone au
0 892 68 10 20 Service 0,35 € / min + prix appel